L1T1-CON-CAL-FR-0120 - B1 : 1000x707mm

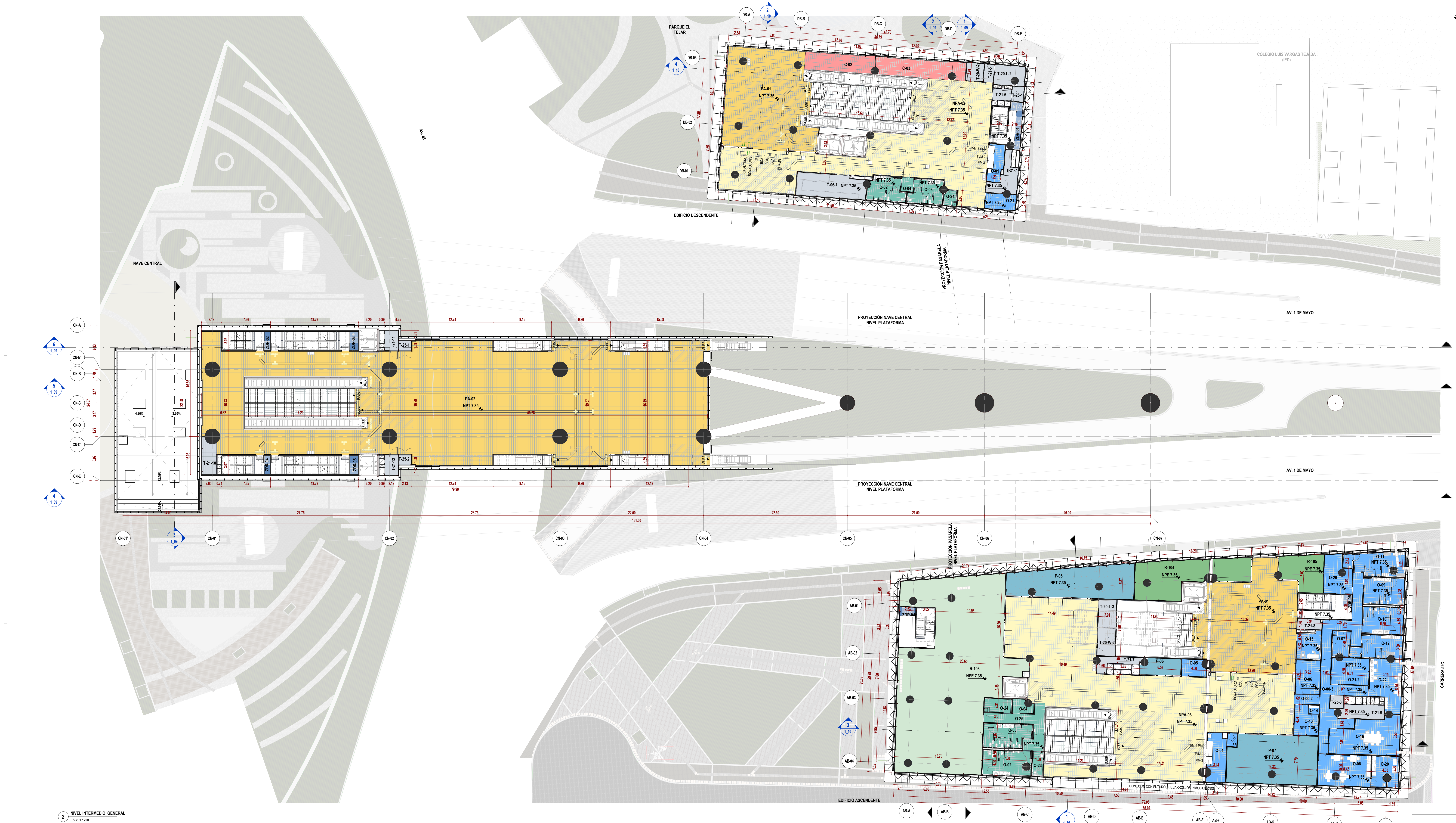

2 NIVEL INTERMEDIO_GENERAL
ESC: 1 : 200

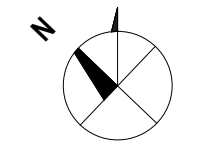

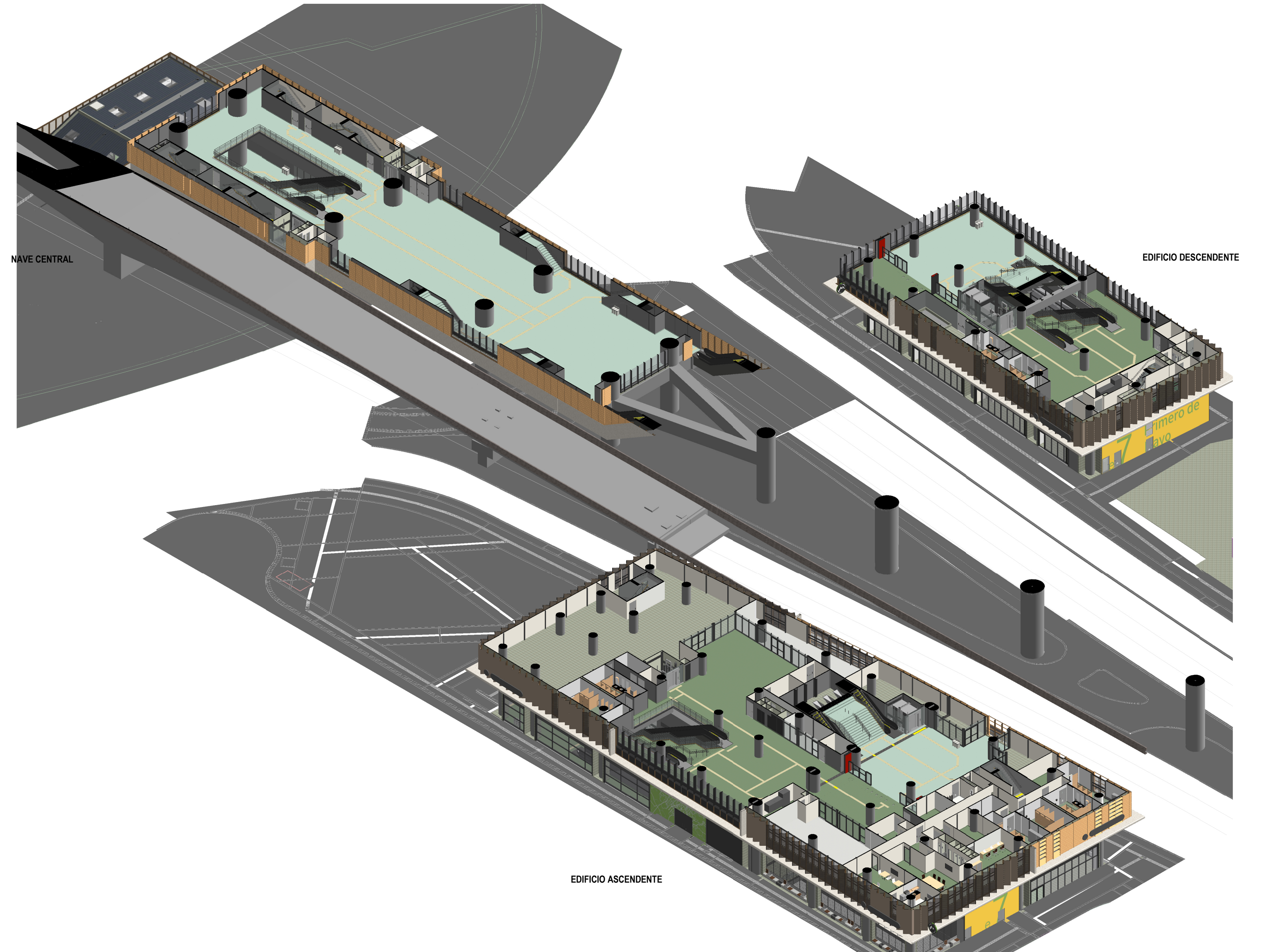

1 3D_NIVEL INTERMEDIO_GENERAL
ESC: N/A

LOCALIZACIÓN

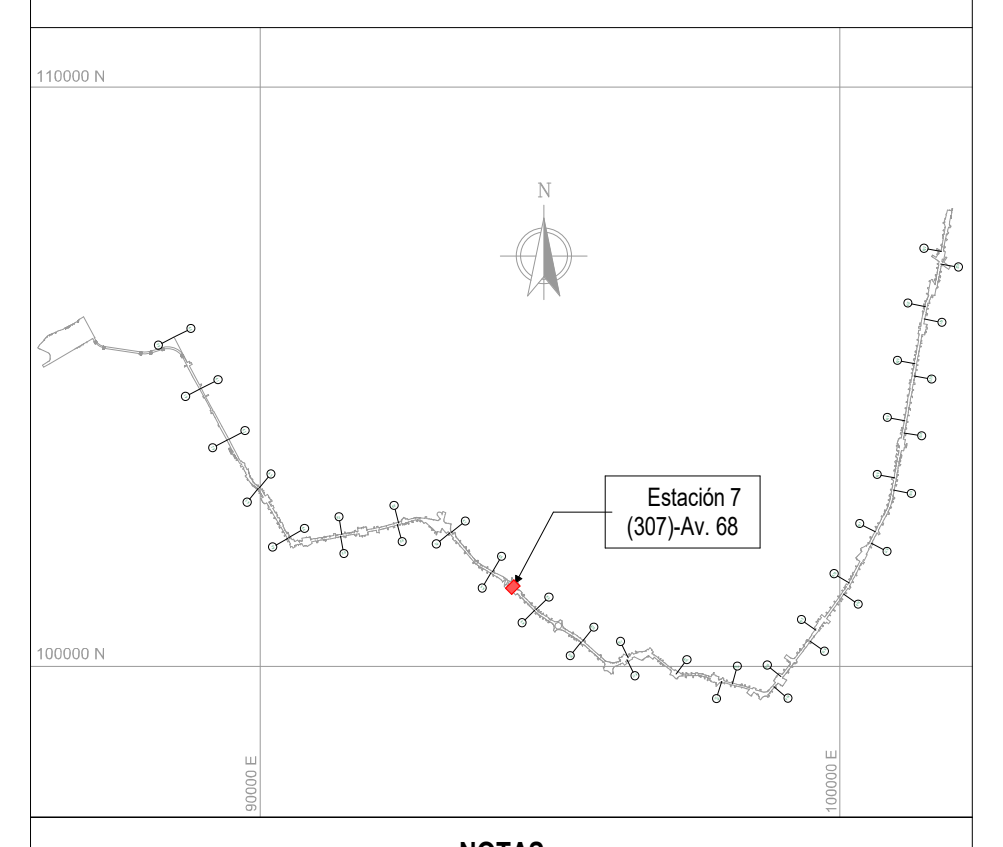

NOTAS

01 TODAS LAS DIMENSIONES ESTÁN CONFIGURADAS EN METROS A MENOS QUE SE INDIQUE UNA UNIDAD DE MEDIDA DIFERENTE.

02 TODAS LAS MEDIDAS, UBICACIÓN Y NIVELES DEBEN VERIFICARSE EN EL LUGAR DE CONSTRUCCIÓN.

03 EL NIVEL DE ACCESO AL EDIFICIO PL 01 CORRESPONDE AL +0,00 DE LA ESTACIÓN Y REFERENCIA AL NIVEL 2557.05 M.S.N.M.

04 LOS NOMBRES ESPECIFICOS DE LAS ÁREAS PUEDEN SER CONSULTADAS EN EL PLANO NO. 3 Ó EN LAS VISTAS EN PLANTA.

05 LOS COLORES QUE SE MUESTRAN EN LOS PLANOS COMO PROYECCIÓN DE ELEMENTOS ARQUITECTÓNICOS COMO CUBIERTAS FACHADAS MUROS ETC. NO REPRESENTAN LA MATERIALIDAD Y REALIDAD DE ACABADOS DEL PROYECTO, SOLO SON INDICATIVOS PARA REALIZAR UNA CORRECTA LECTURA DE LA PLANIMETRÍA.

06 LAS ESCALERAS ELÉCTRICAS INDICAN SU SENTIDO CON LA SIGUIENTE NOMENCLATURA: "SUBE" Y "BAJA".

07 SE DEBEN REVISAR LOS NIVELES ESTRUCTURALES PARA NIVEL DE ACCESO PL_01 Y SUBNIVELES, PL_02 (INTERMEDIO), PL_03 (PLATAFORMA) CON LA PLANIMETRÍA DE PLACAS ESTRUCTURALES EN LOS ENTREGABLES L1T1-1200-307-CON-ED-EST-PL-0018,19 Y L1T1-1300-407-CON-ED-EST-PL-0026, 30, 76, RESPECTIVAMENTE. EL NIVEL ESTRUCTURAL (NE) REFERENCIA LOS ESPACIOS DONDE SE DEBE ACONDICIONAR EL ACABADO DE PISO SEGÚN CORRESPONDA, CON LOS NIVELES DE PISO TERMINADO (NPT). LOS NIVELES PROYECTADOS DE EMPATE (NPE) EN LAS ÁREAS DE SERVICIOS ADICIONALES, REFERENCIAN LA ADECUACIÓN DE LOS DESNIVELES EN ESTAS ÁREAS; QUEDA COMO RESPONSABILIDAD DEL LOCATARIO DEFINIR Y ACONDICIONAR ESTE ACABADO DE PISO (NPE) EN LÍNEA CON EL NIVEL (NPT) DE ESPACIOS COLINDANTES. EL NIVEL ESTRUCTURAL (NE) SE ENCUENTRA A (- 0.10M) POR DEBAJO DE LOS NIVELES DE PISO TERMINADO (NPT) Y LOS NIVELES PROYECTADOS DE EMPATE (NPE) MARCADOS EN LA PLANIMETRÍA.

- ARQ_PL_00 = SÓTANO / NPT -6.70m
- ARQ_PL_00.1 = SÓTANO BRT / NPT -6.12m
- ARQ_PL_00.1 = ACCESO / NPT -0.70m
- ARQ_PL_00.2 = ACCESO / NPT -0.55m
- ARQ_PL_00.3 = ACCESO / NPT -0.45m
- ARQ_PL_00.4 = ACCESO / NPT -0.30m
- ARQ_PL_01 = ACCESO / NPT 0.00m
- ARQ_PL_02 = INTERMEDIO / NPT 7.35m
- ARQ_PL_02.2 = TOPE DE RIEL (TOR) / NPT 15.25m
- ARQ_PL_03 = PLATAFORMA / NPT 16.39m
- ARQ_PL_04 = CUBIERTA EDIFICACIONES / NPT 22.99m
- ARQ_PL_05 = CUBIERTA NAVE CENTRAL / NPT 25.70m

CONVENCIONES

- LÍMITE DE INTERVENCIÓN
- HUELLA APÉNDICE TÉCNICO
- MURO DIVISORIO
- PROYECCIÓN NIVEL SUPERIOR

🟩	SERVICIOS ADICIONALES - ÁREA NO PAGA	🟨	ÁREA NO PAGA
🟩	SERVICIOS ADICIONALES - ÁREA PAGA	🟨	ÁREA PAGA
🟩	SERVICIO PÚBLICO	🟦	ÁREA PÚBLICA
🟦	ZONA DE REFUGIO	⬜	ÁREA TÉCNICA
🟥	ÁREA CULTURAL	🟦	ÁREA OPERATIVA

TABLA DE ÁREAS ÚTILES (NIVEL INTERMEDIO)

CÓDIGO	NOMBRE	ÁREA (m²)	DEPARTAMENTO
EDIFICIO ASCENDENTE			
ARQ_PL_02_INTERMEDIO			
NPA-03	ÁREA NO PAGA	598.84	ÁREA NO PAGA
O-00-1	CIRCULACIÓN ÁREAS OPERATIVAS	3.13	ÁREA OPERATIVA
O-00-2	CIRCULACIÓN ÁREAS OPERATIVAS	5.88	ÁREA OPERATIVA
O-00-3	CIRCULACIÓN ÁREAS OPERATIVAS	71.93	ÁREA OPERATIVA
O-01	VENTA AUTOMÁTICA DE BOLETOS	21.76	ÁREA OPERATIVA
O-02	BAÑOS PÚBLICOS DE HOMBRES	28.04	SERVICIO PÚBLICO
O-03	BAÑOS PÚBLICOS DE MUJERES	26.10	SERVICIO PÚBLICO
O-04	CONTROL DE ACCESO BAÑOS PÚBLICOS	5.84	SERVICIO PÚBLICO
O-05	LOCAL DE INFORMACIÓN	9.42	ÁREA OPERATIVA
O-06	OFICINA DEL SUPERVISOR DE LA ESTACIÓN	20.02	ÁREA OPERATIVA
O-07	CUARTO DE LIMPIEZA	10.54	ÁREA OPERATIVA
O-08	SALA DE DESCANSO PARA EMPLEADOS	39.25	ÁREA OPERATIVA
O-09	BAÑOS EMPLEADOS HOMBRES	26.52	ÁREA OPERATIVA
O-10	BAÑOS EMPLEADOS MUJERES	26.63	ÁREA OPERATIVA
O-11	VESTIDORES EMPLEADOS HOMBRES	31.59	ÁREA OPERATIVA
O-12	VESTIDORES EMPLEADOS MUJERES	25.58	ÁREA OPERATIVA
O-13	LOCAL DE POLICÍA	15.55	ÁREA OPERATIVA
O-14	CALABOZO	2.09	ÁREA OPERATIVA
O-15	LOCAL PRIMEROS AUXILIOS	16.18	ÁREA OPERATIVA
O-16	SALA DE REUNIONES	55.97	ÁREA OPERATIVA
O-20	SALA DE LACTANCIA	19.44	ÁREA OPERATIVA
O-21-2	ALMACENAMIENTO DE LA ESTACIÓN	23.94	ÁREA OPERATIVA
O-22	OFICINA DE MANTENIMIENTO	35.05	ÁREA OPERATIVA
O-23	BAÑO PÚBLICO - FAMILIAR	6.42	SERVICIO PÚBLICO
O-24	CUARTO DE LIMPIEZA DE BAÑOS PÚBLICOS	9.18	SERVICIO PÚBLICO
O-25	BAÑO PÚBLICO - CORREDOR OPERACIONAL	26.77	SERVICIO PÚBLICO
O-26	ALMACENAMIENTO DE BASURAS METRO	22.46	ÁREA OPERATIVA
P-05	BIBLIOMETRO	89.00	ÁREA PÚBLICA
P-06	ESPACIO IPES (INSTITUTO PARA LA ECONOMÍA SOCIAL)	15.09	ÁREA PÚBLICA
P-07	SALÓN MÚLTIPLE EMB	103.57	ÁREA PÚBLICA
PA-01	ÁREA PAGA	226.99	ÁREA PAGA
R-103	SERVICIOS ADICIONALES - ÁREA DE SERVICIO	435.91	SERVICIOS ADICIONALES - ÁREA NO PAGA
R-104	SERVICIOS ADICIONALES - ÁREA DE SERVICIO	78.48	SERVICIOS ADICIONALES - ÁREA PAGA
R-105	SERVICIOS ADICIONALES - ÁREA DE SERVICIO	30.12	SERVICIOS ADICIONALES - ÁREA PAGA
T-20-L-3	MEDIDORES (LUZ)	11.98	ÁREA TÉCNICA
T-20-W-2	MEDIDORES (AGUA)	11.91	ÁREA TÉCNICA
T-21-7	ÁREA DE INSPECCIÓN	8.80	ÁREA TÉCNICA
T-21-8	ÁREA DE INSPECCIÓN	5.90	ÁREA TÉCNICA
T-21-9	ÁREA DE INSPECCIÓN	14.44	ÁREA TÉCNICA
T-25-3	NODO DE ACCESO DE TELECOMUNICACIONES	3.86	ÁREA TÉCNICA
ZDR-04	ZONA DE REFUGIO (PMR)	3.36	ZONA DE REFUGIO
ZDR-05	ZONA DE REFUGIO (PMR)	2.43	ZONA DE REFUGIO

TABLA DE ÁREAS ÚTILES (NIVEL INTERMEDIO)

CÓDIGO	NOMBRE	ÁREA (m²)	DEPARTAMENTO
EDIFICIO DESCENDENTE			
ARQ_PL_02_INTERMEDIO			
C-02	ÁREAS DE USO CULTURAL	29.49	ÁREA CULTURAL
C-03	ÁREAS DE USO CULTURAL	37.71	ÁREA CULTURAL
NPA-02	ÁREA NO PAGA	357.36	ÁREA NO PAGA
O-01	VENTA AUTOMÁTICA DE BOLETOS	13.77	ÁREA OPERATIVA
O-02	BAÑOS PÚBLICOS DE HOMBRES	20.12	SERVICIO PÚBLICO
O-03	BAÑOS PÚBLICOS DE MUJERES	18.61	SERVICIO PÚBLICO
O-04	CONTROL DE ACCESO BAÑOS PÚBLICOS	4.00	SERVICIO PÚBLICO
O-21-2	ALMACENAMIENTO DE LA ESTACIÓN	11.13	ÁREA OPERATIVA
O-24	CUARTO DE LIMPIEZA DE BAÑOS PÚBLICOS	4.69	SERVICIO PÚBLICO
PA-01	ÁREA PAGA	202.46	ÁREA PAGA
T-06-1	LOCAL SECUNDARIO DE TABLEROS	36.89	ÁREA TÉCNICA
T-20-L-2	MEDIDORES (LUZ)	13.45	ÁREA TÉCNICA
T-20-W-2	MEDIDORES (AGUA)	7.41	ÁREA TÉCNICA
T-21-5	ÁREA DE INSPECCIÓN	4.20	ÁREA TÉCNICA
T-21-6	ÁREA DE INSPECCIÓN	5.21	ÁREA TÉCNICA
T-21-7	ÁREA DE INSPECCIÓN	15.91	ÁREA TÉCNICA
T-25-1	NODO DE ACCESO DE TELECOMUNICACIONES	4.17	ÁREA TÉCNICA
ZDR-01	ZONA DE REFUGIO (PMR)	8.00	ZONA DE REFUGIO
NAVE CENTRAL			
ARQ_PL_02_INTERMEDIO			
PA-02	ÁREA PAGA	1191.23	ÁREA PAGA
T-21-10	ÁREA DE INSPECCIÓN	11.94	ÁREA TÉCNICA
T-21-11	ÁREA DE INSPECCIÓN	6.18	ÁREA TÉCNICA
T-21-12	ÁREA DE INSPECCIÓN	6.18	ÁREA TÉCNICA
T-25-1	NODO DE ACCESO DE TELECOMUNICACIONES	2.92	ÁREA TÉCNICA
T-25-2	NODO DE ACCESO DE TELECOMUNICACIONES	2.92	ÁREA TÉCNICA
ZDR-02	ZONA DE REFUGIO (PMR)	2.58	ZONA DE REFUGIO
ZDR-03	ZONA DE REFUGIO (PMR)	3.87	ZONA DE REFUGIO
ZDR-04	ZONA DE REFUGIO (PMR)	2.58	ZONA DE REFUGIO
ZDR-05	ZONA DE REFUGIO (PMR)	3.88	ZONA DE REFUGIO
TOTAL NIVEL INTERMEDIO		4254.81	

TABLA DE ÁREAS ÚTILES POR DEPARTAMENTO (NIVEL INTERMEDIO)

DEPARTAMENTO	ÁREA (m²)
EDIFICIO ASCENDENTE	
ARQ_PL_02_INTERMEDIO	
SERVICIO PÚBLICO	102.35
SERVICIOS ADICIONALES - ÁREA NO PAGA	435.91
SERVICIOS ADICIONALES - ÁREA PAGA	108.60
ZONA DE REFUGIO	5.79
ÁREA NO PAGA	598.84
ÁREA OPERATIVA	482.92
ÁREA PAGA	226.99
ÁREA PÚBLICA	207.66
ÁREA TÉCNICA	56.89
EDIFICIO DESCENDENTE	
ARQ_PL_02_INTERMEDIO	
SERVICIO PÚBLICO	47.43
ZONA DE REFUGIO	8.00
ÁREA CULTURAL	67.20
ÁREA NO PAGA	357.36
ÁREA OPERATIVA	24.90
ÁREA PAGA	202.46
ÁREA TÉCNICA	87.23
NAVE CENTRAL	
ARQ_PL_02_INTERMEDIO	
ZONA DE REFUGIO	12.91
ÁREA PAGA	1191.23
ÁREA TÉCNICA	30.15
TOTAL NIVEL INTERMEDIO	4254.81

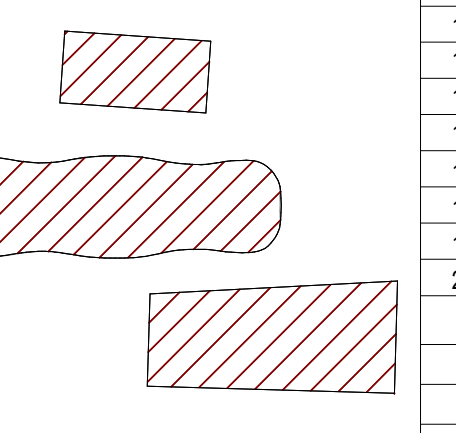

PLANO CLAVE ESTACIÓN 7

VÁLIDO PARA CONSTRUCCIÓN
20-03-26

No.	PLANOS DE REFERENCIA	REV.
No.	**MODELO BIM DE REFERENCIA**	**REV.**
1	L1T1-1100-207-CON-ED-EST-MO-0001.rvt	V00
2	L1T1-1100-307-CON-ED-EST-MO-0001.rvt	V00
3	L1T1-1150-207-CON-ED-EST-MO-0001.rvt	V00
4	L1T1-1150-307-CON-ED-EST-MO-0001.rvt	V00
5	L1T1-1200-307-CON-ED-EST-MO-0001.rvt	V00
6	L1T1-1300-407-CON-ED-EST-MO-0001.rvt	V00
7	L1T1-1300-407-CON-ED-EST-MO-0002.rvt	V00
8	L1T1-1310-407-CON-ED-EST-MO-0001.rvt	V00
9	L1T1-1410-307-CON-ED-MEC-MO-0001.rvt	V00
10	L1T1-1420-307-CON-ED-MEC-MO-0001.rvt	V00
11	L1T1-2410-501-CON-ED-EST-MO-0001.rvt	V00
12	L1T1-2410-502-CON-ED-EST-MO-0001.rvt	V00
13	L1T1-2430-407-CON-ED-EST-MO-0001.rvt	V00
14	L1T1-5160-307-CON-ED-EST-MO-0001.rvt	V00
15	L1T1-5160-307-CON-ED-ARQ-MO-0001.rvt	V00
16	L1T1-5300-307-CON-ED-MEC-MO-0001.rvt	V00
17	L1T1-5600-307-CON-ED-INS-MO-0001.rvt	V00
18	L1T1-1270-307-CON-ED-ARQ-MO-0011.rvt	V00
19	L1T1-1330-407-CON-ED-ARQ-MO-0011.rvt	V00
20	L1T1-1330-407-CON-ED-ARQ-MO-0012.rvt	V00
No.	**PAQUETE DE TRABAJO DE REFERENCIA**	**REV.**
1	XREF-URBANISM_CONTEXT_ST07.rvt	
2	XREF-SECONDARY-STRUCTURE-ST07.rvt	

0 2 10m
1:200

METRO BOGOTÁ
GCS Consorcio Consultores PMO Bogotá
CONSORCIO SUPERVISOR PLMB
CHEC

DISEÑÓ:
REN ZHENHUA
Licencia de Arq.nivel I (China): 1101735-614

REVISÓ:
CARLOS MAURICIO BARRETO BARBOSA
Mat.: A4012012-14139353

APROBÓ:
DIEGO ERNESTO DUEÑAS
Mat.: 25202-53876 CND

DIBUJÓ:
EQUIPO CHEC

REVISIÓN No.	FECHA	DESCRIPCIÓN	REVISÓ	APROBÓ	APROBACIÓN CLIENTE
V01	20/03/2026	EMITIDO PARA CONSTRUCCIÓN	C.M.B.B	D.E.D	
V00	27/01/2025	REVISIÓN NO OBJETADA - EMITIDO PARA CONSTRUCCIÓN	F.B.R	E.O.M	
VFF	04/10/2024	EMITIDO PARA REVISIÓN Y COMENTARIOS DEL CLIENTE E INTERVENTORÍA - INCLUYE COMENTARIOS /(AJUSTES V3)	F.B.R	E.O.M	
VEE	11/06/2024	EMITIDO PARA REVISIÓN Y COMENTARIOS DEL CLIENTE E INTERVENTORÍA - INCLUYE COMENTARIOS /(AJUSTES V2)	F.B.R	E.O.M	
VDD	18/12/2022	EMITIDO PARA REVISIÓN Y COMENTARIOS DEL CLIENTE E INTERVENTORÍA - INCLUYE COMENTARIOS /(AJUSTES)	J.E.M	M.B.M	
VCC	02/06/2022	EMITIDO PARA REVISIÓN Y COMENTARIOS DEL CLIENTE E INTERVENTORÍA - INCLUYE COMENTARIOS /(ENTREGA 90%)	J.E.M	M.B.M	
VBB	06/12/2021	EMITIDO PARA REVISIÓN Y COMENTARIOS DEL CLIENTE E INTERVENTORÍA	J.E.M	M.B.M	
VA0	30/06/2021	EMITIDO PARA COMENTARIOS INTERNOS - EMISIÓN PRELIMINAR PARA COMENTARIOS	J.E.M	M.B.M	

METRO LÍNEA 1

METRO LÍNEA 1
CONTRATO DE CONCESIÓN No. 163 DE 2019

PROYECTO PRIMERA LÍNEA DEL METRO DE BOGOTÁ - TRAMO 1

DIRECTOR DE INTERVENTORÍA:
JAVIER DESCARGA N.
Mat.:25202-68697 CND

ESPECIALISTA INTERVENTORÍA:
CARLOS ALBERTO HOYOS SOTO
Mat.:A25072000-14251682

FECHA:
MARZO 2026

INFRAESTRUCTURA VIAL
ARQUITECTURA

ESTACIÓN METRO 7 (AV 68)
GENERAL
VISTA EN PLANTA Y 3D - NIVEL INTERMEDIO

PLANCHA No: L1T1-0000-307-CON-ED-ARQ-PL-0001_06_V01
ARCHIVO: L1T1-0000-307-CON-ED-ARQ-MO-0001_V00.rvt
ESCALA: INDICADA
FECHA: JUNIO 2021
REVISIÓN No. V01
PLANO No. 06 DE 107