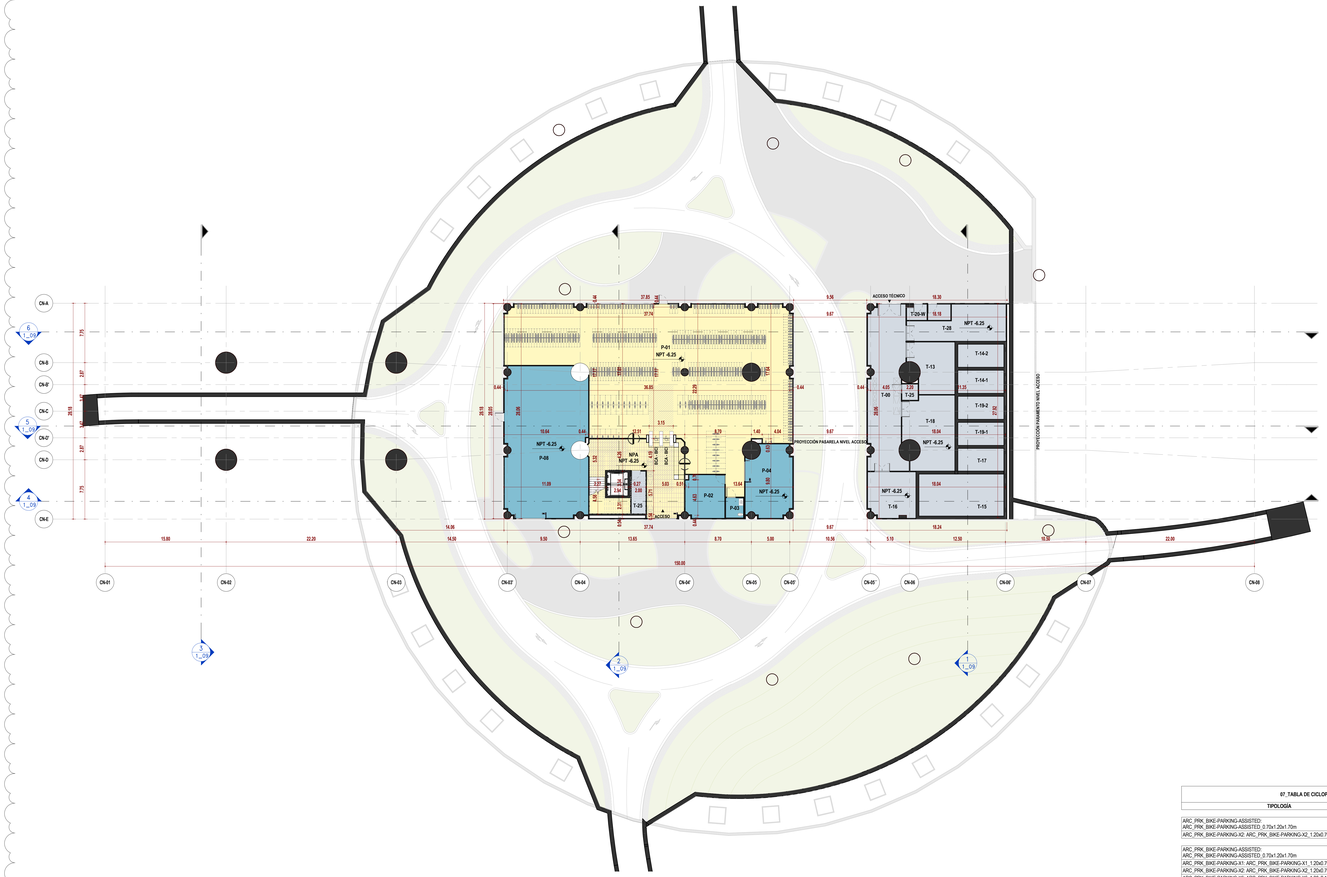
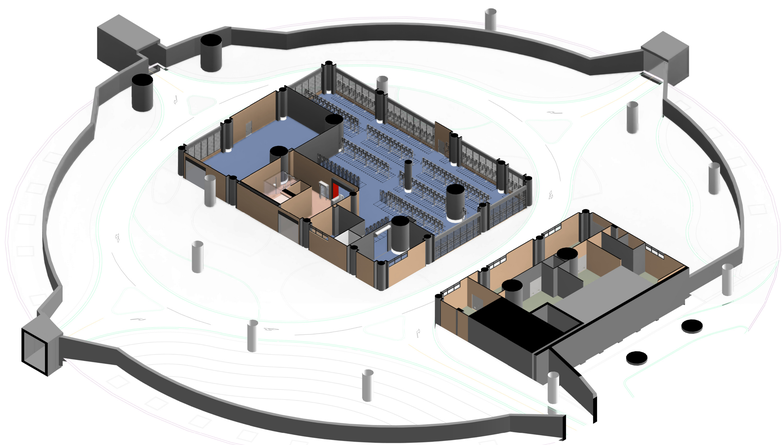
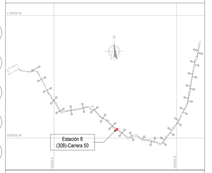


2 NIVEL SÓTANO_NAVE CENTRAL
ESC: 1: 200



1 3D_NIVEL SÓTANO_NAVE CENTRAL
ESC: N/A

LOCALIZACIÓN



NOTAS

01 TODAS LAS DIMENSIONES ESTÁN CONFIGURADAS EN METROS A MENOS QUE SE INDIQUE UNA UNIDAD DE MEDIDA DIFERENTE.

02 TODAS LAS MEDIDAS, UBICACIÓN Y NIVELES DEBEN VERIFICARSE EN EL LUGAR DE CONSTRUCCIÓN.

03 EL NIVEL DE ACCESO AL EDIFICIO PL 01 CORRESPONDE AL +0.00 DE LA ESTACIÓN Y REFERENCIA AL NIVEL 2550.58 M.S.N.M

04 LOS NOMBRES ESPECÍFICOS DE LAS ÁREAS PUEDEN SER CONSULTADAS EN EL PLANO NO. 3 O EN LAS VISTAS EN PLANTA.

05 LOS COLORES QUE SE MUESTRAN EN LOS PLANOS COMO PROYECCIÓN DE ELEMENTOS ARQUITECTÓNICOS COMO CUBIERTAS FACHADAS MUROS ETC. NO REPRESENTAN LA MATERIALIDAD Y REACABOS DEL PROYECTO, SOLO SON INDICATIVOS PARA REALIZAR UNA CORRECTA LECTURA DE LA PLANIMETRÍA.

06 EN LOS NIVELES DE ACCESO COMPRENDIDOS DESDE PL 00.1 A PL 01 SE DEBEN REVISAR LOS NIVELES ESTRUCTURALES CON LA PLANIMETRÍA CORRESPONDIENTE A LAS PLACAS ESTRUCTURALES QUE SE ENCUENTRA EN LOS ENTREGABLES LTT-1000-309-CON-ED-STR-PL-0000 AL LTT-1000-309-CON-ED-STR-PL-0005. EN LOS NIVELES PL_02 (INTERMEDIO) Y PL_03 (MEZZANINE) NO HAY PLACAS ESTRUCTURALES. LOS NIVELES SE DEFINEN POR ESBALTE DE LOS NIVELES DE PISO TERMINADO (NPT) MARCADOS EN LA PLANIMETRÍA. A EXCEPCIÓN DE LOS NIVELES ESPECIFICADOS PARA LOCALES COMERCIALES, LOS CUALES SE UBICAN SOBRE PLACAS ESTRUCTURALES REFERENCIADOS COMO NIVEL ESTRUCTURAL (NE) Y ES RESPONSABILIDAD DEL LOCATARIO DEFINIR Y CALCULAR EL ACABADO DE PISO PARA EMPATAR CON EL NIVEL DE PISO TERMINADO (NPT) DEL ESPACIO INMEDIATO A SU ACCESO.

- ARC_PL_00 = SÓTANO | NPT -6.25
- ARC_PL_01 = ACCESO | NPT 0.00
- ARC_PL_02 = INTERMEDIO | NPT 7.60
- ARC_PL_02.1 = PLANO DE INTERIOR VIGA CAJÓN | NPT 10.60
- ARC_PL_02.2 = PLANO DE RIEL (TOR) | NPT 15.95
- ARC_PL_03 = PLATAFORMA | NPT 17.05
- ARC_PL_05 = CUBIERTA NAVE CENTRAL | NPT 26.42

CONVENCIONES

- CADE
- COMERCIAL ÁREA NO PAGA
- COMERCIAL ÁREA PAGA
- MUSEO
- SERVICIO PÚBLICO
- ZONA DE REFUGIO
- ÁREA CULTURAL
- ÁREA DE TAQUILLAS BRT
- ÁREA JARDÍN
- ÁREA NO PAGA
- AREA OPERACIONAL
- ÁREA PAGA
- ÁREA PÚBLICA
- ÁREA TÉCNICA

VDO CAMBIOS EFECTUADOS:
CAMBIO DE LAYOUT

07_TABLA DE CICLOPARQUEADEROS

TIPOLOGÍA	CANTIDAD	USUARIOS
ARC_PRK_BIKE-PARKING-ASSISTED	1	EMPLEADOS
ARC_PRK_BIKE-PARKING-ASSISTED_0.75x1.20x1.70m		
ARC_PRK_BIKE-PARKING-X2_ARC_PRK_BIKE-PARKING-X2_1.20x0.70x2.40m	4	EMPLEADOS
	5	
ARC_PRK_BIKE-PARKING-ASSISTED	49	VISITANTE
ARC_PRK_BIKE-PARKING-ASSISTED_0.75x1.20x1.70m		
ARC_PRK_BIKE-PARKING-X1_ARC_PRK_BIKE-PARKING-X1_1.20x0.70x2.40m	20	VISITANTE
ARC_PRK_BIKE-PARKING-X2_ARC_PRK_BIKE-PARKING-X2_1.20x0.70x2.40m	94	VISITANTE
ARC_PRK_BIKE-PARKING-X8_ARC_PRK_BIKE-PARKING-X8_1.20x0.70x2.40m	372	VISITANTE
	456	
TOTAL CUPOS	500	

06_TABLA DE ÁREAS (NIVEL SÓTANO_NAVE CENTRAL)

CÓDIGO	NOMBRE	ÁREA (m²)	DEPARTAMENTO
ARC_PL_00			
P-01	ÁREA CICLO-PARQUEADEROS	686.02	ÁREA PÚBLICA
P-02	ÁREA OPERATIVA CICLO-PARQUEADEROS	28.38	ÁREA PÚBLICA
P-03	BAÑO OPERADOR CICLO-PARQUEADEROS	6.09	ÁREA PÚBLICA
P-04	TALLER DE BICICLETAS	53.16	ÁREA PÚBLICA
P-06	ESPACIO CARGA DE VEHICULOS ELÉCTRICOS	204.56	ÁREA PÚBLICA
T-00	CIRCULACIÓN TÉCNICA	97.50	ÁREA TÉCNICA
T-13	CUARTO DE BOMBAS DE SUMINISTRO DE AGUA	36.19	ÁREA TÉCNICA
T-14-1	TANQUE DE SUMINISTRO DE AGUA	18.00	ÁREA TÉCNICA
T-14-2	TANQUE DE SUMINISTRO DE AGUA	18.00	ÁREA TÉCNICA
T-15	TANQUE SISTEMA CONTRA INCENDIOS (RCI)	60.72	ÁREA TÉCNICA
T-16	CUARTO DE BOMBAS DE ROCIADORES	36.62	ÁREA TÉCNICA

08_TABLA DE ÁREAS (NIVEL SÓTANO_NAVE CENTRAL)

CÓDIGO	NOMBRE	ÁREA (m²)	DEPARTAMENTO
T-17	TANQUE DE RECUPERACIÓN DE AGUAS LLUVIAS	17.70	ÁREA TÉCNICA
T-18	CUARTO DE BOMBAS DE RECUPERACIÓN DE AGUAS LLUVIAS Y EQUIPO DE FILTRACIÓN	59.52	ÁREA TÉCNICA
T-19-1	TANQUE DE AGUA TRATADA	18.00	ÁREA TÉCNICA
T-19-2	TANQUE DE AGUA TRATADA	18.00	ÁREA TÉCNICA
T-20-L	MEDIDORES (LUZ)	6.30	ÁREA TÉCNICA
T-20-W	MEDIDORES (AGUA)	5.20	ÁREA TÉCNICA
T-25	NODO DE ACCESO DE TELECOMUNICACIONES	10.47	ÁREA TÉCNICA
T-26	NODO DE ACCESO DE TELECOMUNICACIONES	4.41	ÁREA TÉCNICA
T-28	CUARTO DE MAQUINAS DE ESTACIÓN DE BOMBEO	49.84	ÁREA TÉCNICA
TOTAL NIVEL SÓTANO		1434.70	

05_TABLA DE ÁREAS POR DEPARTAMENTO (NIVEL SÓTANO)

DEPARTAMENTO	ÁREA (m²)
ÁREA NO PAGA	0.00
ÁREA PÚBLICA	978.21
ÁREA TÉCNICA	456.49
TOTAL NIVEL	1434.70

PLANO CLAVE ESTACIÓN 08

No.	PLANOS DE REFERENCIA	REV.

No.	MODELO BIM DE REFERENCIA	REV.
1	LTT-1100-208-CON-ED-EST-MO-0001.rvt	VCC
2	LTT-1100-209-CON-ED-EST-MO-0001.rvt	VCC
3	LTT-1100-308-CON-ED-EST-MO-0001.rvt	VCC
4	LTT-1150-208-CON-ED-EST-MO-0001.rvt	VCC
5	LTT-1150-209-CON-ED-EST-MO-0001.rvt	VCC
6	LTT-1150-308-CON-ED-EST-MO-0001.rvt	VCC
7	LTT-1410-308-CON-ED-MEC-MO-0001.rvt	VCC
8	LTT-1420-308-CON-ED-HID-MO-0001.rvt	VCC
9	LTT-1420-961-CON-ED-MEC-MO-0001.rvt	VCC

No.	PAQUETE DE TRABAJO DE REFERENCIA	REV.
1	XREF-URBANISM_CONTEXT_ST08.rvt	

0 2 10m
1:200

METRO BOGOTÁ | GCS Consorcio Consultores PMO Bogotá | CONSORCIO SUPERVISOR PLMB | wsp

DISEÑO	APROBÓ	REVISIÓN No.	FECHA	DESCRIPCIÓN	REVISÓ	APROBÓ	APROBACIÓN CLIENTE
ALBERTO ARANDA Mat.: A2507199-79785641	MÓNICA F. BEDOYA M. Mat.: 252521-70140 CND						
REVISÓ	DIBUJÓ						
JAIRO ESPEJO M. Mat.: 252522-20801 CND	EQUIPO WSP	VCC	17/07/2023	EMITIDO PARA REVISIÓN Y COMENTARIOS DEL CLIENTE E INTERVENTORÍA - INCLUYE COMENTARIOS (JULIO/23)	J.E.M	M.B.M	
		VCC	20/06/2023	EMITIDO PARA REVISIÓN Y COMENTARIOS DEL CLIENTE E INTERVENTORÍA - INCLUYE COMENTARIOS (ENTREGA 90%)	J.E.M	M.B.M	
		VBB	06/12/2021	EMITIDO PARA REVISIÓN Y COMENTARIOS DEL CLIENTE E INTERVENTORÍA	J.E.M	M.B.M	
		VAC	30/06/2021	EMITIDO PARA COMENTARIOS INTERNOS - EMISIÓN PRELIMINAR PARA COMENTARIOS	J.E.M	M.B.M	

METRO LÍNEA 1

DIRECTOR DE INTERVENTORÍA: JAVIER DESCARGA N. Mat.:2520226697 CND

ESPECIALISTA INTERVENTORÍA: MARÍA ALEJANDRA SANCHEZ H. INT: PAH138382-RES.No.34 DE 2021

FECHA: JULIO 2023

METRO LÍNEA 1
CONTRATO DE CONCESIÓN No. 163 DE 2019
PROYECTO PRIMERA LÍNEA DEL METRO DE BOGOTÁ - TRAMO 1

INFRAESTRUCTURA VIAL
ARQUITECTURA
ESTACIÓN 08 - CARRERA 50
NAVE CENTRAL
VISTA EN PLANTA - NIVEL SÓTANO 01

PLANCHA No.: LTT1-0000-308-CON-ED-ARQ-PL-0001_04_VDO
ARCHIVO: LTT1-0000-308-CON-ED-ARQ-MO-0001_VCC.rvt
ESCALA: INDICADA
FECHA: JUNIO 2021
REVISIÓN No.: VDO
PLANO No.: 04 DE 32