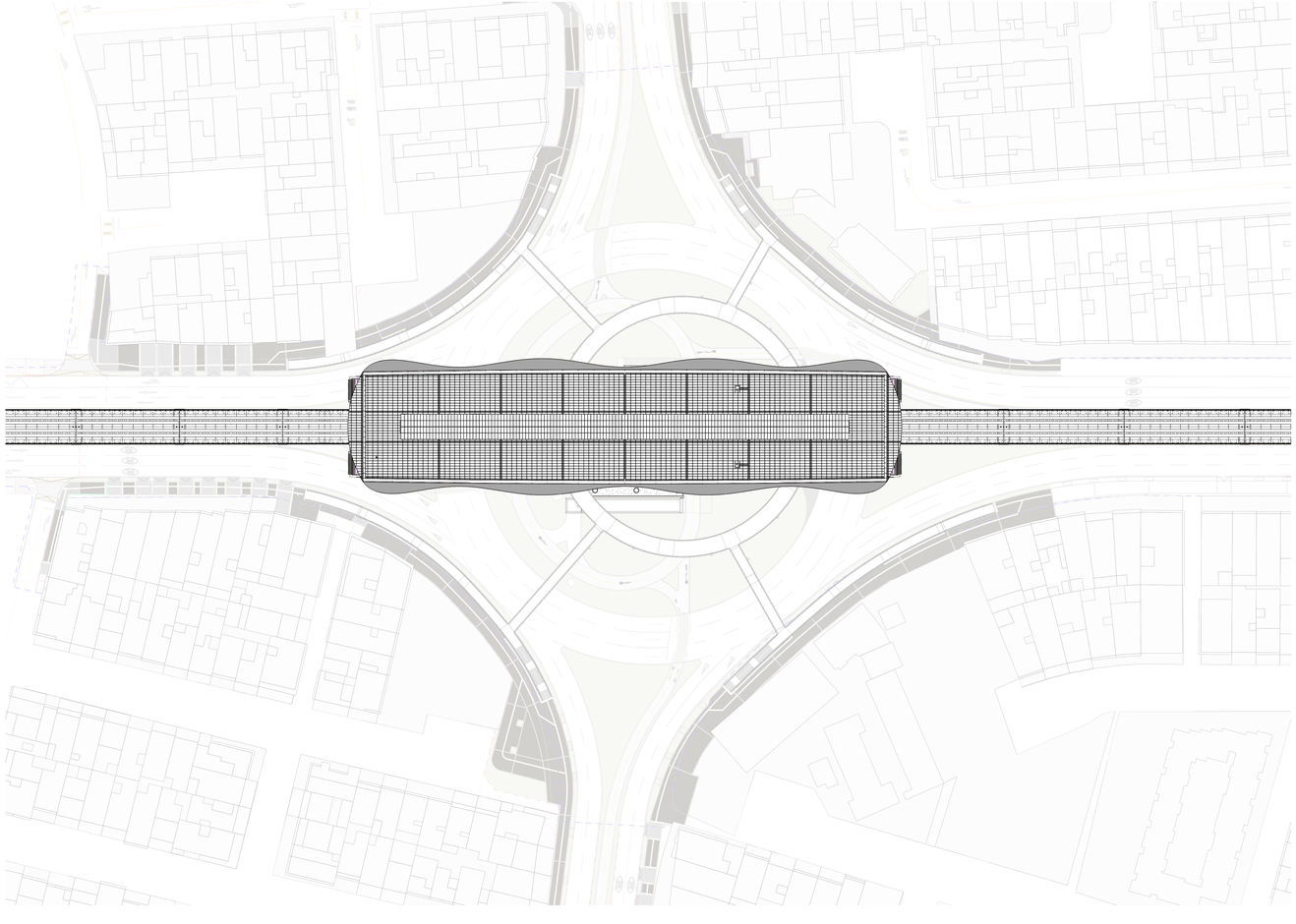
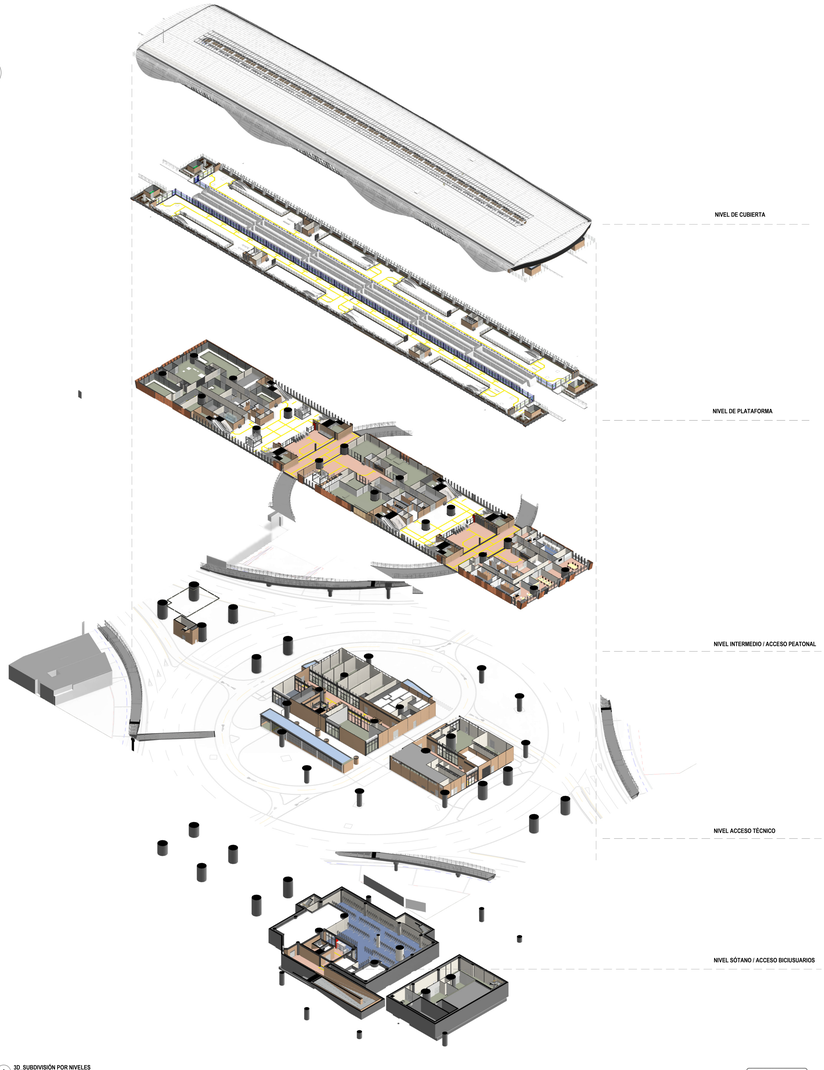


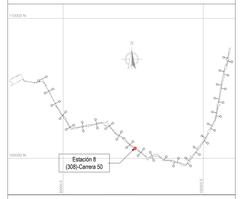
2 NIVEL CUBIERTA_NAVE CENTRAL
ESC: 1 : 500



1 3D_SUBDIVISIÓN POR NIVELES
ESC: N/A

VALIDO PARA CONSTRUCCION
12/12/2025

LOCALIZACIÓN



NOTAS

01 TODAS LAS DIMENSIONES ESTÁN CONFIGURADAS EN METROS A MENOS QUE SE INDIQUE UNA UNIDAD DE MEDIDA DIFERENTE.
02 TODAS LAS MEDIDAS, UBICACIÓN Y NIVELES DEBEN VERIFICARSE EN EL LUGAR DE CONSTRUCCIÓN.
03 EL NIVEL DE ACCESO AL EDIFICIO PL 01 CORRESPONDE AL +0.00 DE LA ESTACIÓN Y REFERENCIA AL NIVEL 2555.85 M.S.N.M
04 LOS EJES DEBEN VERIFICARSE EN LA VISTA EN PLANTA DE LOS PLANOS ARQUITECTÓNICOS.
05 LOS COLORES QUE SE MUESTRAN EN LOS PLANOS COMO PROYECCIÓN DE ELEMENTOS ARQUITECTÓNICOS COMO CUBIERTAS FACHADAS MUROS ETC. NO REPRESENTAN LA MATERIALIDAD Y REALIDAD DE ACABADOS DEL PROYECTO, SOLO SON INDICATIVOS PARA REALIZAR UNA CORRECTA LECTURA DE LA PLANIMETRÍA.
06 VER LOS PLANOS DE LAS ESPECIALIDADES ESPECIFICAS PARA EL DISEÑO DE LAS ZONAS EXTERIORES DE LAS ESTACIONES METRO EN LOS QUE SE ENCUENTRAN DETALLES DE URBANISMO, PAISAJISMO, PASOS PEATONALES Y VIAS.

- ARC_PL_00 = SÓTANO / ACCESO BICIUSUARIOS / NPT -6.25
- ARC_PL_01 = ACCESO TÉCNICO / NPT 0.00
- ARC_PL_02 = INTERMEDIO / ACCESO PEATONAL / NPT 7.00
- ARC_PL_02.1 = PLACA INFERIOR VIGA CAJÓN / NPT 13.82
- ARC_PL_02.2 = TOPE DE RIEL (TOR) / NPT 15.95
- ARC_PL_03 = PLATAFORMA / NPT 17.09
- ARC_PL_05 = CUBIERTA NAVE CENTRAL / NPT 26.42

CONVENCIONES

- LÍMITE DE INTERVENCIÓN
- HUELLA APÉNDICE TÉCNICO
- MURO DIVISORIO
- PROYECCIÓN NIVEL SUPERIOR

No.	PLANOS DE REFERENCIA	REV.

No.	MODELO BIM DE REFERENCIA	REV.
1	L1T1-1100-208-CON-ED-EST-MO-0001.rvt	V00
2	L1T1-1100-209-CON-ED-EST-MO-0001.rvt	V00
3	L1T1-1100-308-CON-ED-EST-MO-0001.rvt	V00
4	L1T1-1150-208-CON-ED-EST-MO-0001.rvt	V00
5	L1T1-1150-209-CON-ED-EST-MO-0001.rvt	V00
6	L1T1-1150-308-CON-ED-EST-MO-0001.rvt	V00
7	L1T1-5200-308-CON-ED-EST-MO-0001.rvt	V00
8	L1T1-1410-308-CON-ED-MEC-MO-0001.rvt	V00
9	L1T1-1420-308-CON-ED-MEC-MO-0001.rvt	V00
10	L1T1-2420-561-CON-ED-EST-MO-0001.rvt	V00
11	L1T1-5160-308-CON-ED-EST-MO-0001.rvt	V00
12	L1T1-5160-308-CON-ED-ARQ-MO-0001.rvt	V00
13	L1T1-5300-308-CON-ED-MEC-MO-0001.rvt	V00

No.	PAQUETE DE TRABAJO DE REFERENCIA	REV.
1	XREF-URBANISM_CONTEXT_5708.rvt	
2	XREF-SECONDARY-STRUCTURE-5708.rvt	

0 5 25m
1:200

METRO BOGOTÁ | GCS Consorcio Consultores PMO Bogotá | CONSORCIO SUPERVISOR PLMB | wsp

DISEÑO: SANTIAGO ANDRES DAVID GUZMÁN Mat.: A4132020211-1010178190
REVISÓ: FREDDY BAUTISTA R Mat: 25202-092831 CND (Digitally signed by Bautista Rondón, Freddy Fernando)
APROBÓ: MAURICIO MEJIA RESTREPO Mat.: 25202-72411 CND (Firmado digitalmente por MAURICIO MEJIA RESTREPO Fecha: 2025.12.12 21:47:00 -05'00')
DIBUJÓ: EQUIPO WSP

REVISIÓN No.	FECHA	DESCRIPCIÓN	REVISÓ	APROBÓ	APROBACIÓN CLIENTE
V05	12/12/2025	REVISIÓN NO OBJETADA - EMITIDO PARA CONSTRUCCIÓN	F.B.R	M.M.R	
V04	01/10/2025	EMITIDO PARA REVISIÓN Y COMENTARIOS DEL CLIENTE E INTERVENTORIA - INCLUYE COMENTARIOS (AJUSTE)	F.B.R	M.M.R	
V03	19/07/2025	EMITIDO PARA REVISIÓN Y COMENTARIOS DEL CLIENTE E INTERVENTORIA	F.B.R	M.M.R	
V02	04/07/2025	EMITIDO PARA COMENTARIOS INTERNOS - EMISIÓN PRELIMINAR PARA COMENTARIOS	F.B.R	M.M.R	

METRO LÍNEA 1

DIRECTOR DE INTERVENTORÍA: JAVIER DESCARGA N. Mat: 25202-68697 CND
ESPECIALISTA INTERVENTORÍA: MARIA AUXILIADORA SANCHEZ SERMEÑO INT: PAH130362-RES.NO.34 DE 2024

METRO LÍNEA 1
CONTRATO DE CONCESIÓN No. 163 DE 2019
PROYECTO PRIMERA LÍNEA DEL METRO DE BOGOTÁ - TRAMO 1

FECHA: DICIEMBRE 2025

INFRAESTRUCTURA VIAL
ARQUITECTURA
ESTACIÓN METRO 8 (CARRERA 50)
NAVE CENTRAL
VISTA EN PLANTA - NIVEL CUBIERTA - AXONOMETRÍA GENERAL

PLANO No.: L1T1-0000-308-CON-ED-ARQ-PL-0022_08_V00
ESCALA: INDICADA
REVISIÓN No.: V00
PLANO No.: 08 DE 47
ARCHIVO: L1T1-0000-308-CON-ED-ARQ-MO-0002_V00.rvt
FECHA: JULIO 2025

L1T1-CON-CAL-PR-0120 -81:1471x1726mm