L1T1-CON-CAL-FR-0120 - B1 : 1000x707mm

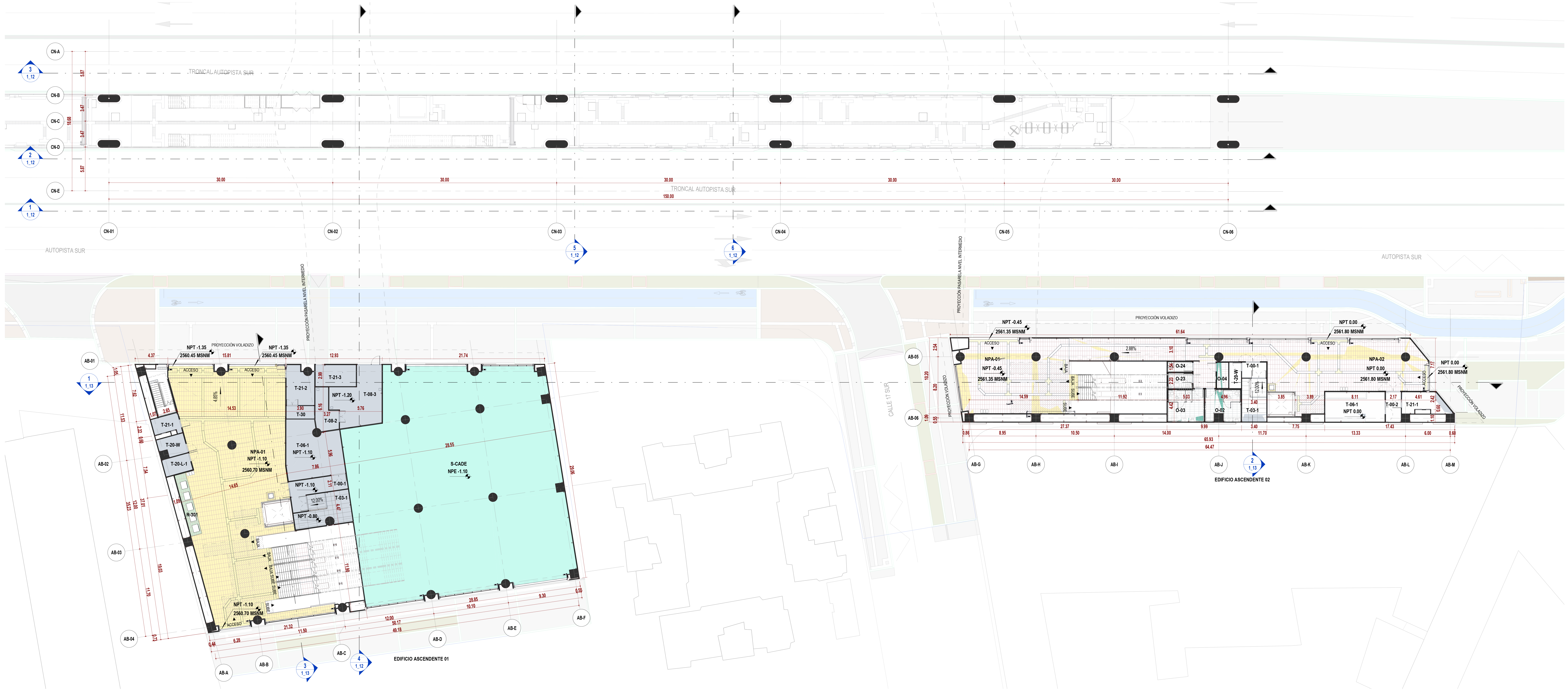

NP N
TRONCAL AUTOPISTA SUR
CN-A
CN-B
CN-C
CN-D
CN-E
CN-01
CN-02
CN-03
CN-04
CN-05
CN-06
3 1_12
2 1_12
1 1_12
5 1_12
6 1_12
5.87
3.47
18.68
30.00
150.00
AUTOPISTA SUR
PROYECCIÓN PASARELA NIVEL INTERMEDIO
NPT -1.35
2560.45 MSNM
PROYECCIÓN VOLADIZO
ACCESO
AB-01
AB-02
AB-03
AB-04
AB-A
AB-B
AB-C
AB-D
AB-E
AB-F
1 1_13
3 1_13
4 1_12
4.37
15.81
12.93
21.74
4.85%
14.53
T-21-1
T-20-W
T-20-L-1
R-301
NPA-01
NPT -1.10
2560.70 MSNM
T-21-2
T-21-3
T-30
NPT -1.20
T-08-3
T-08-2
T-06-1
NPT -1.10
T-00-1
T-03-1
12.00%
NPT -0.80
BAJA
SUBE
S-CADE
NPE -1.10
28.55
29.06
28.85
10.10
9.30
0.55
12.00
50.17
49.18
21.32
11.50
6.28
0.44
35.23
12.00
37.01
19.03
11.70
11.90
EDIFICIO ASCENDENTE 01
CALLE 17 SUR
NPT -0.45
2561.35 MSNM
NPT 0.00
2561.80 MSNM
61.64
2.88%
AB-05
AB-06
NPA-01
NPT -0.45
2561.35 MSNM
O-24
O-23
O-04
T-20-W
T-00-1
O-03
O-02
T-03-1
NPA-02
NPT 0.00
2561.80 MSNM
T-06-1
NPT 0.00
T-00-2
T-21-1
27.37
9.99
3.40
7.75
17.43
0.86
8.95
10.50
14.00
11.70
13.33
6.00
0.60
65.93
64.47
AB-G
AB-H
AB-I
AB-J
AB-K
AB-L
AB-M
2 1_13
EDIFICIO ASCENDENTE 02

② **NIVEL ACCESO_EDIFICIO ASCENDENTE 01 Y EDIFICIO ASCENDENTE 02**
ESC: 1 : 200

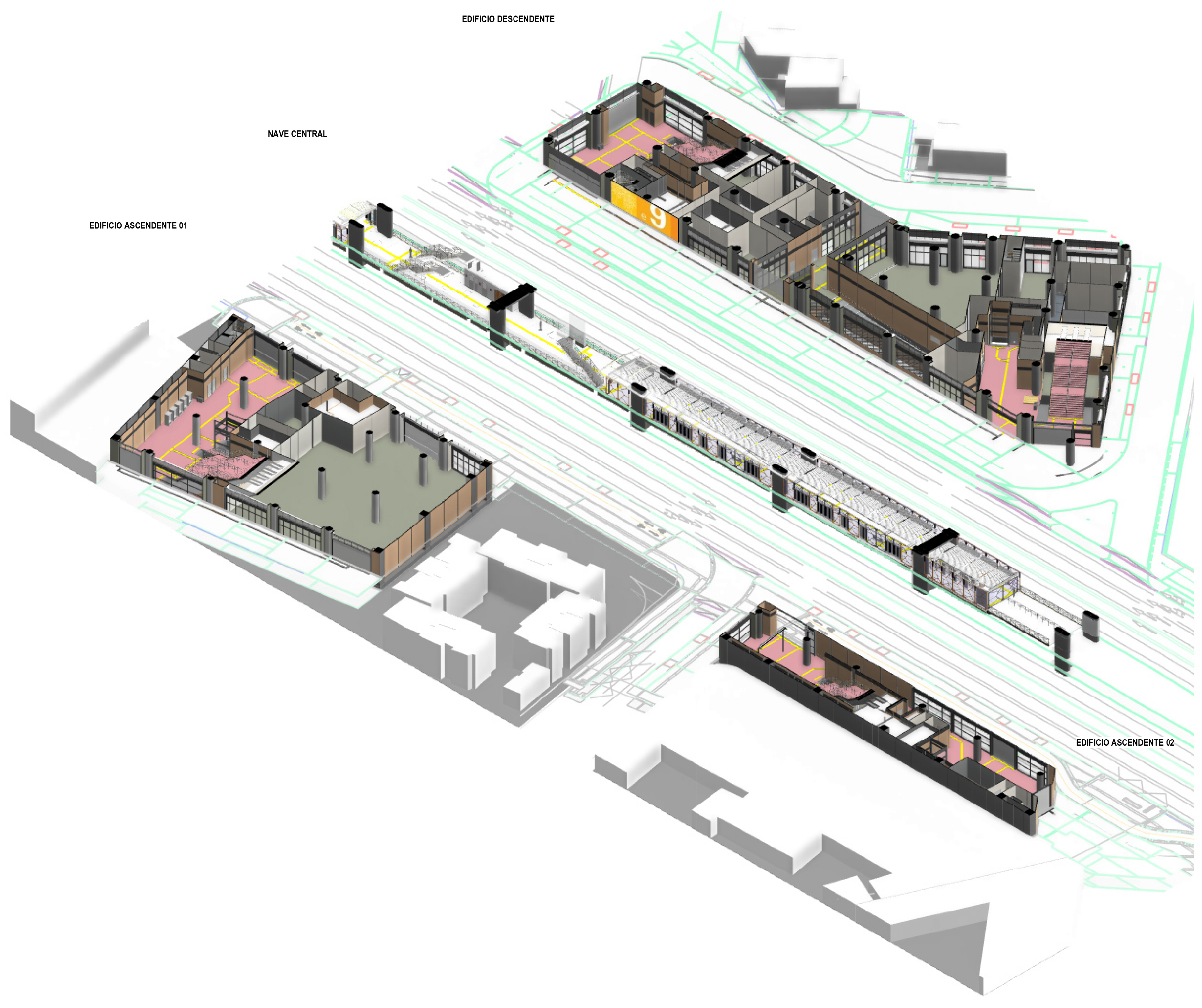

EDIFICIO DESCENDENTE
NAVE CENTRAL
EDIFICIO ASCENDENTE 01
EDIFICIO ASCENDENTE 02
9

① **3D_NIVEL ACCESO_GENERAL**
ESC: N/A

CÓDIGO	NOMBRE	ÁREA (m²)	DEPARTAMENTO
TABLA DE ÁREAS ÚTILES (NIVEL ACCESO_EDIFICIOS ASCENDENTES)			
EDIFICIO ASCENDENTE 01			
ARQ_PL_00.4_ACCESO			
NPA-01	ÁREA NO PAGA	413.82	ÁREA NO PAGA
T-21-2	ÁREA DE INSPECCIÓN	18.09	ÁREA TÉCNICA
T-30	SISTEMA PROTECCIÓN CONTRA INCENDIO ENEL	6.40	ÁREA TÉCNICA
		438.31	
ARQ_PL_00.5_ACCESO			
T-08-2	CENTRO DE TRANSFORMACIÓN ENEL-CODENSA (CT)_CUARTO BAJA TENSIÓN	13.53	ÁREA TÉCNICA
T-08-3	CENTRO DE TRANSFORMACIÓN ENEL-CODENSA (CT)_CUARTO MEDIA TENSIÓN	43.54	ÁREA TÉCNICA
T-21-3	ÁREA DE INSPECCIÓN	15.54	ÁREA TÉCNICA
		72.62	
ARQ_PL_00.6_ACCESO			
R-301	SERVICIOS ADICIONALES - MÁQUINAS EXPENDEDORAS/CAJEROS AUTOMÁTICOS	12.83	SERVICIOS ADICIONALES - ÁREA NO PAGA
S-CADE	S-CADE	811.20	CADE
T-00-1	CIRCULACIÓN TÉCNICA	19.81	ÁREA TÉCNICA
T-03-1	LOCAL SECUNDARIO DE TELECOMUNICACIONES	28.13	ÁREA TÉCNICA
T-06-1	LOCAL SECUNDARIO DE TABLEROS	51.59	ÁREA TÉCNICA
T-20-L-1	MEDIDORES (LUZ)	8.39	ÁREA TÉCNICA
T-20-W	MEDIDORES (AGUA)	8.58	ÁREA TÉCNICA
		940.54	
ARQ_PL_01_ACCESO			
T-21-1	ÁREA DE INSPECCIÓN	8.19	ÁREA TÉCNICA
		8.19	
EDIFICIO ASCENDENTE 02			
ARQ_PL_00.7_ACCESO			
NPA-01	ÁREA NO PAGA	193.61	ÁREA NO PAGA
		193.61	
ARQ_PL_01_ACCESO			
NPA-02	ÁREA NO PAGA	196.93	ÁREA NO PAGA
O-02	BAÑOS PÚBLICOS DE HOMBRES	19.01	SERVICIO PÚBLICO
O-03	BAÑOS PÚBLICOS DE MUJERES	20.62	SERVICIO PÚBLICO
O-04	CONTROL DE ACCESO BAÑOS PÚBLICOS	5.42	SERVICIO PÚBLICO
O-23	BAÑO PÚBLICO - FAMILIAR	6.35	SERVICIO PÚBLICO
O-24	CUARTO DE LIMPIEZA DE BAÑOS PÚBLICOS	4.52	SERVICIO PÚBLICO
T-00-1	CIRCULACIÓN TÉCNICA	6.64	ÁREA TÉCNICA
T-00-2	CIRCULACIÓN TÉCNICA	8.22	ÁREA TÉCNICA
T-03-1	LOCAL SECUNDARIO DE TELECOMUNICACIONES	19.09	ÁREA TÉCNICA
T-06-1	LOCAL SECUNDARIO DE TABLEROS	31.76	ÁREA TÉCNICA
T-20-W	MEDIDORES (AGUA)	5.47	ÁREA TÉCNICA
T-21-1	ÁREA DE INSPECCIÓN	15.33	ÁREA TÉCNICA
		339.36	
TOTAL NIVEL ACCESO EDIFICIOS ASCENDENTES		1992.63	

TABLA DE ÁREAS ÚTILES POR DEPARTAMENTO (NIVEL ACCESO EDIFICIOS ASCENDENTES)

DEPARTAMENTO	ÁREA (m²)
SERVICIOS ADICIONALES - ÁREA NO PAGA	12.83
ÁREA NO PAGA	804.37
SERVICIO PÚBLICO	55.92
CADE	811.20
ÁREA TÉCNICA	308.30
TOTAL NIVEL ACCESO EDIFICIOS ASCENDENTES	1992.63

PLANO CLAVE ESTACIÓN 9

LOCALIZACIÓN

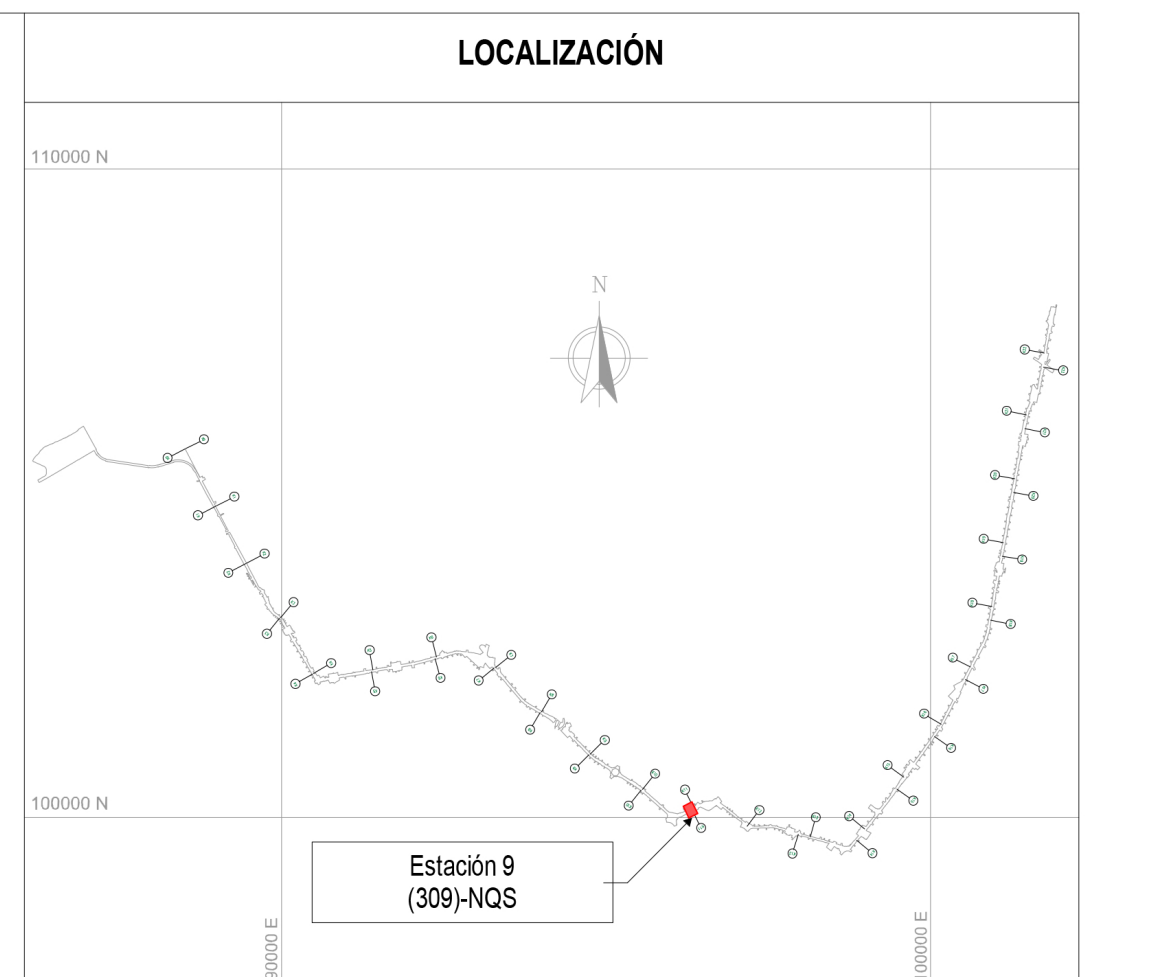

110000 N
100000 N
90000 E
100000 E
N
Estación 9
(309)-NQS

NOTAS

01 TODAS LAS DIMENSIONES ESTÁN CONFIGURADAS EN METROS A MENOS QUE SE INDIQUE UNA UNIDAD DE MEDIDA DIFERENTE.

02 TODAS LAS MEDIDAS, UBICACIÓN Y NIVELES DEBEN VERIFICARSE EN EL LUGAR DE CONSTRUCCIÓN.

03 EL NIVEL DE ACCESO AL EDIFICIO PL 01 CORRESPONDE AL +0,00 DE LA ESTACIÓN Y REFERENCIA AL NIVEL 2561.80 M.S.N.M

04 LOS NOMBRES ESPECÍFICOS DE LAS ÁREAS PUEDEN SER CONSULTADAS EN EL PLANO NO. 3 Ó EN LAS VISTAS EN PLANTA.

05 LOS COLORES QUE SE MUESTRAN EN LOS PLANOS COMO PROYECCIÓN DE ELEMENTOS ARQUITECTÓNICOS COMO CUBIERTAS FACHADAS MUROS ETC. NO REPRESENTAN LA MATERIALIDAD Y REALIDAD DE ACABADOS DEL PROYECTO, SOLO SON INDICATIVOS PARA REALIZAR UNA CORRECTA LECTURA DE LA PLANIMETRÍA.

06 LAS ESCALERAS ELÉCTRICAS INDICAN SU SENTIDO CON LA SIGUIENTE NOMENCLATURA: "SUBE" Y "BAJA".

07 SE DEBEN REVISAR LOS NIVELES ESTRUCTURALES PARA NIVEL DE ACCESO PL_01 Y SUBNIVELES, PL_02 (INTERMEDIO), PL_03 (PLATAFORMA) CON LA PLANIMETRÍA DE PLACAS ESTRUCTURALES EN LOS ENTREGABLES L1T1-1300-409-CON-ED-EST-PL-0079, 80, 81, 101, 102, 103, 125, 126, 127, 128, 129, 130, 131, 151, 152, RESPECTIVAMENTE. EL NIVEL ESTRUCTURAL (NE) REFERENCIA LOS ESPACIOS DONDE SE DEBE ACONDICIONAR EL ACABADO DE PISO SEGÚN CORRESPONDA, CON LOS NIVELES DE PISO TERMINADO (NPT). LOS NIVELES PROYECTADOS DE EMPATE (NPE) EN LAS ÁREAS DE SERVICIOS ADICIONALES, REFERENCIAN LA ADECUACIÓN DE LOS DESNIVELES EN ESTAS ÁREAS; QUEDA COMO RESPONSABILIDAD DEL LOCATARIO DEFINIR Y ACONDICIONAR ESTE ACABADO DE PISO (NPE) EN LÍNEA CON EL NIVEL (NPT) DE ESPACIOS COLINDANTES. EL NIVEL ESTRUCTURAL (NE) SE ENCUENTRA A (- 0.10M) POR DEBAJO DE LOS NIVELES DE PISO TERMINADO (NPT) Y LOS NIVELES PROYECTADOS DE EMPATE (NPE) MARCADOS EN LA PLANIMETRÍA.

- ARQ_PL_00 = SÓTANO	/NPT -8.40	- ARQ_PL_00.7 = ACCESO	/NPT -0.45
- ARQ_PL_00.1 = ACCESO	/NPT -2.40	- ARQ_PL_01 = ACCESO	/NPT 0.00
- ARQ_PL_00.2 = ACCESO	/NPT -2.25	- ARQ_PL_02 = INTERMEDIO	/NPT 6.60
- ARQ_PL_00.3 = ACCESO	/NPT -2.05	- ARQ_PL_02.2 = TOPE DE RIEL	/NPT 14.20
- ARQ_PL_00.4 = ACCESO	/NPT -1.80	- ARQ_PL_03 = PLATAFORMA	/NPT 15.34
- ARQ_PL_00.5 = ACCESO	/NPT -1.30	- ARQ_PL_04 = CUB. EDIFICACIONES	/NPT 21.94
- ARQ_PL_00.6 = ACCESO	/NPT -1.10	- ARQ_PL_05 = CUB. NAVE CENTRAL	/NPT 24.59

CONVENCIONES

- ▬ ▬ LÍMITE DE INTERVENCIÓN
- ─ ─ HUELLA APÉNDICE TÉCNICO
- ▬ MURO DIVISORIO
- ─ ─ PROYECCIÓN NIVEL SUPERIOR

🟩	CADE	🟨	ÁREA NO PAGA
🟩	SERVICIOS ADICIONALES ÁREA NO PAGA	🟦	ÁREA OPERATIVA
🟩	SERVICIOS ADICIONALES ÁREA PAGA	🟨	ÁREA PAGA
🟩	SERVICIO PÚBLICO	🟦	ÁREA PÚBLICA
🟦	ZONA DE REFUGIO	⬜	ÁREA TÉCNICA
🟥	ÁREA CULTURAL	🟥	ÁREA BRT
🟪	ÁREA DE TAQUILLAS BRT		

No.	PLANOS DE REFERENCIA	REV.

No.	MODELO BIM DE REFERENCIA	REV.
1	L1T1-1100-209-CON-ED-EST-MO-0001.rvt	V00
2	L1T1-1100-210-CON-ED-EST-MO-0001.rvt	V00
3	L1T1-1100-309-CON-ED-EST-MO-0001.rvt	V00
4	L1T1-1150-209-CON-ED-EST-MO-0001.rvt	V00
5	L1T1-1150-210-CON-ED-EST-MO-0001.rvt	V00
6	L1T1-1200-309-CON-ED-EST-MO-0001.rvt	V00
7	L1T1-1300-409-CON-ED-EST-MO-0001.rvt	V00
8	L1T1-1300-409-CON-ED-EST-MO-0003.rvt	V00
9	L1T1-1310-409-CON-ED-EST-MO-0001.rvt	V00
10	L1T1-2320-581-CON-ED-EST-MO-0002.rvt	V00
11	L1T1-2320-581-CON-ED-ARQ-MO-0001.rvt	V00
12	L1T1-1410-309-CON-ED-MEC-MO-0001.rvt	V00
13	L1T1-1420-309-CON-ED-MEC-MO-0001.rvt	V00
14	L1T1-5160-309-CON-ED-EST-MO-0001.rvt	V00
15	L1T1-5160-309-CON-ED-ARQ-MO-0001.rvt	V00
16	L1T1-5300-309-CON-ED-MEC-MO-0001.rvt	V00
17	L1T1-5600-309-CON-ED-INS-MO-0001.rvt	V00
18	L1T1-1330-409-CON-ED-ARQ-MO-0011.rvt	V00
19	L1T1-1330-409-CON-ED-ARQ-MO-0012.rvt	V00
20	L1T1-1330-409-CON-ED-ARQ-MO-0013.rvt	V00

No.	PAQUETE DE TRABAJO DE REFERENCIA	REV.
1	XREF-URBANISM_CONTEXT_ST09.rvt	
2	XREF-SECONDARY-STRUCTURE-ST09.rvt	
3	XREF-L1T1-1300-409-CON-ED-EST-MO-0002.rvt	

0 2 10m
1:200

VÁLIDO PARA CONSTRUCCIÓN
31-03-26

METRO BOGOTÁ
GCS Consorcio Consultores PMO Bogotá
CONSORCIO SUPERVISOR PLMB
HEC

DISEÑÓ:
REN ZHENHUA
Licencia de Arq.nivel I (China): 1101735-614

APROBÓ:
DIEGO ERNESTO DUEÑAS
Mat.: 25202-53876 CND

REVISÓ:
CARLOS MAURICIO BARRETO BARBOSA
Mat.: A4012012-14139353

DIBUJÓ:
EQUIPO CHEC

REVISIÓN No.	FECHA	DESCRIPCIÓN	REVISÓ	APROBÓ	APROBACIÓN CLIENTE
V01	31/03/2026	EMITIDO PARA CONSTRUCCIÓN	C.M.B.B	D.E.D	
V00	26/03/2025	REVISIÓN NO OBJETADA - EMITIDO PARA CONSTRUCCIÓN	F.B.R	E.O.M	
VGG	05/11/2024	EMITIDO PARA REVISIÓN Y COMENTARIOS DEL CLIENTE E INTERVENTORÍA - INCLUYE COMENTARIOS /(AJUSTES V2)	F.B.R	E.O.M	
VFF	29/07/2024	EMITIDO PARA REVISIÓN Y COMENTARIOS DEL CLIENTE E INTERVENTORÍA - INCLUYE COMENTARIOS /(AJUSTES)	F.B.R	E.O.M	
VEE	25/01/2023	EMITIDO PARA REVISIÓN Y COMENTARIOS DEL CLIENTE E INTERVENTORÍA - INCLUYE COMENTARIOS /(90% ACCESOS)	J.E.M	M.B.M	
VDD	18/12/2022	EMITIDO PARA REVISIÓN Y COMENTARIOS DEL CLIENTE E INTERVENTORÍA - INCLUYE COMENTARIOS /(NO APLICA)	J.E.M	M.B.M	
VCC	22/08/2022	EMITIDO PARA REVISIÓN Y COMENTARIOS DEL CLIENTE E INTERVENTORÍA - INCLUYE COMENTARIOS /(NO APLICA)	J.E.M	M.B.M	
VBB	06/12/2021	EMITIDO PARA REVISIÓN Y COMENTARIOS DEL CLIENTE E INTERVENTORÍA	J.E.M	M.B.M	
VA0	05/12/2021	EMITIDO PARA COMENTARIOS INTERNOS - EMISIÓN PRELIMINAR PARA COMENTARIOS	J.E.M	M.B.M	

METRO LÍNEA 1

DIRECTOR DE INTERVENTORÍA:
JAVIER DESCARGA N.
Mat.:25202-68697 CND

METRO LÍNEA 1
CONTRATO DE CONCESIÓN No. 163 DE 2019

PROYECTO PRIMERA LÍNEA DEL METRO DE BOGOTÁ - TRAMO 1

ESPECIALISTA INTERVENTORÍA:
CARLOS ALBERTO HOYOS SOTO
Mat.:A25072000-14251682

FECHA:
MARZO 2026

INFRAESTRUCTURA VIAL
ARQUITECTURA

ESTACIÓN METRO 9 (AVENIDA NQS)
NAVE CENTRAL - EDIFICIO ASCENDENTE 01 - EDIFICIO ASCENDENTE 02
VISTA EN PLANTA Y 3D - NIVEL ACCESO

PLANCHA No: L1T1-0000-309-CON-ED-ARQ-PL-0001_05_V01
ARCHIVO: L1T1-0000-309-CON-ED-ARQ-MO-0001_V00.rvt
ESCALA: INDICADA
FECHA: DICIEMBRE 2021
REVISIÓN No. V01
PLANO No. 05 DE 98