L1T1-CON-CAL-FR-0120 - B1 : 1000x707mm

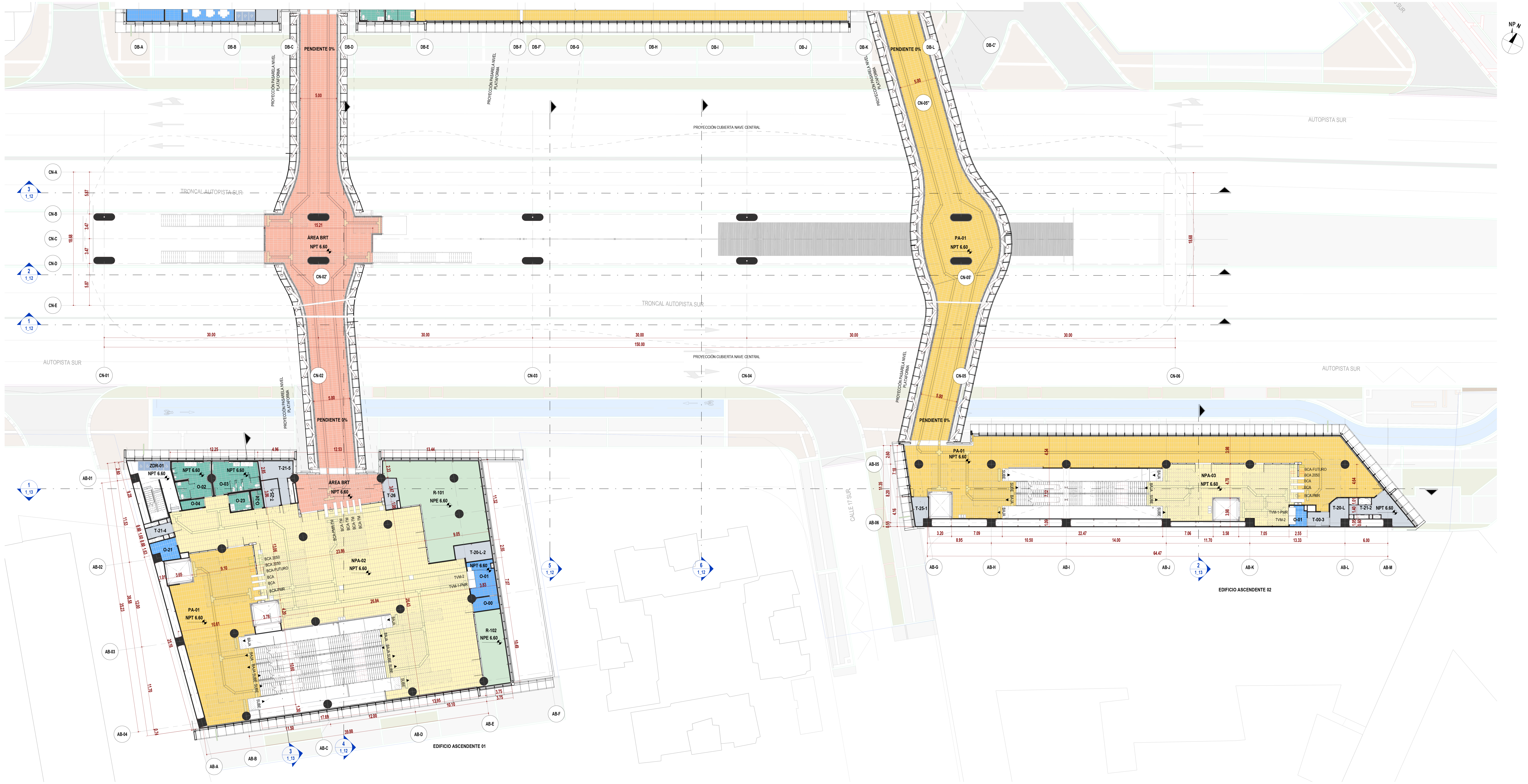

2 NIVEL INTERMEDIO_EDIFICIO ASCENDENTE 01 Y EDIFICIO ASCENDENTE 02
ESC: 1 : 200

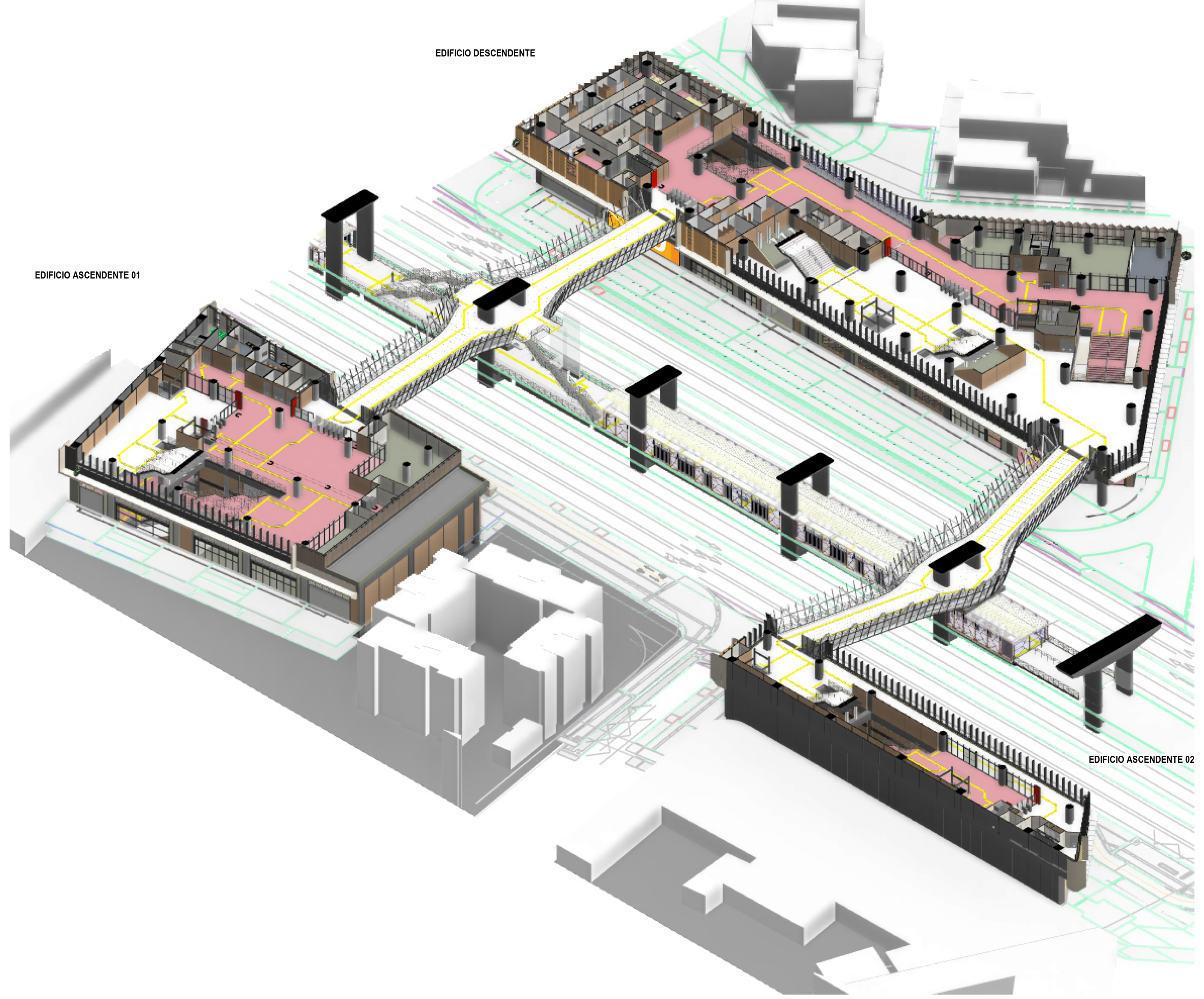

1 3D_NIVEL INTERMEDIO_GENERAL
ESC: N/A

LOCALIZACIÓN

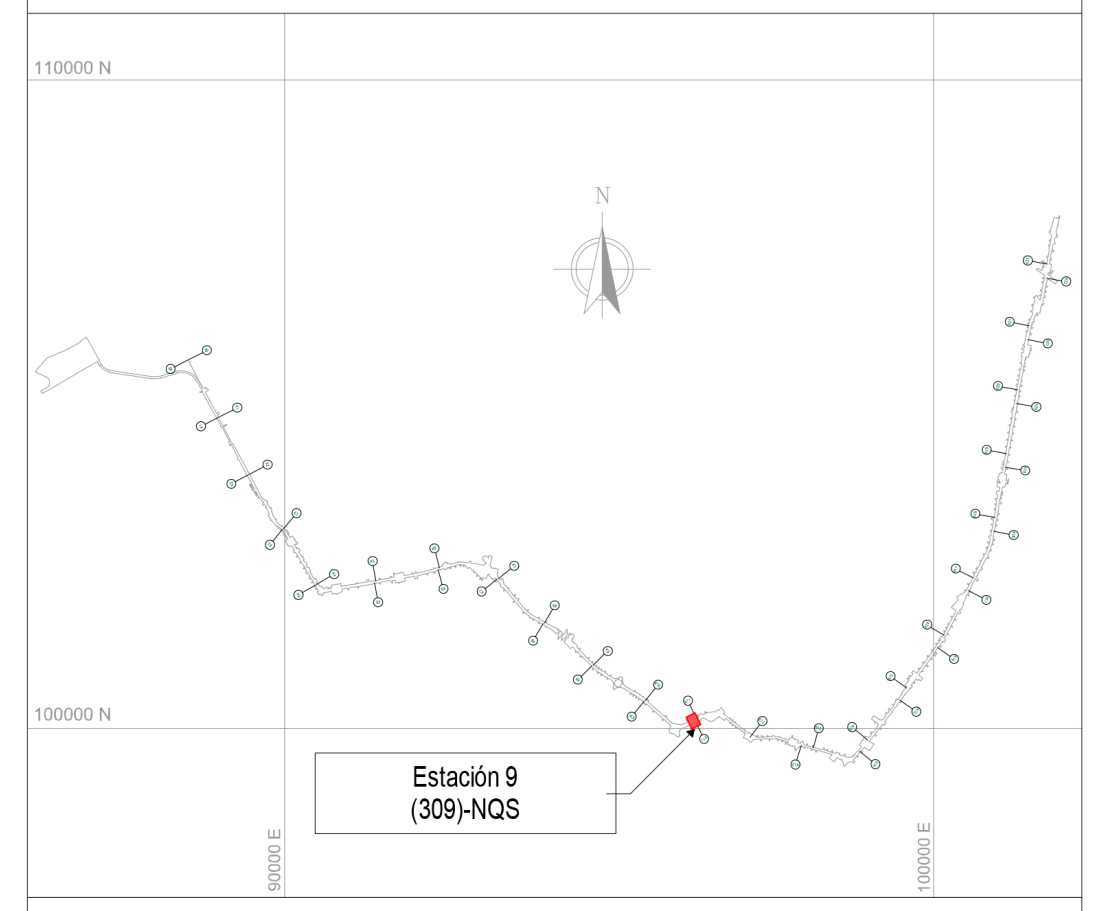

NOTAS

01 TODAS LAS DIMENSIONES ESTÁN CONFIGURADAS EN METROS A MENOS QUE SE INDIQUE UNA UNIDAD DE MEDIDA DIFERENTE.

02 TODAS LAS MEDIDAS, UBICACIÓN Y NIVELES DEBEN VERIFICARSE EN EL LUGAR DE CONSTRUCCIÓN.

03 EL NIVEL DE ACCESO AL EDIFICIO PL 01 CORRESPONDE AL +0,00 DE LA ESTACIÓN Y REFERENCIA AL NIVEL 2561.80 M.S.N.M

04 LOS NOMBRES ESPECÍFICOS DE LAS ÁREAS PUEDEN SER CONSULTADAS EN EL PLANO NO. 3 Ó EN LAS VISTAS EN PLANTA.

05 LOS COLORES QUE SE MUESTRAN EN LOS PLANOS COMO PROYECCIÓN DE ELEMENTOS ARQUITECTÓNICOS COMO CUBIERTAS FACHADAS MUROS ETC. NO REPRESENTAN LA MATERIALIDAD Y REALIDAD DE ACABADOS DEL PROYECTO, SOLO SON INDICATIVOS PARA REALIZAR UNA CORRECTA LECTURA DE LA PLANIMETRÍA.

06 LAS ESCALERAS ELÉCTRICAS INDICAN SU SENTIDO CON LA SIGUIENTE NOMENCLATURA: "SUBE" Y "BAJA".

07 SE DEBEN REVISAR LOS NIVELES ESTRUCTURALES PARA NIVEL DE ACCESO PL_01 Y SUBNIVELES, PL_02 (INTERMEDIO), PL_03 (PLATAFORMA) CON LA PLANIMETRÍA DE PLACAS ESTRUCTURALES EN LOS ENTREGABLES L1T1-1300-409-CON-ED-EST-PL-0079, 80, 81, 101, 102, 103, 125, 126, 127, 128, 129, 130, 131, 151, 152, RESPECTIVAMENTE. EL NIVEL ESTRUCTURAL (NE) REFERENCIA LOS ESPACIOS DONDE SE DEBE ACONDICIONAR EL ACABADO DE PISO SEGÚN CORRESPONDA, CON LOS NIVELES DE PISO TERMINADO (NPT). LOS NIVELES PROYECTADOS DE EMPATE (NPE) EN LAS ÁREAS DE SERVICIOS ADICIONALES, REFERENCIAN LA ADECUACIÓN DE LOS DESNIVELES EN ESTAS ÁREAS; QUEDA COMO RESPONSABILIDAD DEL LOCATARIO DEFINIR Y ACONDICIONAR ESTE ACABADO DE PISO (NPE) EN LÍNEA CON EL NIVEL (NPT) DE ESPACIOS COLINDANTES. EL NIVEL ESTRUCTURAL (NE) SE ENCUENTRA A (- 0.10M) POR DEBAJO DE LOS NIVELES DE PISO TERMINADO (NPT) Y LOS NIVELES PROYECTADOS DE EMPATE (NPE) MARCADOS EN LA PLANIMETRÍA.

- ARQ_PL_00 = SÓTANO	/NPT -8.40	- ARQ_PL_00.7 = ACCESO	/NPT -0.45
- ARQ_PL_00.1 = ACCESO	/NPT -2.40	- ARQ_PL_01 = ACCESO	/NPT 0.00
- ARQ_PL_00.2 = ACCESO	/NPT -2.25	- ARQ_PL_02 = INTERMEDIO	/NPT 6.60
- ARQ_PL_00.3 = ACCESO	/NPT -2.05	- ARQ_PL_02.2 = TOPE DE RIEL	/NPT 14.20
- ARQ_PL_00.4 = ACCESO	/NPT -1.80	- ARQ_PL_03 = PLATAFORMA	/NPT 15.34
- ARQ_PL_00.5 = ACCESO	/NPT -1.30	- ARQ_PL_04 = CUB. EDIFICACIONES	/NPT 21.94
- ARQ_PL_00.6 = ACCESO	/NPT -1.10	- ARQ_PL_05 = CUB. NAVE CENTRAL	/NPT 24.59

CONVENCIONES

▬ ▬ ▬	LÍMITE DE INTERVENCIÓN
– – –	HUELLA APÉNDICE TÉCNICO
▬	MURO DIVISORIO
— — —	PROYECCIÓN NIVEL SUPERIOR

🟩	CADE	🟨	ÁREA NO PAGA
🟩	SERVICIOS ADICIONALES ÁREA NO PAGA	🟦	ÁREA OPERATIVA
🟩	SERVICIOS ADICIONALES ÁREA PAGA	🟨	ÁREA PAGA
🟩	SERVICIO PÚBLICO	🟦	ÁREA PÚBLICA
🟦	ZONA DE REFUGIO	⬜	ÁREA TÉCNICA
🟥	ÁREA CULTURAL	🟥	ÁREA BRT
🟪	ÁREA DE TAQUILLAS BRT		

No.	PLANOS DE REFERENCIA	REV.

No.	MODELO BIM DE REFERENCIA	REV.
1	L1T1-1100-209-CON-ED-EST-MO-0001.rvt	V00
2	L1T1-1100-210-CON-ED-EST-MO-0001.rvt	V00
3	L1T1-1100-309-CON-ED-EST-MO-0001.rvt	V00
4	L1T1-1150-209-CON-ED-EST-MO-0001.rvt	V00
5	L1T1-1150-210-CON-ED-EST-MO-0001.rvt	V00
6	L1T1-1200-309-CON-ED-EST-MO-0001.rvt	V00
7	L1T1-1300-409-CON-ED-EST-MO-0001.rvt	V00
8	L1T1-1300-409-CON-ED-EST-MO-0003.rvt	V00
9	L1T1-1310-409-CON-ED-EST-MO-0001.rvt	V00
10	L1T1-2320-581-CON-ED-EST-MO-0002.rvt	V00
11	L1T1-2320-581-CON-ED-ARQ-MO-0001.rvt	V00
12	L1T1-1410-309-CON-ED-MEC-MO-0001.rvt	V00
13	L1T1-1420-309-CON-ED-MEC-MO-0001.rvt	V00
14	L1T1-5160-309-CON-ED-EST-MO-0001.rvt	V00
15	L1T1-5160-309-CON-ED-ARQ-MO-0001.rvt	V00
16	L1T1-5300-309-CON-ED-MEC-MO-0001.rvt	V00
17	L1T1-5600-309-CON-ED-INS-MO-0001.rvt	V00
18	L1T1-1330-409-CON-ED-ARQ-MO-0011.rvt	V00
19	L1T1-1330-409-CON-ED-ARQ-MO-0012.rvt	V00
20	L1T1-1330-409-CON-ED-ARQ-MO-0013.rvt	V00

No.	PAQUETE DE TRABAJO DE REFERENCIA	REV.
1	XREF-URBANISM_CONTEXT_ST09.rvt	
2	XREF-SECONDARY-STRUCTURE-ST09.rvt	
3	XREF-L1T1-1300-409-CON-ED-EST-MO-0002.rvt	

0 2 10m
1:200

TABLA DE ÁREAS ÚTILES (NIVEL INTERMEDIO_NAVE CENTRAL Y EDIFICIOS ASCENDENTES)

CÓDIGO	NOMBRE	ÁREA (m²)	DEPARTAMENTO
ARQ_PL_03_PLATAFORMA			
T-25	COMERCIO-CAJEROS AUTOMATICOS/ATM	120.54	
		120.54	
EDIFICIO ASCENDENTE 01			
ARQ_PL_02_INTERMEDIO			
NPA-02	ÁREA NO PAGA	605.62	ÁREA NO PAGA
O-00	CIRCULACIÓN ÁREAS OPERATIVAS	6.50	ÁREA OPERATIVA
O-01	VENTA AUTOMÁTICA DE BOLETOS	17.91	ÁREA OPERATIVA
O-02	BAÑOS PÚBLICOS DE HOMBRES	25.19	SERVICIO PÚBLICO
O-03	BAÑOS PÚBLICOS DE MUJERES	26.91	SERVICIO PÚBLICO
O-04	CONTROL DE ACCESO BAÑOS PÚBLICOS	4.03	SERVICIO PÚBLICO
O-21	ALMACENAMIENTO DE LA ESTACIÓN	9.21	ÁREA OPERATIVA
O-23	BAÑO PÚBLICO - FAMILIAR	7.05	SERVICIO PÚBLICO
O-24	CUARTO DE LIMPIEZA DE BAÑOS PÚBLICOS	3.71	SERVICIO PÚBLICO
PA-01	ÁREA PAGA	219.38	ÁREA PAGA
R-101	SERVICIOS ADICIONALES - ÁREA DE SERVICIO	130.73	SERVICIOS ADICIONALES - ÁREA NO PAGA
R-102	SERVICIOS ADICIONALES - ÁREA DE SERVICIO	36.83	SERVICIOS ADICIONALES - ÁREA NO PAGA
T-20-L-2	MEDIDORES (LUZ)	11.53	ÁREA TÉCNICA
T-21-4	ÁREA DE INSPECCIÓN	5.47	ÁREA TÉCNICA
T-21-5	ÁREA DE INSPECCIÓN	15.87	ÁREA TÉCNICA
T-25-1	NODO DE ACCESO DE TELECOMUNICACIONES	8.40	ÁREA TÉCNICA

TABLA DE ÁREAS ÚTILES (NIVEL INTERMEDIO_NAVE CENTRAL Y EDIFICIOS ASCENDENTES)

CÓDIGO	NOMBRE	ÁREA (m²)	DEPARTAMENTO
T-26	NODO DE ACCESO DE TELECOMUNICACIONES TMSA	7.83	ÁREA TÉCNICA
ZDR-01	ZONA DE REFUGIO (PMR)	6.06	ZONA DE REFUGIO
ÁREA BRT	ÁREA BRT	55.46	ÁREA BRT
		1203.67	
EDIFICIO ASCENDENTE 02			
ARQ_PL_02_INTERMEDIO			
NPA-03	ÁREA NO PAGA	143.46	ÁREA NO PAGA
O-01	VENTA AUTOMÁTICA DE BOLETOS	6.75	ÁREA OPERATIVA
PA-01	ÁREA PAGA	373.69	ÁREA PAGA
T-00-3	CIRCULACIÓN TÉCNICA	6.05	ÁREA TÉCNICA
T-20-L	MEDIDORES (LUZ)	8.71	ÁREA TÉCNICA
T-21-2	ÁREA DE INSPECCIÓN	18.87	ÁREA TÉCNICA
T-25-1	NODO DE ACCESO DE TELECOMUNICACIONES	7.51	ÁREA TÉCNICA
		565.05	
NAVE CENTRAL			
ARQ_PL_02_INTERMEDIO			
PA-01	ÁREA PAGA	370.65	ÁREA PAGA
ÁREA BRT	ÁREA BRT	418.57	ÁREA BRT
		789.22	
TOTAL NIVEL INTERMEDIO NAVE CENTRAL Y EDIFICIOS ASCENDENTES		2678.48	

TABLA DE ÁREAS ÚTILES POR DEPARTAMENTO (NIVEL INTERMEDIO NAVE CENTRAL Y EDIFICIOS ASCENDENTES)

DEPARTAMENTO	ÁREA (m²)
	120.54
SERVICIO PÚBLICO	66.89
SERVICIOS ADICIONALES - ÁREA NO PAGA	167.56
ZONA DE REFUGIO	6.06
ÁREA BRT	474.03
ÁREA NO PAGA	749.08
ÁREA OPERATIVA	40.37
ÁREA PAGA	963.72
ÁREA TÉCNICA	90.23
TOTAL NIVEL INTERMEDIO INTERMEDIO NAVE CENTRAL Y EDIFICIOS ASCENDENTES	2678.48

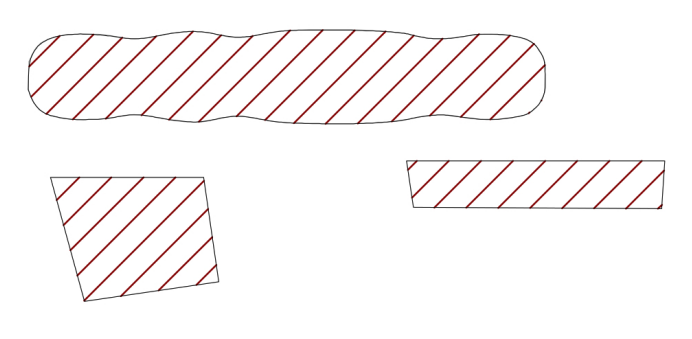

PLANO CLAVE ESTACIÓN 9

VÁLIDO PARA CONSTRUCCIÓN
31-03-26

METRO BOGOTÁ
GCS Consorcio Consultores PMO Bogotá
CONSORCIO SUPERVISOR PLMB
HEC

DISEÑO:
REN ZHENHUA
Licencia de Arq.nivel I (China): 1101735-614

APROBÓ:
DIEGO ERNESTO DUEÑAS
Mat.: 25202-53876 CND

REVISÓ:
CARLOS MAURICIO BARRETO BARBOSA
Mat.: A4012012-14139353

DIBUJÓ:
EQUIPO CHEC

REVISIÓN No.	FECHA	DESCRIPCIÓN	REVISÓ	APROBÓ	APROBACIÓN CLIENTE
V01	31/03/2026	EMITIDO PARA CONSTRUCCIÓN	C.M.B.B	D.E.D	
V00	26/03/2025	REVISIÓN NO OBJETADA - EMITIDO PARA CONSTRUCCIÓN	F.B.R	E.O.M	
VGG	05/11/2024	EMITIDO PARA REVISIÓN Y COMENTARIOS DEL CLIENTE E INTERVENTORÍA - INCLUYE COMENTARIOS /(AJUSTES V2)	F.B.R	E.O.M	
VFF	29/07/2024	EMITIDO PARA REVISIÓN Y COMENTARIOS DEL CLIENTE E INTERVENTORÍA - INCLUYE COMENTARIOS /(AJUSTES)	F.B.R	E.O.M	
VEE	25/01/2023	EMITIDO PARA REVISIÓN Y COMENTARIOS DEL CLIENTE E INTERVENTORÍA - INCLUYE COMENTARIOS /(90% ACCESOS)	J.E.M	M.B.M	
VDD	18/12/2022	EMITIDO PARA REVISIÓN Y COMENTARIOS DEL CLIENTE E INTERVENTORÍA - INCLUYE COMENTARIOS /(NO APLICA)	J.E.M	M.B.M	
VCC	22/08/2022	EMITIDO PARA REVISIÓN Y COMENTARIOS DEL CLIENTE E INTERVENTORÍA - INCLUYE COMENTARIOS /(NO APLICA)	J.E.M	M.B.M	
VBB	06/12/2021	EMITIDO PARA REVISIÓN Y COMENTARIOS DEL CLIENTE E INTERVENTORÍA	J.E.M	M.B.M	
VA0	05/12/2021	EMITIDO PARA COMENTARIOS INTERNOS - EMISIÓN PRELIMINAR PARA COMENTARIOS	J.E.M	M.B.M	

METRO LÍNEA 1

DIRECTOR DE INTERVENTORÍA:
JAVIER DESCARGA N.
Mat.:25202-68697 CND

METRO LÍNEA 1
CONTRATO DE CONCESIÓN No. 163 DE 2019

PROYECTO PRIMERA LÍNEA DEL METRO DE BOGOTÁ - TRAMO 1

ESPECIALISTA INTERVENTORÍA:
CARLOS ALBERTO HOYOS SOTO
Mat.:A25072000-14251682

FECHA:
MARZO 2026

INFRAESTRUCTURA VIAL

ARQUITECTURA

ESTACIÓN METRO 9 (AVENIDA NQS)
NAVE CENTRAL - EDIFICIO ASCENDENTE 01 - EDIFICIO ASCENDENTE 02
VISTA EN PLANTA Y 3D - NIVEL INTERMEDIO

PLANCHA No: L1T1-0000-309-CON-ED-ARQ-PL-0001_07_V01
ARCHIVO: L1T1-0000-309-CON-ED-ARQ-MO-0001_V00.rvt
ESCALA: INDICADA
FECHA: DICIEMBRE 2021
REVISIÓN No. V01
PLANO No. 07 DE 98