L1T1-CON-CAL-FR-0120 - B1 : 1000x707mm

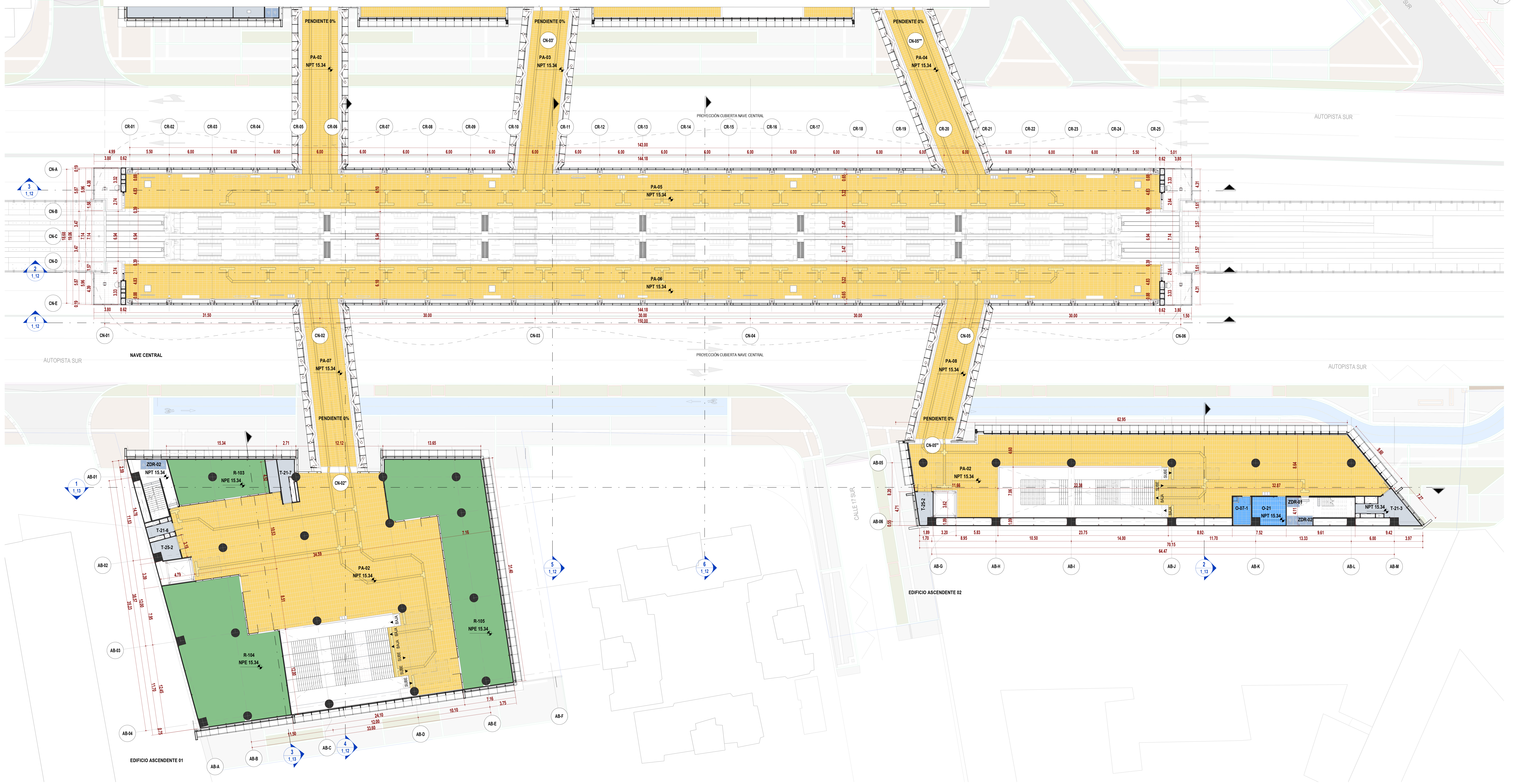
NP N
PENDIENTE 0%
PA-02
NPT 15.34
CN-03'
PA-03
NPT 15.34
CN-05''''
PA-04
NPT 15.34
PROYECCIÓN CUBIERTA NAVE CENTRAL
AUTOPISTA SUR
CR-01
CR-02
CR-03
CR-04
CR-05
CR-06
CR-07
CR-08
CR-09
CR-10
CR-11
CR-12
CR-13
CR-14
CR-15
CR-16
CR-17
CR-18
CR-19
CR-20
CR-21
CR-22
CR-23
CR-24
CR-25
CN-A
CN-B
CN-C
CN-D
CN-E
143.00
144.18
150.00
PA-05
NPT 15.34
PA-06
NPT 15.34
CN-01
CN-02
CN-03
CN-04
CN-05
CN-06
NAVE CENTRAL
PA-07
NPT 15.34
PA-08
NPT 15.34
CN-02''
CN-05'''
ZDR-02
NPT 15.34
R-103
NPE 15.34
T-21-7
T-21-6
T-25-2
PA-02
NPT 15.34
R-104
NPE 15.34
R-105
NPE 15.34
SUBE
BAJA
AB-01
AB-02
AB-03
AB-04
AB-A
AB-B
AB-C
AB-D
AB-E
AB-F
EDIFICIO ASCENDENTE 01
CALLE 17 SUR
AB-05
AB-06
PA-02
NPT 15.34
T-25-2
O-07-1
O-21
NPT 15.34
ZDR-01
ZDR-02
NPT 15.34
T-21-3
62.95
70.15
64.47
AB-G
AB-H
AB-I
AB-J
AB-K
AB-L
AB-M
EDIFICIO ASCENDENTE 02

2 NIVEL PLATAFORMA_EDIFICIO ASCENDENTE

ESC: 1 : 200

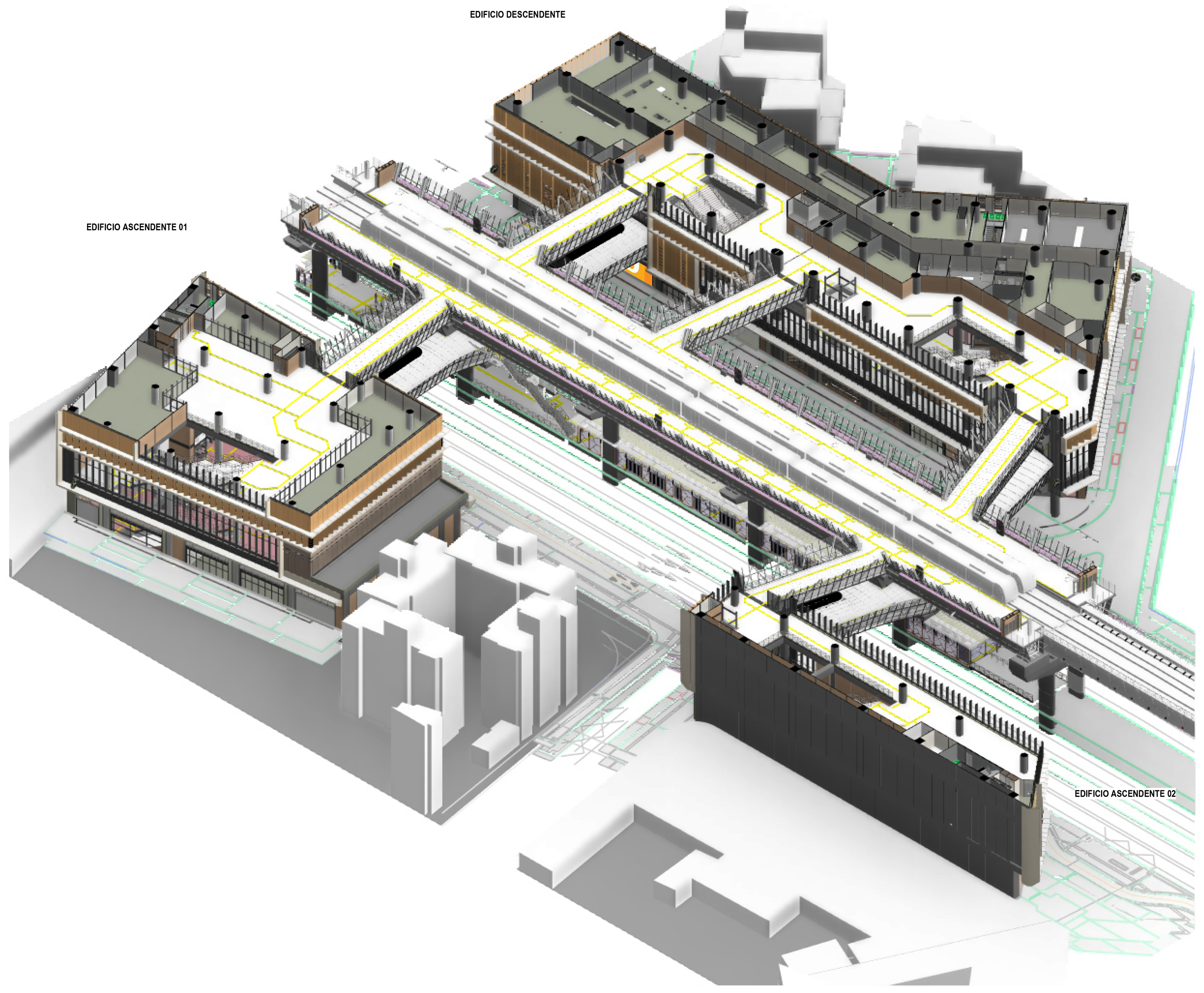
EDIFICIO DESCENDENTE
EDIFICIO ASCENDENTE 01
EDIFICIO ASCENDENTE 02

1 3D_NIVEL PLATAFORMA_GENERAL

ESC: N/A

LOCALIZACIÓN

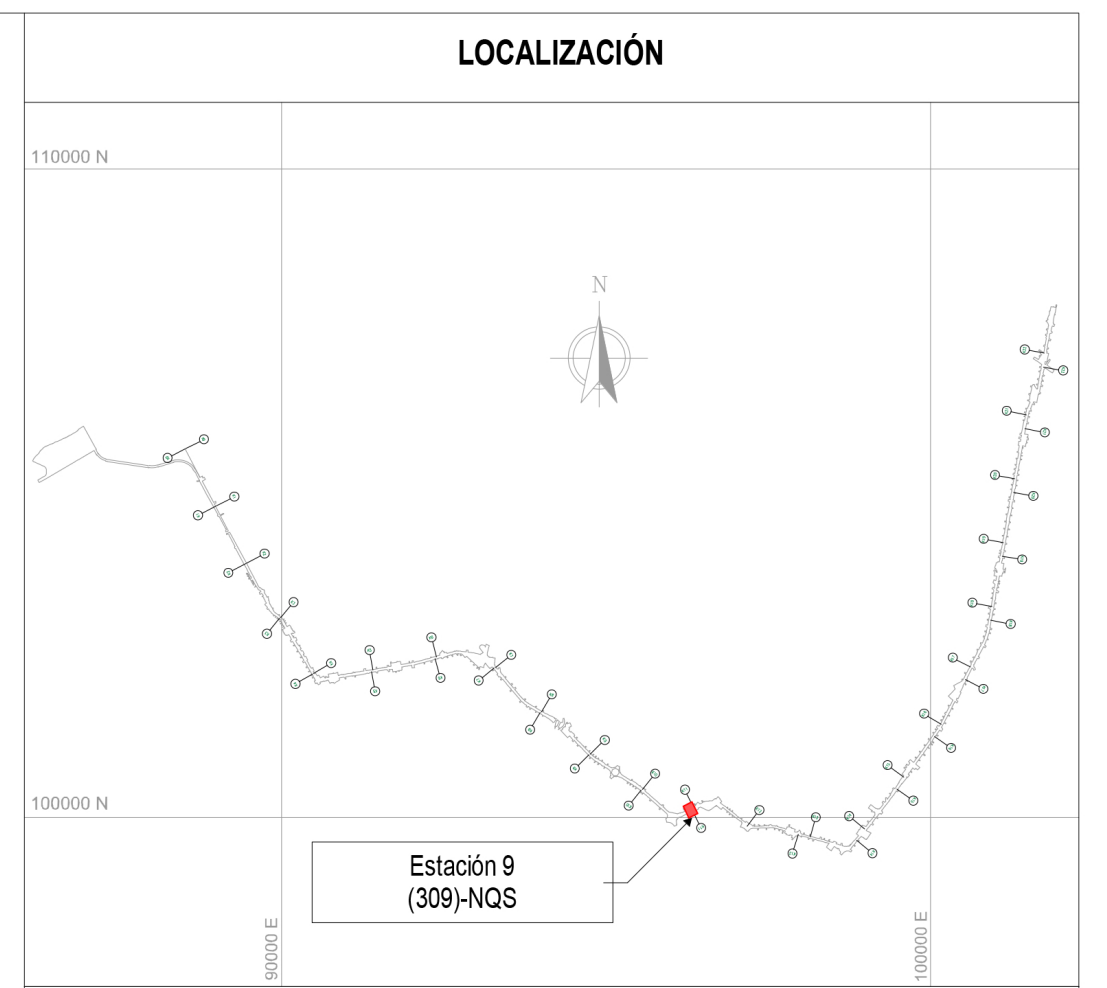
110000 N
100000 N
90000 E
100000 E
N
Estación 9
(309)-NQS

NOTAS

01 TODAS LAS DIMENSIONES ESTÁN CONFIGURADAS EN METROS A MENOS QUE SE INDIQUE UNA UNIDAD DE MEDIDA DIFERENTE.

02 TODAS LAS MEDIDAS, UBICACIÓN Y NIVELES DEBEN VERIFICARSE EN EL LUGAR DE CONSTRUCCIÓN.

03 EL NIVEL DE ACCESO AL EDIFICIO PL 01 CORRESPONDE AL +0,00 DE LA ESTACIÓN Y REFERENCIA AL NIVEL 2561.80 M.S.N.M

04 LOS NOMBRES ESPECÍFICOS DE LAS ÁREAS PUEDEN SER CONSULTADAS EN EL PLANO NO. 3 Ó EN LAS VISTAS EN PLANTA.

05 LOS COLORES QUE SE MUESTRAN EN LOS PLANOS COMO PROYECCIÓN DE ELEMENTOS ARQUITECTÓNICOS COMO CUBIERTAS FACHADAS MUROS ETC. NO REPRESENTAN LA MATERIALIDAD Y REALIDAD DE ACABADOS DEL PROYECTO, SOLO SON INDICATIVOS PARA REALIZAR UNA CORRECTA LECTURA DE LA PLANIMETRÍA.

06 LAS ESCALERAS ELÉCTRICAS INDICAN SU SENTIDO CON LA SIGUIENTE NOMENCLATURA: "SUBE" Y "BAJA".

07 SE DEBEN REVISAR LOS NIVELES ESTRUCTURALES PARA NIVEL DE ACCESO PL_01 Y SUBNIVELES, PL_02 (INTERMEDIO), PL_03 (PLATAFORMA) CON LA PLANIMETRÍA DE PLACAS ESTRUCTURALES EN LOS ENTREGABLES L1T1-1300-409-CON-ED-EST-PL-0079, 80, 81, 101, 102, 103, 125, 126, 127, 128, 129, 130, 131, 151, 152, RESPECTIVAMENTE. EL NIVEL ESTRUCTURAL (NE) REFERENCIA LOS ESPACIOS DONDE SE DEBE ACONDICIONAR EL ACABADO DE PISO SEGÚN CORRESPONDA, CON LOS NIVELES DE PISO TERMINADO (NPT). LOS NIVELES PROYECTADOS DE EMPATE (NPE) EN LAS ÁREAS DE SERVICIOS ADICIONALES, REFERENCIAN LA ADECUACIÓN DE LOS DESNIVELES EN ESTAS ÁREAS; QUEDA COMO RESPONSABILIDAD DEL LOCATARIO DEFINIR Y ACONDICIONAR ESTE ACABADO DE PISO (NPE) EN LÍNEA CON EL NIVEL (NPT) DE ESPACIOS COLINDANTES. EL NIVEL ESTRUCTURAL (NE) SE ENCUENTRA A (- 0.10M) POR DEBAJO DE LOS NIVELES DE PISO TERMINADO (NPT) Y LOS NIVELES PROYECTADOS DE EMPATE (NPE) MARCADOS EN LA PLANIMETRÍA.

- ARQ_PL_00 = SÓTANO /NPT -8.40
- ARQ_PL_00.1 = ACCESO /NPT -2.40
- ARQ_PL_00.2 = ACCESO /NPT -2.25
- ARQ_PL_00.3 = ACCESO /NPT -2.05
- ARQ_PL_00.4 = ACCESO /NPT -1.80
- ARQ_PL_00.5 = ACCESO /NPT -1.30
- ARQ_PL_00.6 = ACCESO /NPT -1.10
- ARQ_PL_00.7 = ACCESO /NPT -0.45
- ARQ_PL_01 = ACCESO /NPT 0.00
- ARQ_PL_02 = INTERMEDIO /NPT 6.60
- ARQ_PL_02.2 = TOPE DE RIEL /NPT 14.20
- ARQ_PL_03 = PLATAFORMA /NPT 15.34
- ARQ_PL_04 = CUB. EDIFICACIONES /NPT 21.94
- ARQ_PL_05 = CUB. NAVE CENTRAL /NPT 24.59

CONVENCIONES

▬ ▬	LÍMITE DE INTERVENCIÓN
– –	HUELLA APÉNDICE TÉCNICO
▬	MURO DIVISORIO
— —	PROYECCIÓN NIVEL SUPERIOR
■	CADE
■	SERVICIOS ADICIONALES ÁREA NO PAGA
■	SERVICIOS ADICIONALES ÁREA PAGA
■	SERVICIO PÚBLICO
■	ZONA DE REFUGIO
■	ÁREA CULTURAL
■	ÁREA DE TAQUILLAS BRT
■	ÁREA NO PAGA
■	ÁREA OPERATIVA
■	ÁREA PAGA
■	ÁREA PÚBLICA
■	ÁREA TÉCNICA
■	ÁREA BRT

TABLA DE ÁREAS ÚTILES (NIVEL PLATAFORMA_NAVE CENTRAL Y EDIFICIOS ASCENDENTES)

CÓDIGO	NOMBRE	ÁREA (m²)	DEPARTAMENTO
EDIFICIO ASCENDENTE 01			
ARQ_PL_03_PLATAFORMA			
PA-02	ÁREA PAGA	679.56	ÁREA PAGA
R-103	SERVICIOS ADICIONALES - ÁREA DE SERVICIO	70.61	SERVICIOS ADICIONALES - ÁREA PAGA
R-104	SERVICIOS ADICIONALES - ÁREA DE SERVICIO	240.21	SERVICIOS ADICIONALES - ÁREA PAGA
R-105	SERVICIOS ADICIONALES - ÁREA DE SERVICIO	270.45	SERVICIOS ADICIONALES - ÁREA PAGA
T-20-L-3	MEDIDORES (LUZ)	6.77	ÁREA TÉCNICA
T-21-6	ÁREA DE INSPECCIÓN	5.47	ÁREA TÉCNICA
T-21-7	ÁREA DE INSPECCIÓN	9.63	ÁREA TÉCNICA
T-25-2	NODO DE ACCESO DE TELECOMUNICACIONES	9.41	ÁREA TÉCNICA
ZDR-02	ZONA DE REFUGIO (PMR)	4.86	ZONA DE REFUGIO
		1296.98	
EDIFICIO ASCENDENTE 02			
ARQ_PL_03_PLATAFORMA			
O-07-1	CUARTO DE LIMPIEZA COMPLEMENTARIO	9.96	ÁREA OPERATIVA
O-21	ALMACENAMIENTO DE LA ESTACIÓN	17.53	ÁREA OPERATIVA
PA-02	ÁREA PAGA	472.75	ÁREA PAGA
T-21-3	ÁREA DE INSPECCIÓN	19.17	ÁREA TÉCNICA
T-25-2	NODO DE ACCESO DE TELECOMUNICACIONES	8.83	ÁREA TÉCNICA
ZDR-01	ZONA DE REFUGIO (PMR)	2.43	ZONA DE REFUGIO
ZDR-02	ZONA DE REFUGIO (PMR)	5.42	ZONA DE REFUGIO
		536.08	
NAVE CENTRAL			
ARQ_PL_03_PLATAFORMA			
PA-02	ÁREA PAGA	117.33	ÁREA PAGA
PA-03	ÁREA PAGA	117.98	ÁREA PAGA
PA-04	ÁREA PAGA	125.98	ÁREA PAGA
PA-05	ÁREA PAGA	697.51	ÁREA PAGA
PA-06	ÁREA PAGA	697.51	ÁREA PAGA
PA-07	ÁREA PAGA	121.27	ÁREA PAGA
PA-08	ÁREA PAGA	101.07	ÁREA PAGA
		1978.65	
TOTAL NIVEL PLATAFORMA_NAVE_CENTRAL_Y_EDIFICIOS_ASCENDENTES		3811.72	

TABLA DE ÁREAS ÚTILES POR DEPARTAMENTO (NIVEL PLATAFORMA NAVE CENTRAL Y EDIFICIOS ASCENDENTES)

DEPARTAMENTO	ÁREA (m²)
SERVICIOS ADICIONALES - ÁREA PAGA	581.28
ÁREA OPERATIVA	27.49
ÁREA PAGA	3130.96
ZONA DE REFUGIO	12.71
ÁREA TÉCNICA	59.28
TOTAL NIVEL PLATAFORMA_NAVE_CENTRAL_Y_EDIFICIOS_ASCENDENTES	3811.72

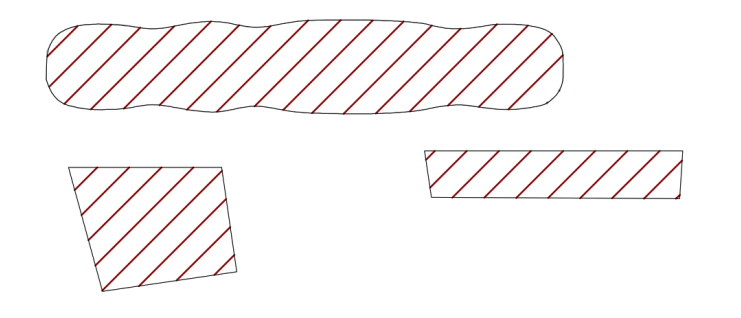

PLANO CLAVE ESTACIÓN 9

No.	PLANOS DE REFERENCIA	REV.

No.	MODELO BIM DE REFERENCIA	REV.
1	L1T1-1100-209-CON-ED-EST-MO-0001.rvt	V00
2	L1T1-1100-210-CON-ED-EST-MO-0001.rvt	V00
3	L1T1-1100-309-CON-ED-EST-MO-0001.rvt	V00
4	L1T1-1150-209-CON-ED-EST-MO-0001.rvt	V00
5	L1T1-1150-210-CON-ED-EST-MO-0001.rvt	V00
6	L1T1-1200-309-CON-ED-EST-MO-0001.rvt	V00
7	L1T1-1300-409-CON-ED-EST-MO-0001.rvt	V00
8	L1T1-1300-409-CON-ED-EST-MO-0003.rvt	V00
9	L1T1-1310-409-CON-ED-EST-MO-0001.rvt	V00
10	L1T1-2320-581-CON-ED-EST-MO-0002.rvt	V00
11	L1T1-2320-581-CON-ED-ARQ-MO-0001.rvt	V00
12	L1T1-1410-309-CON-ED-MEC-MO-0001.rvt	V00
13	L1T1-1420-309-CON-ED-MEC-MO-0001.rvt	V00
14	L1T1-5160-309-CON-ED-EST-MO-0001.rvt	V00
15	L1T1-5160-309-CON-ED-ARQ-MO-0001.rvt	V00
16	L1T1-5300-309-CON-ED-MEC-MO-0001.rvt	V00
17	L1T1-5600-309-CON-ED-INS-MO-0001.rvt	V00
18	L1T1-1330-409-CON-ED-ARQ-MO-0011.rvt	V00
19	L1T1-1330-409-CON-ED-ARQ-MO-0012.rvt	V00
20	L1T1-1330-409-CON-ED-ARQ-MO-0013.rvt	V00

No.	PAQUETE DE TRABAJO DE REFERENCIA	REV.
1	XREF-URBANISM_CONTEXT_ST09.rvt	
2	XREF-SECONDARY-STRUCTURE-ST09.rvt	
3	XREF-L1T1-1300-409-CON-ED-EST-MO-0002.rvt	

0 2 10m
1:200

VÁLIDO PARA CONSTRUCCIÓN
31-03-26

METRO BOGOTÁ
GCS Consorcio Consultores PMO Bogotá
CONSORCIO SUPERVISOR PLMB
CHEC

DISEÑÓ:
REN ZHENHUA
Licencia de Arq.nivel I (China): 1101735-614

REVISÓ:
CARLOS MAURICIO BARRETO BARBOSA
Mat.: A4012012-14139353

APROBÓ:
DIEGO ERNESTO DUEÑAS
Mat.: 25202-53876 CND

DIBUJÓ:
EQUIPO CHEC

REVISIÓN No.	FECHA	DESCRIPCIÓN	REVISÓ	APROBÓ	APROBACIÓN CLIENTE
V01	31/03/2026	EMITIDO PARA CONSTRUCCIÓN	C.M.B.B	D.E.D	
V00	26/03/2025	REVISIÓN NO OBJETADA - EMITIDO PARA CONSTRUCCIÓN	F.B.R	E.O.M	
VGG	05/11/2024	EMITIDO PARA REVISIÓN Y COMENTARIOS DEL CLIENTE E INTERVENTORÍA - INCLUYE COMENTARIOS /(AJUSTES V2)	F.B.R	E.O.M	
VFF	29/07/2024	EMITIDO PARA REVISIÓN Y COMENTARIOS DEL CLIENTE E INTERVENTORÍA - INCLUYE COMENTARIOS /(AJUSTES)	F.B.R	E.O.M	
VEE	25/01/2023	EMITIDO PARA REVISIÓN Y COMENTARIOS DEL CLIENTE E INTERVENTORÍA - INCLUYE COMENTARIOS /(90% ACCESOS)	J.E.M	M.B.M	
VDD	18/12/2022	EMITIDO PARA REVISIÓN Y COMENTARIOS DEL CLIENTE E INTERVENTORÍA - INCLUYE COMENTARIOS /(NAVE CENTRAL)	J.E.M	M.B.M	
VCC	22/08/2022	EMITIDO PARA REVISIÓN Y COMENTARIOS DEL CLIENTE E INTERVENTORÍA - INCLUYE COMENTARIOS /(ENTREGA 90%)	J.E.M	M.B.M	
VBB	06/12/2021	EMITIDO PARA REVISIÓN Y COMENTARIOS DEL CLIENTE E INTERVENTORÍA	J.E.M	M.B.M	
VA0	05/12/2021	EMITIDO PARA COMENTARIOS INTERNOS - EMISIÓN PRELIMINAR PARA COMENTARIOS	J.E.M	M.B.M	

METRO LÍNEA 1

METRO LÍNEA 1
CONTRATO DE CONCESIÓN No. 163 DE 2019

PROYECTO PRIMERA LÍNEA DEL METRO DE BOGOTÁ - TRAMO 1

INFRAESTRUCTURA VIAL
ARQUITECTURA

ESTACIÓN METRO 9 (AVENIDA NQS)
EDIFICIO ASCENDENTE 01 - EDIFICIO ASCENDENTE 02
VISTA EN PLANTA Y 3D - NIVEL PLATAFORMA

DIRECTOR DE INTERVENTORÍA:
JAVIER DESCARGA N.
Mat.:25202-68697 CND

ESPECIALISTA INTERVENTORÍA:
CARLOS ALBERTO HOYOS SOTO
Mat.:A25072000-14251682

FECHA: MARZO 2026

PLANCHA No: L1T1-0000-309-CON-ED-ARQ-PL-0001_09_V01
ARCHIVO: L1T1-0000-309-CON-ED-ARQ-MO-0001_V00.rvt

ESCALA: INDICADA
FECHA: DICIEMBRE 2021

REVISIÓN No. V01

PLANO No. 09 DE 98