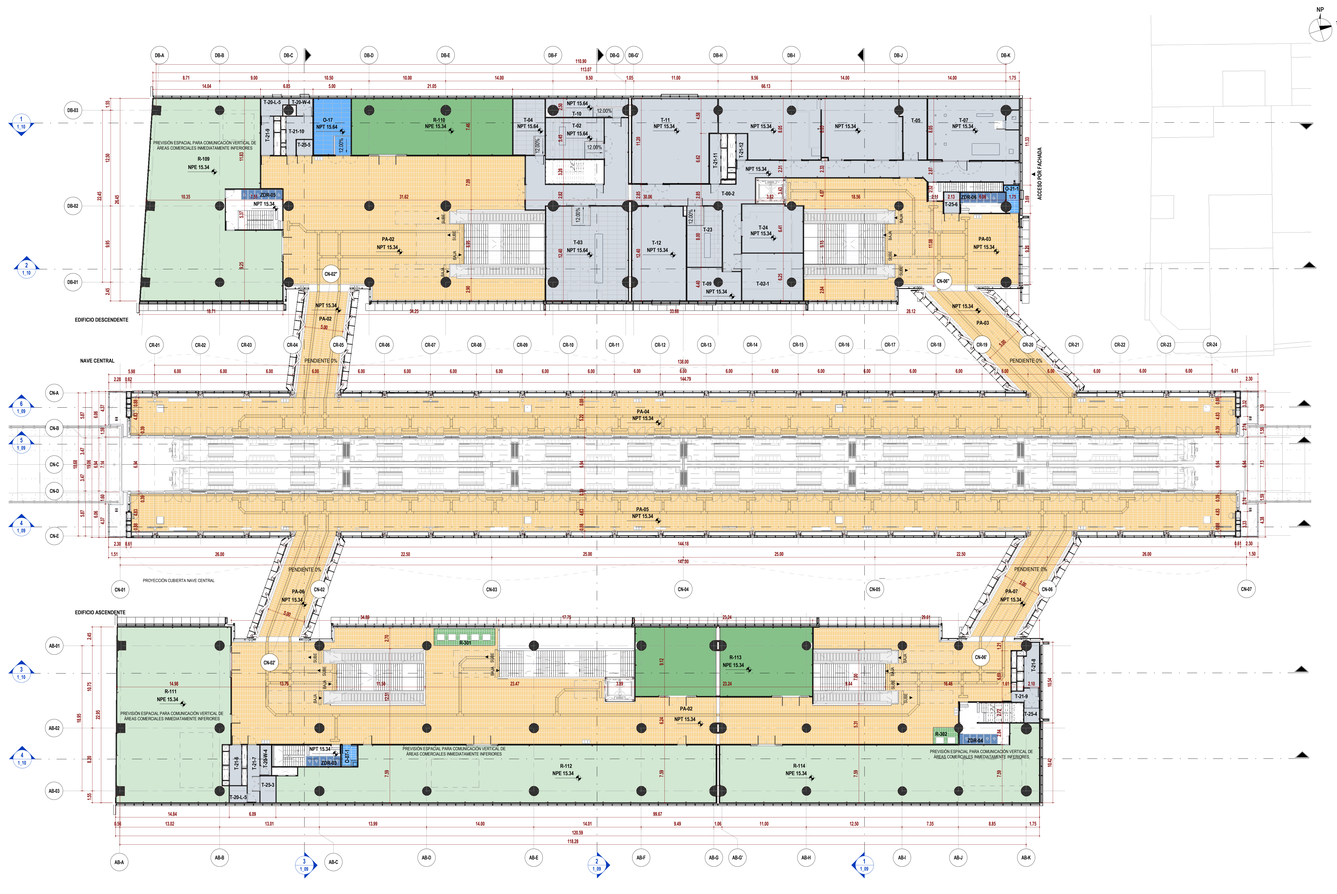
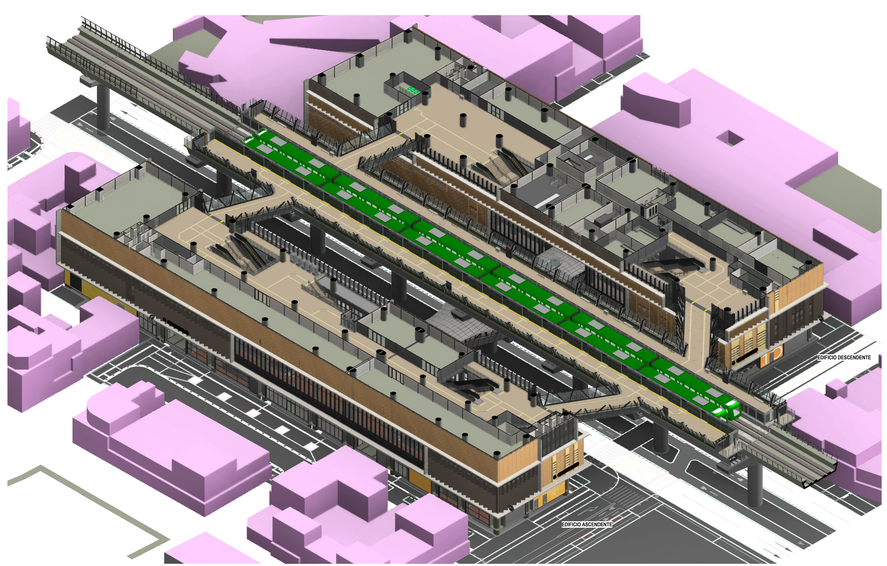


2 NIVEL PLATAFORMA_GENERAL
ESC: 1 : 200



1 3D_NIVEL PLATAFORMA_GENERAL
ESC: N/A

TABLA DE ÁREAS ÚTILES (NIVEL PLATAFORMA)

CÓDIGO	NOMBRE	ÁREA (m²)	DEPARTAMENTO
EDIFICIO ASCENDENTE			
ARQ_PL_03_PLATAFORMA			
O-07-1	CUARTO DE LIMPIEZA COMPLEMENTARIO	5.60	ÁREA OPERATIVA
PA-02	ÁREA PAGA	920.65	ÁREA PAGA
R-111	SERVICIOS ADICIONALES - ÁREA DE SERVICIO	324.60	SERVICIOS ADICIONALES - ÁREA NO PAGA
R-112	SERVICIOS ADICIONALES - ÁREA DE SERVICIO	387.87	SERVICIOS ADICIONALES - ÁREA NO PAGA
R-113	SERVICIOS ADICIONALES - ÁREA DE SERVICIO	201.43	SERVICIOS ADICIONALES - ÁREA PAGA
R-114	SERVICIOS ADICIONALES - ÁREA DE SERVICIO	316.53	SERVICIOS ADICIONALES - ÁREA NO PAGA
R-301	SERVICIOS ADICIONALES - MÁQUINAS EXPENDEDORAS/CAJEROS AUTOMÁTICOS	17.60	SERVICIOS ADICIONALES - ÁREA PAGA
R-302	SERVICIOS ADICIONALES - MÁQUINAS EXPENDEDORAS/CAJEROS AUTOMÁTICOS	5.96	SERVICIOS ADICIONALES - ÁREA PAGA
T-20-L-5	MEDIDORES (LUZ)	4.75	ÁREA TÉCNICA
T-20-W-4	MEDIDORES (AGUA)	5.85	ÁREA TÉCNICA
T-21-8	ÁREA DE INSPECCIÓN	7.96	ÁREA TÉCNICA
T-21-7	ÁREA DE INSPECCIÓN	11.50	ÁREA TÉCNICA
T-21-6	ÁREA DE INSPECCIÓN	10.44	ÁREA TÉCNICA
T-21-9	ÁREA DE INSPECCIÓN	7.19	ÁREA TÉCNICA
T-25-3	NODO DE ACCESO DE TELECOMUNICACIONES	6.84	ÁREA TÉCNICA
T-25-4	NODO DE ACCESO DE TELECOMUNICACIONES	3.56	ÁREA TÉCNICA
ZDR-03	ZONA DE REFUGIO (PMR)	6.08	ZONA DE REFUGIO
ZDR-04	ZONA DE REFUGIO (PMR)	6.78	ZONA DE REFUGIO
		2251.99	
EDIFICIO DESCENDENTE			
ARQ_PL_03_PLATAFORMA			
O-17	OPERADORES TELECOMUNICACIONES EXTERIORES	35.21	ÁREA OPERATIVA
O-31-1	ALMACENAMIENTO DE LA ESTACIÓN	5.35	ÁREA OPERATIVA
PA-02	ÁREA PAGA	503.28	ÁREA PAGA
PA-03	ÁREA PAGA	269.93	ÁREA PAGA
R-109	SERVICIOS ADICIONALES - ÁREA DE SERVICIO	383.67	SERVICIOS ADICIONALES - ÁREA NO PAGA
R-110	SERVICIOS ADICIONALES - ÁREA DE SERVICIO	190.28	SERVICIOS ADICIONALES - ÁREA PAGA
T-00-2	CIRCULACIÓN TÉCNICA	226.50	ÁREA TÉCNICA
T-03	LOCAL DE CONDUCCIÓN AUTOMÁTICA (CBTC)	40.42	ÁREA TÉCNICA
T-07-1	UPS DEDICADA (CBTC)	47.56	ÁREA TÉCNICA


TABLA DE ÁREAS ÚTILES (NIVEL PLATAFORMA)

CÓDIGO	NOMBRE	ÁREA (m²)	DEPARTAMENTO
T-03	TELECOMUNICACIONES ESTACIÓN - CORRIENTE DÉBIL	128.07	ÁREA TÉCNICA
T-04	EQUIPO BOLETERÍA	29.66	ÁREA TÉCNICA
T-05	ALMACÉN PARA MANTENIMIENTO	24.93	ÁREA TÉCNICA
T-06	SALA DE TABLEROS	81.19	ÁREA TÉCNICA
T-07	CENTRO DE TRANSFORMACIÓN (CT)	93.32	ÁREA TÉCNICA
T-09	ALMACÉN EQUIPO ELÉCTRICO	27.84	ÁREA TÉCNICA
T-10	CUARTO DE EQUIPO ELECTROMECÁNICO	22.49	ÁREA TÉCNICA
T-11	CUARTO DE VENTILACIÓN	114.44	ÁREA TÉCNICA
T-12	PLANTA DE REFRIGERACIÓN PARA LA CLIMATIZACIÓN	94.17	ÁREA TÉCNICA
T-20-L-5	MEDIDORES (LUZ)	6.70	ÁREA TÉCNICA
T-20-W-4	MEDIDORES (AGUA)	5.31	ÁREA TÉCNICA
T-21-9	ÁREA DE INSPECCIÓN	8.07	ÁREA TÉCNICA
T-21-10	ÁREA DE INSPECCIÓN	12.62	ÁREA TÉCNICA
T-21-11	ÁREA DE INSPECCIÓN	9.05	ÁREA TÉCNICA
T-21-12	ÁREA DE INSPECCIÓN	4.72	ÁREA TÉCNICA
T-22	CUARTO DE UPS	90.47	ÁREA TÉCNICA
T-23	CUARTO PGAP	35.68	ÁREA TÉCNICA
T-24	TETRA UPS	49.75	ÁREA TÉCNICA
T-25-5	NODO DE ACCESO DE TELECOMUNICACIONES	4.14	ÁREA TÉCNICA
T-25-6	NODO DE ACCESO DE TELECOMUNICACIONES	5.30	ÁREA TÉCNICA
ZDR-05	ZONA DE REFUGIO (PMR)	7.29	ZONA DE REFUGIO
ZDR-06	ZONA DE REFUGIO (PMR)	7.94	ZONA DE REFUGIO
		2510.34	
NAVE CENTRAL			
ARQ_PL_03_PLATAFORMA			
PA-02	ÁREA PAGA	71.06	ÁREA PAGA
PA-03	ÁREA PAGA	96.90	ÁREA PAGA
PA-04	ÁREA PAGA	697.49	ÁREA PAGA
PA-05	ÁREA PAGA	697.45	ÁREA PAGA
PA-06	ÁREA PAGA	76.15	ÁREA PAGA
PA-07	ÁREA PAGA	82.27	ÁREA PAGA
		1721.32	
TOTAL NIVEL PLATAFORMA		6483.65	

TABLA DE ÁREAS ÚTILES POR DEPARTAMENTO (NIVEL PLATAFORMA)

DEPARTAMENTO	ÁREA (m²)
SERVICIOS ADICIONALES - ÁREA NO PAGA	1412.66
SERVICIOS ADICIONALES - ÁREA PAGA	576.27
ZONA DE REFUGIO	28.09
ÁREA OPERATIVA	46.16
ÁREA PAGA	3411.16
ÁREA TÉCNICA	1209.29
TOTAL NIVEL PLATAFORMA	6483.65

LOCALIZACIÓN



NOTAS

01 TODAS LAS DIMENSIONES ESTÁN CONFIGURADAS EN METROS A MENOS QUE SE INDIQUE UNA UNIDAD DE MEDIDA DIFERENTE.

02 TODAS LAS MEDIDAS, UBICACIÓN Y NIVELES DEBEN VERIFICARSE EN EL LUGAR DE CONSTRUCCIÓN.

03 NIVEL DE ACCESO AL EDIFICIO PL 01 CORRESPONDE AL -0.00m DE LA ESTACIÓN Y REFERENCIA AL NIVEL 2567.10 M.S.N.M

04 LOS NOMBRES ESPECÍFICOS DE LAS ÁREAS PUEDEN SER CONSULTADAS EN EL PLANO NO. 3 EN LAS VISTAS EN PLANTA.

05 LOS COLORES QUE SE MUESTRAN EN LOS PLANOS COMO PROYECCIÓN DE ELEMENTOS ARQUITECTÓNICOS COMO CUBIERTAS Y ACHAQUE MUROS ETC. NO REPRESENTAN LA MATERIALIDAD Y REALIDAD DE ACABADOS DEL PROYECTO, SOLO SON INDICATIVOS PARA REALIZAR UNA CORRECTA LECTURA DE LA PLANIMETRÍA.

06 LAS ESCALERAS ELÉCTRICAS INDICAN SU SENTIDO CON LA SIGUIENTE NOMENCLATURA: "SUBE" Y "BAJA".

07 SE DEBEN REVISAR LOS NIVELES ESTRUCTURALES PARA NIVEL DE ACCESO PL_01 Y SUBNIVELES PL_02 (INTERMEDIO), PL_03 (PLATAFORMA) CON LA PLANIMETRÍA DE PLACAS ESTRUCTURALES EN LOS ENTREGABLES LT1T-1000-410-CON-ED-EST-PL-0069, 70, 71, 72, 107, 108, 109, 110, 111, 112, 113, 114, 115, RESPECTIVAMENTE. EL NIVEL ESTRUCTURAL (NE) REFERENCIA LOS ESPESORES DONDE SE DEBE ACONDICIONAR EL ACABADO DE PISO DEBIDO A LOS ESPESORES DE PISO TERMINADO (NPT). LOS NIVELES PROYECTADOS DE EMPATE (NPE) EN LAS ÁREAS DE SERVICIOS ADICIONALES, REFERENCIAN LA ADECUACIÓN DE LOS DESNIVELES EN ESTAS ÁREAS QUEDA COMO RESPONSABILIDAD DEL LOCATARIO DEBIDO A LA ADECUACIÓN ARTE ARQUITECTÓNICO. LOS NIVELES PROYECTADOS DE EMPATE (NPE) REFERENCIAN LOS NIVELES ESTRUCTURAL (NE) DE ENCUENTRO A 0.10M POR DEBAJO DE LOS NIVELES DE PISO TERMINADO (NPT). Y LOS NIVELES PROYECTADOS DE EMPATE (NPE) MARCADOS EN LA PLANIMETRÍA.

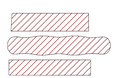
ARQ_PL_00 = SOTANO	NPT -0.60	ARQ_PL_02 = INTERMEDIO	NPT 6.60
ARQ_PL_00.1 = ACCESO	NPT -0.50	ARQ_PL_02.1 = TOPE DE RIEL	NPT 14.20
ARQ_PL_00.2 = ACCESO	NPT -0.50	ARQ_PL_02.2 = ACCESO	NPT 14.20
ARQ_PL_00.3 = ACCESO	NPT -0.20	ARQ_PL_03 = PLATAFORMA ESCALERAS	NPT 0.34
ARQ_PL_00.4 = ACCESO	NPT -0.10	ARQ_PL_04 = CUBIERTA NAVE CENTRAL	NPT 24.99
ARQ_PL_01 = ACCESO	NPT 0.00		

CONVENCIONES

- LÍMITE DE INTERVENCIÓN
- HUELLA APÉNDICE TÉCNICO
- MURO DIVISORIO
- PROYECCIÓN NIVEL SUPERIOR

SERVICIOS ADICIONALES - ÁREA NO PAGA	ÁREA NO PAGA
SERVICIOS ADICIONALES - ÁREA PAGA	ÁREA OPERATIVA
SERVICIO PÚBLICO	ÁREA PAGA
ZONA DE REFUGIO	ÁREA PÚBLICA
ÁREA CULTURAL	ÁREA TÉCNICA

No.	PLANOS DE REFERENCIA	REV.
No.	MODELO BIM DE REFERENCIA	REV.
1	LT1T-1100-310-CON-ED-EST-MO-0001.rvt	V00
2	LT1T-1100-211-CON-ED-EST-MO-0001.rvt	V00
3	LT1T-1100-310-CON-ED-EST-MO-0001.rvt	V00
4	LT1T-1100-315-CON-ED-EST-MO-0001.rvt	V00
5	LT1T-1100-211-CON-ED-EST-MO-0001.rvt	V00
6	LT1T-1100-310-CON-ED-EST-MO-0001.rvt	V00
7	LT1T-1200-310-CON-ED-EST-MO-0001.rvt	V00
8	LT1T-1300-410-CON-ED-EST-MO-0001.rvt	V00
9	LT1T-1300-410-CON-ED-EST-MO-0002.rvt	V00
10	LT1T-1310-410-CON-ED-EST-MO-0001.rvt	V00
11	LT1T-1410-310-CON-ED-MEC-MO-0001.rvt	V00
12	LT1T-1420-310-CON-ED-MEC-MO-0001.rvt	V00
13	LT1T-5160-310-CON-ED-EST-MO-0001.rvt	V00
14	LT1T-5160-310-CON-ED-ARQ-MO-0001.rvt	V00
15	LT1T-5300-310-CON-ED-MEC-MO-0001.rvt	V00
16	LT1T-5600-310-CON-ED-INS-MO-0001.rvt	V00
17	LT1T-1330-410-CON-ED-ARQ-MO-0011.rvt	V00
18	LT1T-1330-410-CON-ED-ARQ-MO-0012.rvt	V00
No.	PAQUETE DE TRABAJO DE REFERENCIA	REV.
1	XREF-URBANISM_CONTEXT_ST10.rvt	-
2	XREF-SECONDARY-STRUCTURE-ST10.rvt	-



PLANO CLAVE ESTACIÓN 10

0 10m
1:200

VÁLIDO PARA CONSTRUCCIÓN
20-03-26

DISEÑO
REN ZHENHUA
Licencia de Arq.nivel I (China): 110173S-6114

APROBÓ
DIEGO ERNESTO DUEÑAS
Mat.: 25202-53876 CND

REVISÓ
CARLOS MAURICIO BARRETO BARBOSA
Mat.: A4252121411803S

DIBUJÓ
EQUIPO CHEC

REVISIÓN No.	FECHA	DESCRIPCIÓN	REVISÓ	APROBÓ
V01	20/03/2026	EMITIDO PARA CONSTRUCCIÓN	C.M.B.B	C.E.O
V00	26/02/2026	REVISIÓN NO OBJETADA - EMITIDO PARA CONSTRUCCIÓN	F.B.R	E.C.M
Vdel	31/10/2025	EMITIDO PARA REVISIÓN Y COMENTARIOS DEL CLIENTE E INTERVENTORÍA - INCLUYE COMENTARIOS GUIJOTES V3	F.B.R	E.C.M
V03	29/07/2025	EMITIDO PARA REVISIÓN Y COMENTARIOS DEL CLIENTE E INTERVENTORÍA - INCLUYE COMENTARIOS GUIJOTES V3	F.B.R	E.C.M
VP7	25/04/2023	EMITIDO PARA REVISIÓN Y COMENTARIOS DEL CLIENTE E INTERVENTORÍA - INCLUYE COMENTARIOS GUIJOTES	J.E.M	M.B.M
VP6	31/12/2022	EMITIDO PARA REVISIÓN Y COMENTARIOS DEL CLIENTE E INTERVENTORÍA - INCLUYE COMENTARIOS ACCESOS	J.E.M	M.B.M
VP5	31/10/2022	EMITIDO PARA REVISIÓN Y COMENTARIOS DEL CLIENTE E INTERVENTORÍA - INCLUYE COMENTARIOS ACCESOS	J.E.M	M.B.M
VCC	22/08/2022	EMITIDO PARA REVISIÓN Y COMENTARIOS DEL CLIENTE E INTERVENTORÍA - INCLUYE COMENTARIOS ENTREGA BIM	J.E.M	M.B.M
VBB	06/12/2021	EMITIDO PARA REVISIÓN Y COMENTARIOS DEL CLIENTE E INTERVENTORÍA	J.E.M	M.B.M
VA0	30/12/2021	EMITIDO PARA COMENTARIOS INTERNOS - EMISIÓN PRELIMINAR PARA COMENTARIOS	J.E.M	M.B.M

APROBACIÓN CLIENTE

DIRECTOR DE INTERVENTORÍA:
JAVIER DESCARGA N.
Mat.:25202-68697 CND

METRO LÍNEA 1
CONTRATO DE CONCESIÓN No. 163 DE 2019

PROYECTO PRIMERA LÍNEA DEL METRO DE BOGOTÁ - TRAMO 1

ESPECIALISTA INTERVENTORÍA:
CARLOS ALBERTO HOYOS SOTO
Mat.:A2507200G-14251682

FECHA:
MARZO 2026

INFRAESTRUCTURA VIAL
ARQUITECTURA
ESTACIÓN METRO 10 (NARIÑO)
GENERAL
VISTA EN PLANTA Y 3D - NIVEL PLATAFORMA

PLANCHA No.	ESCALA:	REVISIÓN No.	PLANO No.
	INDICADA	V01	07 DE 96
ARCHIVO: LT1T-1-0000-310-CON-ED-ARQ-MO-0001_V00.rvt	FECHA: DICIEMBRE 2021		

LT1T-1-CON-CAL-FR-0120 - B1 - 1000x707mm