L1T1-CON-CAL-FR-0120 - B1 : 1000x707mm

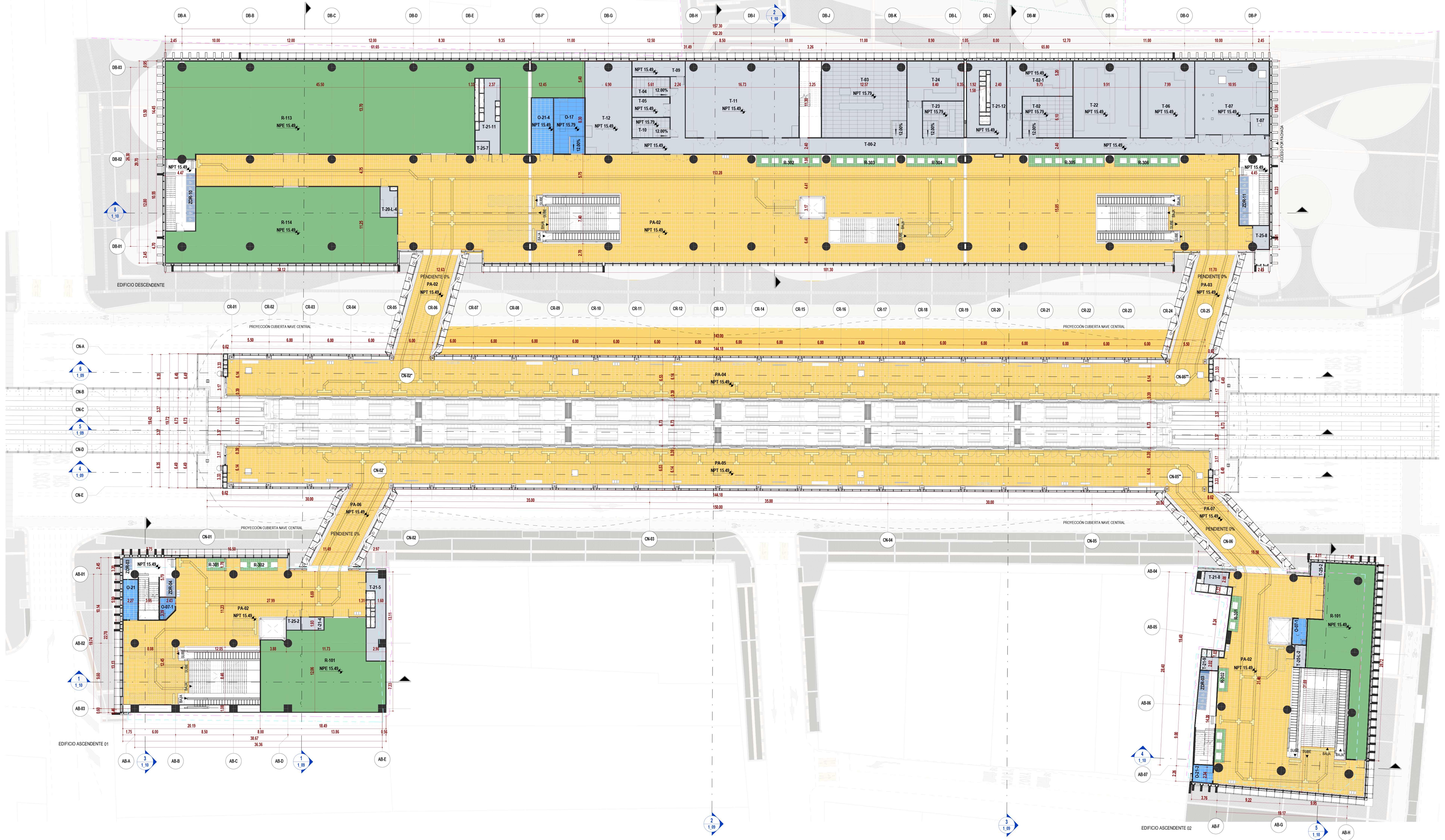

2 NIVEL PLATAFORMA_GENERAL
ESC: 1 : 200

NP

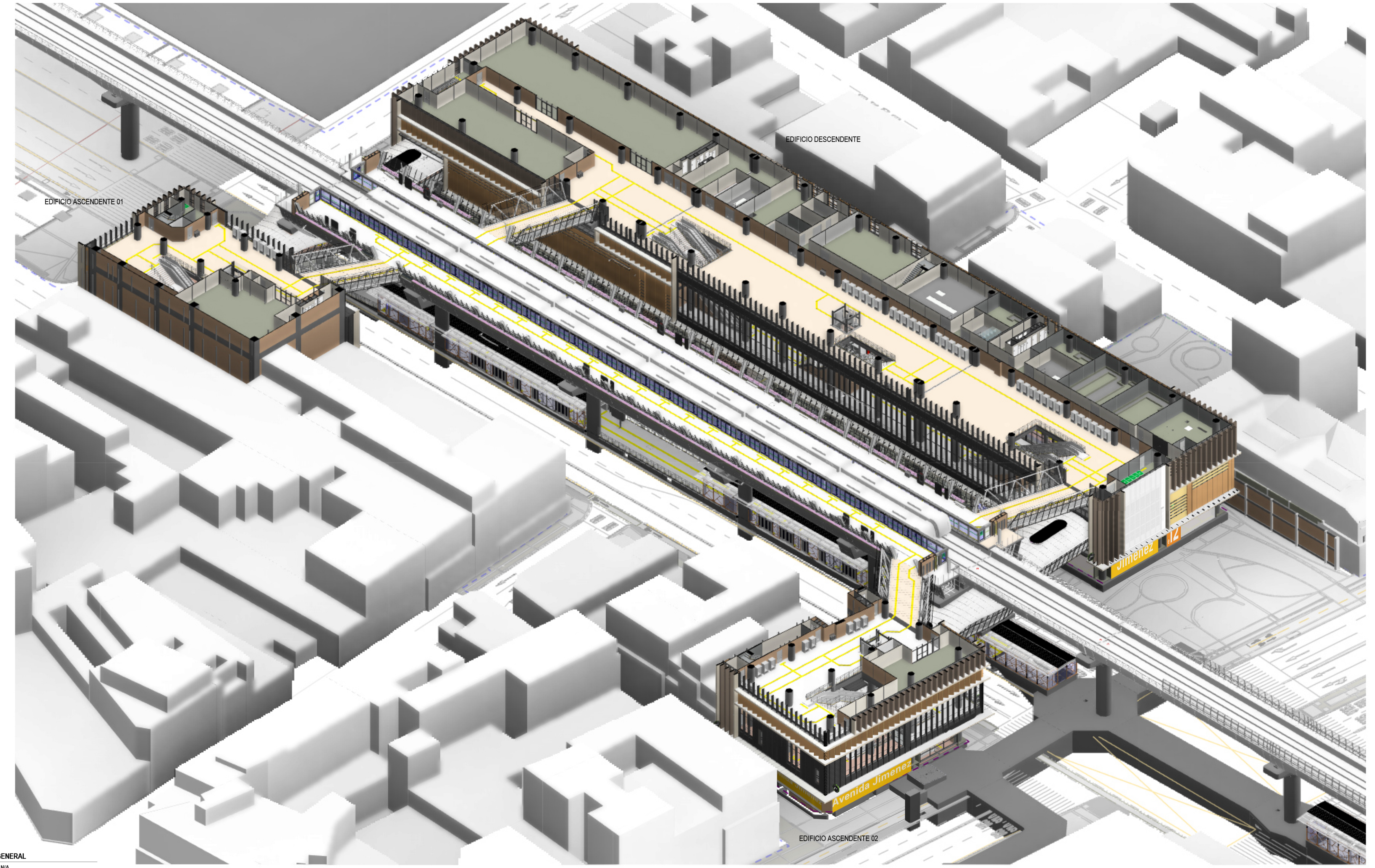

1 3D_GENERAL
ESC: N/A

LOCALIZACIÓN

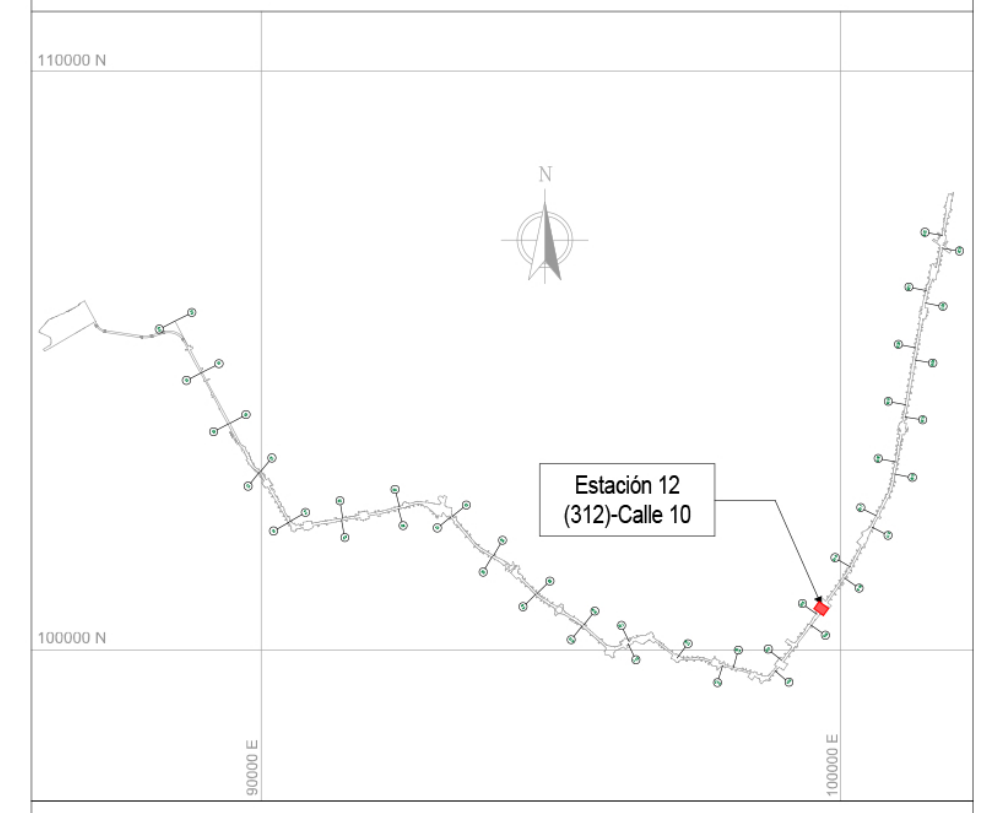

NOTAS

01 TODAS LAS DIMENSIONES ESTÁN CONFIGURADAS EN METROS A MENOS QUE SE INDIQUE UNA UNIDAD DE MEDIDA DIFERENTE.

02 TODAS LAS MEDIDAS, UBICACIÓN Y NIVELES DEBEN VERIFICARSE EN EL LUGAR DE CONSTRUCCIÓN.

03 EL NIVEL DE ACCESO AL EDIFICIO PL 01 CORRESPONDE AL +0,00 DE LA ESTACIÓN Y REFERENCIA AL NIVEL 2589.25 M.S.N.M.

04 LOS NOMBRES ESPECÍFICOS DE LAS ÁREAS PUEDEN SER CONSULTADAS EN EL PLANO NO. 3 Ó EN LAS VISTAS EN PLANTA.

05 LOS COLORES QUE SE MUESTRAN EN LOS PLANOS COMO PROYECCIÓN DE ELEMENTOS ARQUITECTÓNICOS COMO CUBIERTAS FACHADAS MUROS ETC. NO REPRESENTAN LA MATERIALIDAD Y REALIDAD DE ACABADOS DEL PROYECTO, SOLO SON INDICATIVOS PARA REALIZAR UNA CORRECTA LECTURA DE LA PLANIMETRÍA.

06 LAS ESCALERAS ELÉCTRICAS INDICAN SU SENTIDO CON LA SIGUIENTE NOMENCLATURA: "SUBE" Y "BAJA".

07 SE DEBEN REVISAR LOS NIVELES ESTRUCTURALES PARA NIVEL DE ACCESO PL_01 Y SUBNIVELES, PL_02 (INTERMEDIO), PL_03 (PLATAFORMA) CON LA PLANIMETRÍA DE PLACAS ESTRUCTURALES EN LOS ENTREGABLES L1T1-1300-412-CON-ED-EST-PL-0045, 86, 88, 129, 130, 131, 134, 135, 136, RESPECTIVAMENTE. EL NIVEL ESTRUCTURAL (NE) REFERENCIA LOS ESPACIOS DONDE SE DEBE ACONDICIONAR EL ACABADO DE PISO SEGÚN CORRESPONDA, CON LOS NIVELES DE PISO TERMINADO (NPT). LOS NIVELES PROYECTADOS DE EMPATE (NPE) EN LAS ÁREAS DE SERVICIOS ADICIONALES, REFERENCIAN LA ADECUACIÓN DE LOS DESNIVELES EN ESTAS ÁREAS; QUEDA COMO RESPONSABILIDAD DEL LOCATARIO DEFINIR Y ACONDICIONAR ESTE ACABADO DE PISO (NPE) EN LÍNEA CON EL NIVEL (NPT) DE ESPACIOS COLINDANTES. EL NIVEL ESTRUCTURAL (NE) SE ENCUENTRA A (- 0.10M) POR DEBAJO DE LOS NIVELES DE PISO TERMINADO (NPT) Y LOS NIVELES PROYECTADOS DE EMPATE (NPE) MARCADOS EN LA PLANIMETRÍA.

08 RESPECTO A LAS ÁREAS CONSTRUIDAS Y DE ACUERDO CON LA COMUNICACIÓN EXTS22-0002544 DE EMB, SE IDENTIFICA QUE EL CONCESIONARIO SE ENCUENTRA BUSCANDO ESTRATEGIAS PARA MEJORAR EL DISEÑO CON EL PROGRAMA ARQUITECTÓNICO, UNA DE ESTAS ESTRATEGIAS ES MEJORAR EL FUNCIONAMIENTO DEL DISEÑO URBANO Y BRINDAR UNA SOLUCIÓN INTEGRAL RESPECTO A LOS INMUEBLES DE INTERÉS CULTURAL. DE ACUERDO CON LO ANTERIOR, PARA LA EMB, ESTAS ACTIVIDADES OBEDECEN AL PROCESO NATURAL DE LOS ESTUDIOS Y DISEÑOS DEFINITIVOS QUE DEBE DESARROLLAR METRO LÍNEA 1.

CONVENCIONES

▬ ▬	LÍMITE DE INTERVENCIÓN
▬ ▬	HUELLA APÉNDICE TÉCNICO
▬ ▬	HUELLA LÍMITE LEVANTAMIENTO TOPOGRÁFICO
▬	MURO DIVISORIO
— —	PROYECCIÓN NIVEL SUPERIOR

🟩	SERVICIOS ADICIONALES ÁREA NO PAGA	🟨	ÁREA NO PAGA
🟩	SERVICIOS ADICIONALES ÁREA PAGA	🟦	ÁREA OPERATIVA
🟩	SERVICIO PÚBLICO	🟨	ÁREA PAGA
🟦	ZONA DE REFUGIO	🟦	ÁREA PÚBLICA
🟥	ÁREA CULTURAL	⬜	ÁREA TÉCNICA
🟩	CADE		

TABLA DE ÁREAS ÚTILES (NIVEL PLATAFORMA)

CÓDIGO	NOMBRE	ÁREA (m²)	DEPARTAMENTO
EDIFICIO ASCENDENTE 01			
ARQ_PL_03_PLATAFORMA			
O-07-1	CUARTO DE LIMPIEZA COMPLEMENTARIO	6.19	ÁREA OPERATIVA
O-21	ALMACENAMIENTO DE LA ESTACIÓN	12.54	ÁREA OPERATIVA
PA-02	ÁREA PAGA	355.86	ÁREA PAGA
R-101	SERVICIOS ADICIONALES - ÁREA DE SERVICIO	207.52	SERVICIOS ADICIONALES - ÁREA PAGA
R-301	SERVICIOS ADICIONALES - MÁQUINAS EXPENDEDORAS/CAJEROS AUTOMÁTICOS	5.24	SERVICIOS ADICIONALES - ÁREA PAGA
R-302	SERVICIOS ADICIONALES - MÁQUINAS EXPENDEDORAS/CAJEROS AUTOMÁTICOS	9.90	SERVICIOS ADICIONALES - ÁREA PAGA
T-21-4	ÁREA DE INSPECCIÓN	5.97	ÁREA TÉCNICA
T-21-5	ÁREA DE INSPECCIÓN	26.74	ÁREA TÉCNICA
T-25-2	NODO DE ACCESO DE TELECOMUNICACIONES	3.59	ÁREA TÉCNICA
ZDR-03	ZONA DE REFUGIO (PMR)	2.43	ZONA DE REFUGIO
ZDR-04	ZONA DE REFUGIO (PMR)	3.64	ZONA DE REFUGIO
EDIFICIO ASCENDENTE 02			
ARQ_PL_03_PLATAFORMA			
O-07-1	CUARTO DE LIMPIEZA COMPLEMENTARIO	7.63	ÁREA OPERATIVA
O-21-2	ALMACENAMIENTO DE LA ESTACIÓN	7.41	ÁREA OPERATIVA
PA-02	ÁREA PAGA	369.12	ÁREA PAGA
R-101	SERVICIOS ADICIONALES - ÁREA DE SERVICIO	161.88	SERVICIOS ADICIONALES - ÁREA PAGA
R-301	SERVICIOS ADICIONALES - MÁQUINAS EXPENDEDORAS/CAJEROS AUTOMÁTICOS	7.87	SERVICIOS ADICIONALES - ÁREA PAGA
R-302	SERVICIOS ADICIONALES - MÁQUINAS EXPENDEDORAS/CAJEROS AUTOMÁTICOS	5.24	SERVICIOS ADICIONALES - ÁREA PAGA
R-303	SERVICIOS ADICIONALES - MÁQUINAS EXPENDEDORAS/CAJEROS AUTOMÁTICOS	7.48	SERVICIOS ADICIONALES - ÁREA PAGA
T-20-L-2	MEDIDORES (LUZ)	5.04	ÁREA TÉCNICA
T-21-8	ÁREA DE INSPECCIÓN	6.62	ÁREA TÉCNICA
T-21-9	ÁREA DE INSPECCIÓN	4.71	ÁREA TÉCNICA
T-25-2	NODO DE ACCESO DE TELECOMUNICACIONES	3.96	ÁREA TÉCNICA
ZDR-03	ZONA DE REFUGIO (PMR)	7.80	ZONA DE REFUGIO
EDIFICIO DESCENDENTE			
ARQ_PL_03_PLATAFORMA			
O-17	OPERADORES TELECOMUNICACIONES EXTERIORES	35.37	ÁREA OPERATIVA
O-21-4	ALMACENAMIENTO DE LA ESTACIÓN	26.07	ÁREA OPERATIVA
PA-02	ÁREA PAGA	3206.23	ÁREA PAGA
R-113	SERVICIOS ADICIONALES - ÁREA DE SERVICIO	721.07	SERVICIOS ADICIONALES - ÁREA PAGA
R-114	SERVICIOS ADICIONALES - ÁREA DE SERVICIO	333.52	SERVICIOS ADICIONALES - ÁREA PAGA
R-302	SERVICIOS ADICIONALES - MÁQUINAS EXPENDEDORAS/CAJEROS AUTOMÁTICOS	17.28	SERVICIOS ADICIONALES - ÁREA PAGA

TABLA DE ÁREAS ÚTILES (NIVEL PLATAFORMA)

CÓDIGO	NOMBRE	ÁREA (m²)	DEPARTAMENTO
R-303	SERVICIOS ADICIONALES - MÁQUINAS EXPENDEDORAS/CAJEROS AUTOMÁTICOS	17.12	SERVICIOS ADICIONALES - ÁREA PAGA
R-304	SERVICIOS ADICIONALES - MÁQUINAS EXPENDEDORAS/CAJEROS AUTOMÁTICOS	13.45	SERVICIOS ADICIONALES - ÁREA PAGA
R-305	SERVICIOS ADICIONALES - MÁQUINAS EXPENDEDORAS/CAJEROS AUTOMÁTICOS	20.23	SERVICIOS ADICIONALES - ÁREA PAGA
R-306	SERVICIOS ADICIONALES - MÁQUINAS EXPENDEDORAS/CAJEROS AUTOMÁTICOS	17.30	SERVICIOS ADICIONALES - ÁREA PAGA
T-00-2	CIRCULACIÓN TÉCNICA	256.77	ÁREA TÉCNICA
T-02	LOCAL DE CONDUCCIÓN AUTOMÁTICA (CBTC)	43.67	ÁREA TÉCNICA
T-02-1	UPS DEDICADA (CBTC)	53.09	ÁREA TÉCNICA
T-03	TELECOMUNICACIONES ESTACIÓN - CORRIENTE DÉBIL	136.53	ÁREA TÉCNICA
T-04	EQUIPO BOLETERÍA	15.36	ÁREA TÉCNICA
T-05	ALMACÉN PARA MANTENIMIENTO	15.79	ÁREA TÉCNICA
T-06	SALA DE TABLEROS	86.67	ÁREA TÉCNICA
T-07	CENTRO DE TRANSFORMACIÓN (CT)	114.35	ÁREA TÉCNICA
T-09	ALMACÉN EQUIPO ELÉCTRICO	16.95	ÁREA TÉCNICA
T-10	CUARTO DE EQUIPO ELECTROMECÁNICO	15.81	ÁREA TÉCNICA
T-11	CUARTO DE VENTILACIÓN	182.34	ÁREA TÉCNICA
T-12	PLANTA DE REFRIGERACIÓN PARA LA CLIMATIZACIÓN	90.70	ÁREA TÉCNICA
T-20-L-4	MEDIDORES (LUZ)	10.04	ÁREA TÉCNICA
T-21-11	ÁREA DE INSPECCIÓN	24.23	ÁREA TÉCNICA
T-21-12	ÁREA DE INSPECCIÓN	50.28	ÁREA TÉCNICA
T-22	CUARTO DE UPS	108.11	ÁREA TÉCNICA
T-23	CUARTO PDAP	31.38	ÁREA TÉCNICA
T-24	TETRA UPS	46.81	ÁREA TÉCNICA
T-25-7	NODO DE ACCESO DE TELECOMUNICACIONES	3.56	ÁREA TÉCNICA
T-25-8	NODO DE ACCESO DE TELECOMUNICACIONES	7.42	ÁREA TÉCNICA
ZDR-10	ZONA DE REFUGIO (PMR)	9.72	ZONA DE REFUGIO
ZDR-11	ZONA DE REFUGIO (PMR)	9.70	ZONA DE REFUGIO
NAVE CENTRAL			
ARQ_PL_03_PLATAFORMA			
PA-02	ÁREA PAGA	84.86	ÁREA PAGA
PA-03	ÁREA PAGA	83.34	ÁREA PAGA
PA-04	ÁREA PAGA	759.68	ÁREA PAGA
PA-05	ÁREA PAGA	759.68	ÁREA PAGA
PA-06	ÁREA PAGA	68.65	ÁREA PAGA
PA-07	ÁREA PAGA	79.78	ÁREA PAGA
TOTAL NIVEL PLATAFORMA		8807.30	

TABLA DE ÁREAS ÚTILES POR DEPARTAMENTO (NIVEL PLATAFORMA)

DEPARTAMENTO	ÁREA (m²)
EDIFICIO ASCENDENTE 01	
ARQ_PL_03_PLATAFORMA	
SERVICIOS ADICIONALES - ÁREA PAGA	222.66
ZONA DE REFUGIO	6.07
ÁREA OPERATIVA	18.73
ÁREA PAGA	355.86
ÁREA TÉCNICA	36.30
EDIFICIO ASCENDENTE 02	
ARQ_PL_03_PLATAFORMA	
SERVICIOS ADICIONALES - ÁREA PAGA	182.47
ZONA DE REFUGIO	7.80
ÁREA OPERATIVA	15.04
ÁREA PAGA	369.12
ÁREA TÉCNICA	20.33
EDIFICIO DESCENDENTE	
ARQ_PL_03_PLATAFORMA	
SERVICIOS ADICIONALES - ÁREA PAGA	1139.98
ZONA DE REFUGIO	19.42
ÁREA OPERATIVA	61.44
ÁREA PAGA	3206.23
ÁREA TÉCNICA	1309.87
NAVE CENTRAL	
ARQ_PL_03_PLATAFORMA	
ÁREA PAGA	1836.00
TOTAL NIVEL PLATAFORMA	8807.30

TABLA GENERAL DE NIVELES

NOMBRE	NIVEL	ELEVACIÓN (m)
ARQ_PL_05_CUB_NVC	CUBIERTA NAVE CENTRAL	24.75
ARQ_PL_04_CUB_EDIFICACIONES	CUBIERTA EDIFICACIONES	22.09
ARQ_PL_02.2_TOR	TOPE DE RIEL	14.35
ARQ_PL_03_PLATAFORMA	PLATAFORMA	15.49
ARQ_PL_02_INTERMEDIO	INTERMEDIO	6.75
ARQ_PL_00.1_ACCESO	ACCESO	-2.40
ARQ_PL_00.2_ACCESO	ACCESO	-2.10
ARQ_PL_00.3_ACCESO	ACCESO	-1.85
ARQ_PL_00.4_ACCESO	ACCESO	-1.65
ARQ_PL_00.5_ACCESO	ACCESO	-1.45
ARQ_PL_00.6_ACCESO	ACCESO	-1.25
ARQ_PL_00.7_ACCESO	ACCESO	-0.85
ARQ_PL_00.8_ACCESO	ACCESO	-0.45
ARQ_PL_00.9_ACCESO	ACCESO	-0.20
ARQ_PL_00.10_ACCESO	ACCESO	-0.15
ARQ_PL_01.1_ACCESO	ACCESO	0.97
ARQ_PL_01_ACCESO	ACCESO*	2589.25 M.S.N.M
ARQ_PL_00.1_SÓTANO	SÓTANO	-7.93
ARQ_PL_00.2_SÓTANO	SÓTANO	-7.45
ARQ_PL_00.3_SÓTANO	SÓTANO	-6.98
ARQ_PL_00.4_SÓTANO	SÓTANO	-6.50
ARQ_PL_00.5_SÓTANO	SÓTANO	-4.70
ARQ_PL_00_SÓTANO	SÓTANO	-8.40

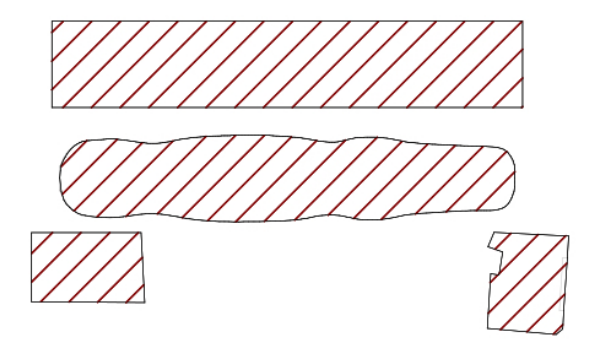

PLANO CLAVE ESTACIÓN 12

VÁLIDO PARA CONSTRUCCIÓN
31-03-26

No.	PLANOS DE REFERENCIA	REV.

No.	MODELO BIM DE REFERENCIA	REV.
1	L1T1-1100-212-CON-ED-EST-MO-0001.rvt	V00
2	L1T1-1100-213-CON-ED-EST-MO-0001.rvt	V00
3	L1T1-1100-312-CON-ED-EST-MO-0001.rvt	V00
4	L1T1-1150-212-CON-ED-EST-MO-0001.rvt	V00
5	L1T1-1150-213-CON-ED-EST-MO-0001.rvt	V00
6	L1T1-1150-312-CON-ED-EST-MO-0001.rvt	V00
7	L1T1-1200-312-CON-ED-EST-MO-0001.rvt	V00
8	L1T1-1300-412-CON-ED-EST-MO-0001.rvt	V00
9	L1T1-1300-412-CON-ED-EST-MO-0002.rvt	V00
10	L1T1-1300-412-CON-ED-EST-MO-0003.rvt	V00
11	L1T1-1310-412-CON-ED-EST-MO-0001.rvt	V00
12	L1T1-1410-312-CON-ED-MEC-MO-0001.rvt	V00
13	L1T1-1420-312-CON-ED-MEC-MO-0001.rvt	V00
14	L1T1-2320-584-CON-ED-EST-MO-0001.rvt	V00
15	L1T1-2330-584-CON-ED-ARQ-MO-0001.rvt	V00
16	L1T1-2430-551-CON-ED-ARQ-MO-0001.rvt	V00
17	L1T1-2430-551-CON-ED-EST-MO-0001.rvt	V00
18	L1T1-5160-312-CON-ED-ARQ-MO-0001.rvt	V00
19	L1T1-5160-312-CON-ED-EST-MO-0001.rvt	V00
20	L1T1-5300-312-CON-ED-MEC-MO-0001.rvt	V00
21	L1T1-5600-312-CON-ED-INS-MO-0001.rvt	V00
22	L1T1-1330-412-CON-ED-ARQ-MO-0011.rvt	V00
23	L1T1-1330-412-CON-ED-ARQ-MO-0012.rvt	V00
24	L1T1-1330-412-CON-ED-ARQ-MO-0013.rvt	V00

No.	PAQUETE DE TRABAJO DE REFERENCIA	REV.
1	XREF-URBANISM_CONTEXT_ST12.rvt	
2	XREF-SECONDARY-STRUCTURE-ST12.rvt	

0 2 10m
1:200

METRO BOGOTÁ
GCS Consorcio Consultores PMO Bogotá
CONSORCIO SUPERVISOR PLMB
CHEC

DISEÑÓ:
REN ZHENHUA
Licencia de Arq.nivel I (China): 1101735-614

APROBÓ:
DIEGO ERNESTO DUEÑAS
Mat.: 25202-53876 CND

REVISÓ:
CARLOS MAURICIO BARRETO BARBOSA
Mat.: A4012012-14139353

DIBUJÓ:
EQUIPO CHEC

REVISIÓN No.	FECHA	DESCRIPCIÓN	REVISÓ	APROBÓ	APROBACIÓN CLIENTE
V02	31/03/2026	EMITIDO PARA CONSTRUCCIÓN	C.M.B.B	D.E.D	
V01	16/07/2025	REVISIÓN NO OBJETADA - EMITIDO PARA CONSTRUCCIÓN	F.B.R	M.M.R	
VB1	20/03/2025	EMITIDO PARA REVISIÓN Y COMENTARIOS DEL CLIENTE E INTERVENTORÍA	F.B.R	E.O.M	
V00	13/02/2025	REVISIÓN NO OBJETADA - EMITIDO PARA CONSTRUCCIÓN	F.B.R	E.O.M	
VGG	18/10/2024	EMITIDO PARA REVISIÓN Y COMENTARIOS DEL CLIENTE E INTERVENTORÍA - INCLUYE COMENTARIOS /(AJUSTES V2)	F.B.R	E.O.M	
VFF	21/05/2024	EMITIDO PARA REVISIÓN Y COMENTARIOS DEL CLIENTE E INTERVENTORÍA - INCLUYE COMENTARIOS /(AJUSTES)	F.B.R	E.O.M	
VEE	25/01/2023	EMITIDO PARA REVISIÓN Y COMENTARIOS DEL CLIENTE E INTERVENTORÍA - INCLUYE COMENTARIOS /(90% ACCESOS)	J.E.M	M.B.M	
VDD	18/12/2022	EMITIDO PARA REVISIÓN Y COMENTARIOS DEL CLIENTE E INTERVENTORÍA - INCLUYE COMENTARIOS /(NAVE CENTRAL)	J.E.M	M.B.M	
VCC	22/08/2022	EMITIDO PARA REVISIÓN Y COMENTARIOS DEL CLIENTE E INTERVENTORÍA - INCLUYE COMENTARIOS /(ENTREGA 90%)	J.E.M	M.B.M	
VBB	06/12/2021	EMITIDO PARA REVISIÓN Y COMENTARIOS DEL CLIENTE E INTERVENTORÍA	J.E.M	M.B.M	

METRO LÍNEA 1

DIRECTOR DE INTERVENTORÍA:
JAVIER DESCARGA N.
Mat.:25202-68697 CND

METRO LÍNEA 1
CONTRATO DE CONCESIÓN No. 163 DE 2019

PROYECTO PRIMERA LÍNEA DEL METRO DE BOGOTÁ - TRAMO 1

ESPECIALISTA INTERVENTORÍA:
CARLOS ALBERTO HOYOS SOTO
Mat.:A25072000-14251682

FECHA:
MARZO 2026

INFRAESTRUCTURA VIAL
ARQUITECTURA

ESTACIÓN METRO 12 - (CALLE 10)
NAVE CENTRAL - EDIFICIO ASCENDENTE 01 - EDIFICIO ASCENDENTE 02 - EDIFICIO DESCENDENTE
VISTA EN PLANTA Y 3D - NIVEL PLATAFORMA

PLANCHA No: L1T1-0000-312-CON-ED-ARQ-PL-0001_07_V02
ARCHIVO: L1T1-0000-312-CON-ED-ARQ-MO-0001_V01.rvt
ESCALA: INDICADA
FECHA: DICIEMBRE 2021
REVISIÓN No. V02
PLANO No. 07 DE 100