L1T1-CON-CAL-FR-0120 - B1 : 1000x707mm

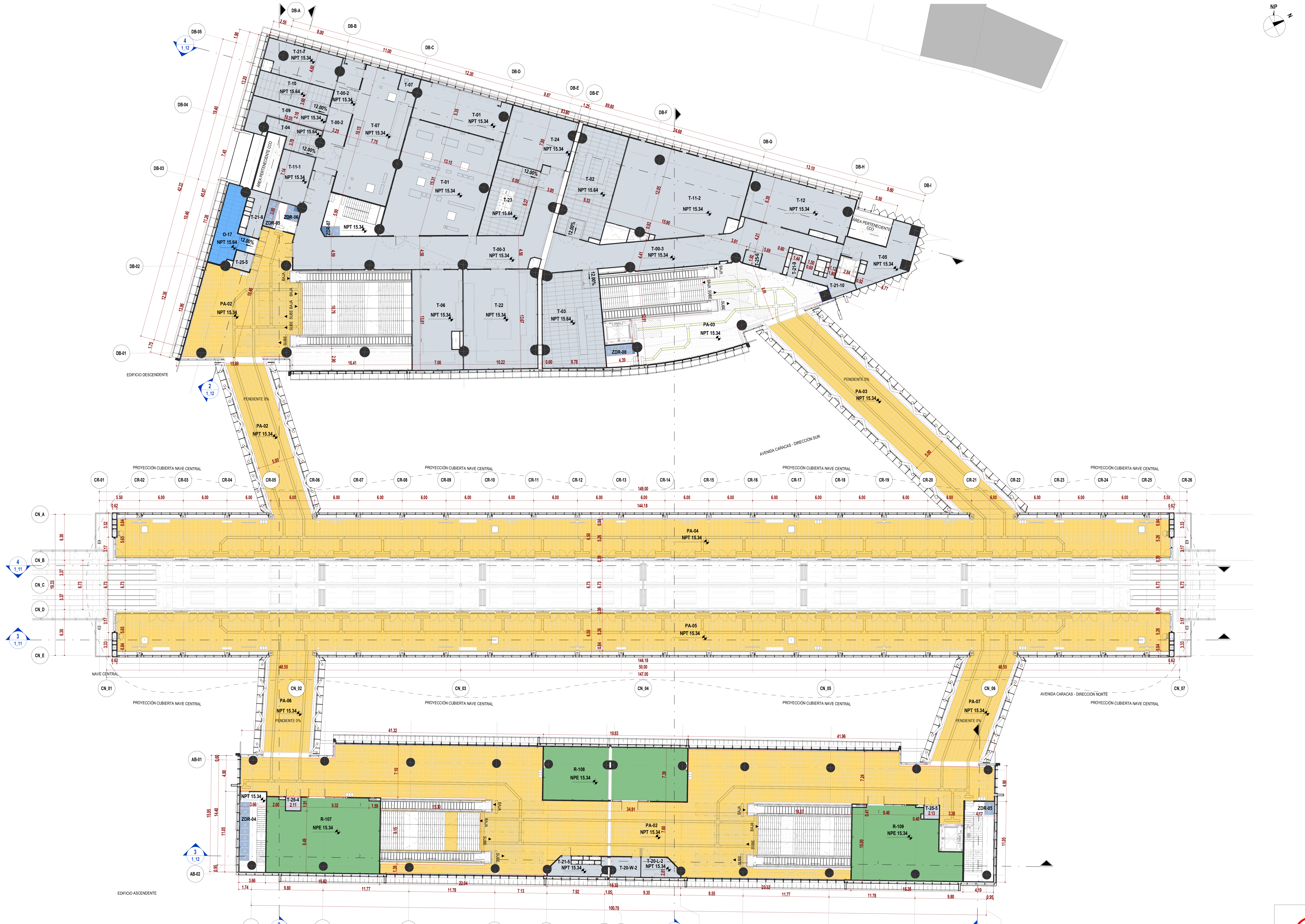

2 NIVEL PLATAFORMA_GENERAL
ESC: 1 : 200

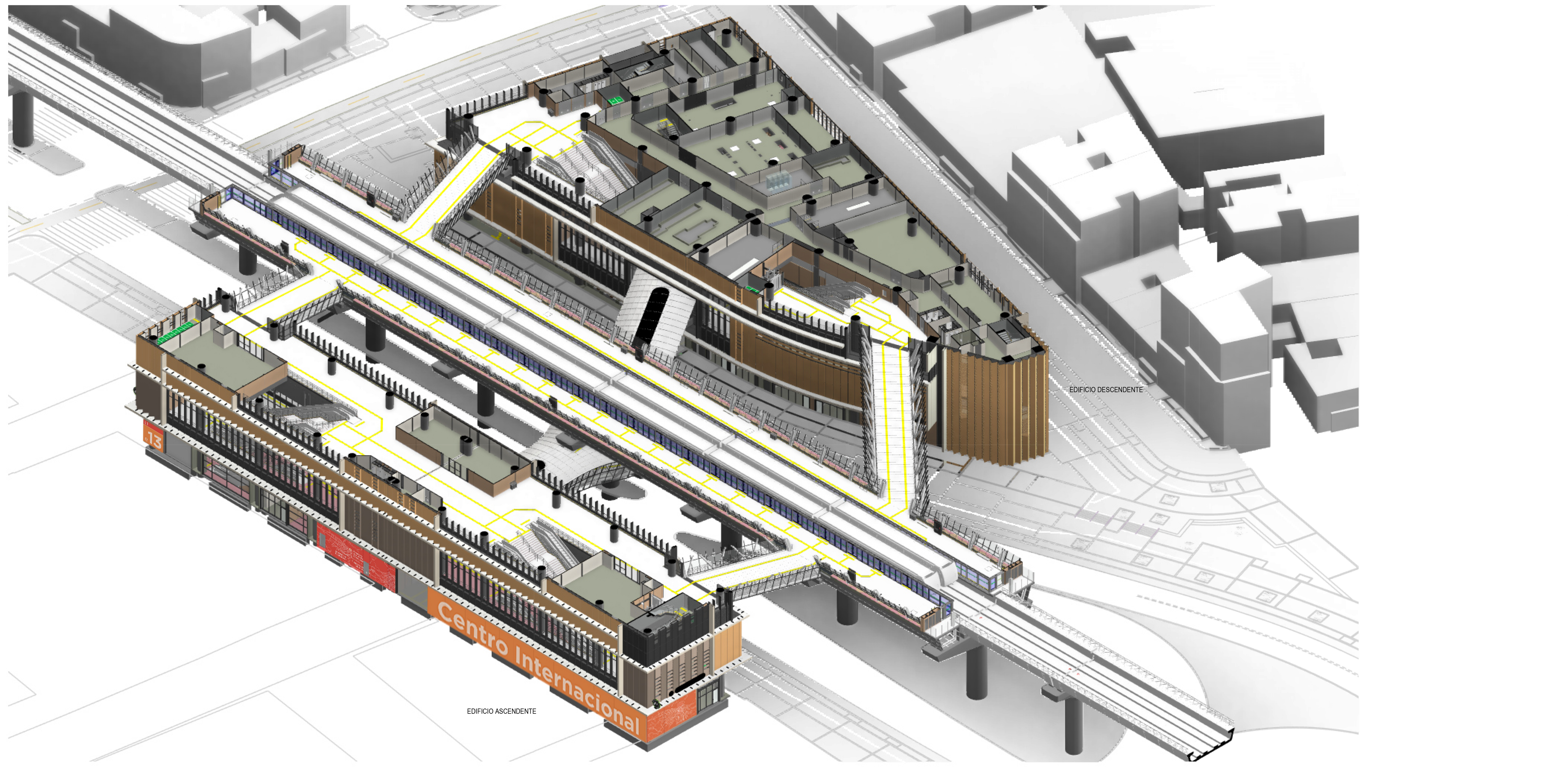

1 3D_NIVEL PLATAFORMA_GENERAL
ESC: N/A

TABLA DE ÁREAS ÚTILES (NIVEL PLATAFORMA)

CÓDIGO	NOMBRE	AREA (m²)	DEPARTAMENTO
EDIFICIO ASCENDENTE			
ARQ_PL_03_PLATAFORMA			
PA-02	ÁREA PAGA	1046.48	ÁREA PAGA
R-107	SERVICIOS ADICIONALES - ÁREA DE SERVICIO	152.57	SERVICIOS ADICIONALES - ÁREA PAGA
R-108	SERVICIOS ADICIONALES - ÁREA DE SERVICIO	138.08	SERVICIOS ADICIONALES - ÁREA PAGA
R-109	SERVICIOS ADICIONALES - ÁREA DE SERVICIO	127.91	SERVICIOS ADICIONALES - ÁREA PAGA
T-20-L-2	MEDIDORES (LUZ)	12.41	ÁREA TÉCNICA
T-20-W-2	MEDIDORES (AGUA)	11.81	ÁREA TÉCNICA
T-21-5	ÁREA DE INSPECCIÓN	13.13	ÁREA TÉCNICA
T-25-4	NODO DE ACCESO DE TELECOMUNICACIONES	3.57	ÁREA TÉCNICA
T-25-5	NODO DE ACCESO DE TELECOMUNICACIONES	3.57	ÁREA TÉCNICA
ZDR-04	ZONA DE REFUGIO (PMR)	10.94	ZONA DE REFUGIO
ZDR-05	ZONA DE REFUGIO (PMR)	2.43	ZONA DE REFUGIO
EDIFICIO DESCENDENTE			
ARQ_PL_03_PLATAFORMA			
O-17	OPERADORES TELECOMUNICACIONES EXTERIORES	33.84	ÁREA OPERATIVA
PA-02	ÁREA PAGA	194.87	ÁREA PAGA
T-00-2	CIRCULACIÓN TÉCNICA	48.40	ÁREA TÉCNICA
T-00-3	CIRCULACIÓN TÉCNICA	366.66	ÁREA TÉCNICA
T-01	SUBESTACIÓN DE TRACCIÓN (SET)	257.46	ÁREA TÉCNICA
T-02	LOCAL DE CONDUCCIÓN AUTOMÁTICA (CBTC)	94.11	ÁREA TÉCNICA

TABLA DE ÁREAS ÚTILES (NIVEL PLATAFORMA)

CÓDIGO	NOMBRE	AREA (m²)	DEPARTAMENTO
T-03	TELECOMUNICACIONES ESTACIÓN - CORRIENTE DÉBIL	103.64	ÁREA TÉCNICA
T-04	EQUIPO BOLETERÍA	21.52	ÁREA TÉCNICA
T-05	ALMACÉN PARA MANTENIMIENTO	46.65	ÁREA TÉCNICA
T-06	SALA DE TABLEROS	89.44	ÁREA TÉCNICA
T-07	CENTRO DE TRANSFORMACIÓN (CT)	135.17	ÁREA TÉCNICA
T-09	ALMACÉN EQUIPO ELÉCTRICO	27.72	ÁREA TÉCNICA
T-10	CUARTO DE EQUIPO ELECTROMECÁNICO	36.18	ÁREA TÉCNICA
T-11-1	CUARTO DE VENTILACIÓN	30.68	ÁREA TÉCNICA
T-11-2	CUARTO DE VENTILACIÓN	188.05	ÁREA TÉCNICA
T-12	PLANTA DE REFRIGERACIÓN PARA LA CLIMATIZACIÓN	84.65	ÁREA TÉCNICA
T-21-7	ÁREA DE INSPECCIÓN	42.16	ÁREA TÉCNICA
T-21-8	ÁREA DE INSPECCIÓN	12.60	ÁREA TÉCNICA
T-21-9	ÁREA DE INSPECCIÓN	3.97	ÁREA TÉCNICA
T-21-10	ÁREA DE INSPECCIÓN	16.49	ÁREA TÉCNICA
T-22	CUARTO DE UPS	134.15	ÁREA TÉCNICA
T-23	CUARTO PDAP	58.29	ÁREA TÉCNICA
T-24	TETRA UPS	66.11	ÁREA TÉCNICA
T-25-5	NODO DE ACCESO DE TELECOMUNICACIONES	5.67	ÁREA TÉCNICA
T-25-6	NODO DE ACCESO DE TELECOMUNICACIONES	3.95	ÁREA TÉCNICA
ZDR-05	ZONA DE REFUGIO (PMR)	5.06	ZONA DE REFUGIO
ZDR-06	ZONA DE REFUGIO (PMR)	3.56	ZONA DE REFUGIO
ZDR-07	ZONA DE REFUGIO (PMR)	3.27	ZONA DE REFUGIO
ZDR-08	ZONA DE REFUGIO (PMR)	5.40	ZONA DE REFUGIO
NAVE CENTRAL			
ARQ_PL_03_PLATAFORMA			
PA-02	ÁREA PAGA	112.41	ÁREA PAGA
PA-03	ÁREA PAGA	198.13	ÁREA PAGA
PA-04	ÁREA PAGA	759.68	ÁREA PAGA
PA-05	ÁREA PAGA	759.68	ÁREA PAGA
PA-06	ÁREA PAGA	86.45	ÁREA PAGA
PA-07	ÁREA PAGA	99.54	ÁREA PAGA
TOTAL NIVEL PLATAFORMA		5658.50	

TABLA DE ÁREAS POR DEPARTAMENTO (NIVEL PLATAFORMA)

DEPARTAMENTO	ÁREA (m²)
EDIFICIO ASCENDENTE	
ARQ_PL_03_PLATAFORMA	
SERVICIOS ADICIONALES - ÁREA PAGA	418.56
ZONA DE REFUGIO	13.36
ÁREA PAGA	1046.48
ÁREA TÉCNICA	44.49
EDIFICIO DESCENDENTE	
ARQ_PL_03_PLATAFORMA	
ZONA DE REFUGIO	17.29
ÁREA OPERATIVA	33.84
ÁREA PAGA	194.87
ÁREA TÉCNICA	1873.71
NAVE CENTRAL	
ARQ_PL_03_PLATAFORMA	
ÁREA PAGA	2015.88
TOTAL NIVEL PLATAFORMA	5658.50

LOCALIZACIÓN

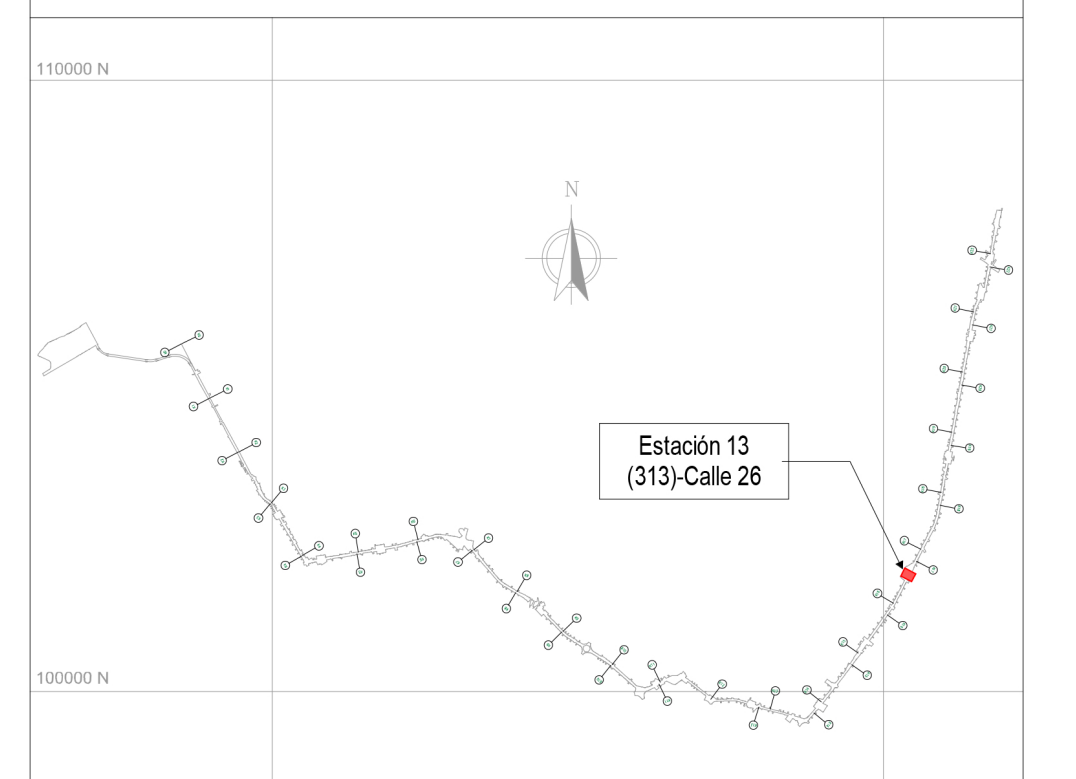

NOTAS

01 TODAS LAS DIMENSIONES ESTÁN CONFIGURADAS EN METROS A MENOS QUE SE INDIQUE UNA UNIDAD DE MEDIDA DIFERENTE.

02 TODAS LAS MEDIDAS, UBICACIÓN Y NIVELES DEBEN VERIFICARSE EN EL LUGAR DE CONSTRUCCIÓN.

03 EL NIVEL DE ACCESO AL EDIFICIO PL 01 CORRESPONDE AL +0,00 DE LA ESTACIÓN Y REFERENCIA AL NIVEL 2591.30 M.S.N.M.

04 LOS NOMBRES ESPECIFICOS DE LAS ÁREAS PUEDEN SER CONSULTADAS EN EL PLANO NO. 3 Ó EN LAS VISTAS EN PLANTA.

05 LOS COLORES QUE SE MUESTRAN EN LOS PLANOS COMO PROYECCIÓN DE ELEMENTOS ARQUITECTÓNICOS COMO CUBIERTAS FACHADAS MUROS ETC. NO REPRESENTAN LA MATERIALIDAD Y REALIDAD DE ACABADOS DEL PROYECTO, SOLO SON INDICATIVOS PARA REALIZAR UNA CORRECTA LECTURA DE LA PLANIMETRÍA.

06 LAS ESCALERAS ELÉCTRICAS INDICAN SU SENTIDO CON LA SIGUIENTE NOMENCLATURA: "SUBE" Y "BAJA".

07 SE DEBEN REVISAR LOS NIVELES ESTRUCTURALES PARA NIVEL DE ACCESO PL_01 Y SUBNIVELES, PL_02 (INTERMEDIO), PL_03 (PLATAFORMA) CON LA PLANIMETRÍA DE PLACAS ESTRUCTURALES EN LOS ENTREGABLES L1T1-1300-413-CON-ED-EST-PL-0046, 45, 47, 67, 68, 69, 70, 71, 91 RESPECTIVAMENTE. EL NIVEL ESTRUCTURAL (NE) REFERENCIA LOS ESPACIOS DONDE SE DEBE ACONDICIONAR EL ACABADO DE PISO SEGÚN CORRESPONDA, CON LOS NIVELES DE PISO TERMINADO (NPT). LOS NIVELES PROYECTADOS DE EMPATE (NPE) EN LAS ÁREAS DE SERVICIOS ADICIONALES, REFERENCIAN LA ADECUACIÓN DE LOS DESNIVELES EN ESTAS ÁREAS; QUEDA COMO RESPONSABILIDAD DEL LOCATARIO DEFINIR Y ACONDICIONAR ESTE ACABADO DE PISO (NPE) EN LÍNEA CON EL NIVEL (NPT) DE ESPACIOS COLINDANTES. EL NIVEL ESTRUCTURAL (NE) SE ENCUENTRA A (- 0.10M) POR DEBAJO DE LOS NIVELES DE PISO TERMINADO (NPT) Y LOS NIVELES PROYECTADOS DE EMPATE (NPE) MARCADOS EN LA PLANIMETRÍA.

- ARQ_PL_00 = SÓTANO / NPT -9.10m
- ARQ_PL_00.1 = ACCESO / NPT -2.80m
- ARQ_PL_00.2 = ACCESO / NPT -2.30m
- ARQ_PL_00.3 = ACCESO / NPT -1.50m
- ARQ_PL_00.4 = ACCESO / NPT -0.90m
- ARQ_PL_00.5 = ACCESO / NPT -0.75m
- ARQ_PL_00.6 = ACCESO / NPT -0.50m
- ARQ_PL_00.7 = ACCESO / NPT -0.30m
- ARQ_PL_01 = ACCESO / NPT 0.00m
- ARQ_PL_02 = INTERMEDIO / NPT 6.60m
- ARQ_PL_02.2 = TOPE DE RIEL (TOR) / NPT 14.20m
- ARQ_PL_03 = PLATAFORMA/ NIVEL 1 CCO / NPT 15.34m
- ARQ_PL_04 = CUBIERTA EDIFICIO ASCENDENTE / NPT 21.94m
- ARQ_PL_05 = CUBIERTA NAVE CENTRAL / NPT 24.60m
- ARQ_PL_06 = NIVEL 2 CCO / NPT 28.54m
- ARQ_PL_07 = CUBIERTA EDIFICIO ASCENDENTE / NPT 36.84m

CONVENCIONES

- - - -	LÍMITE DE INTERVENCIÓN
- - - -	HUELLA APÉNDICE TÉCNICO
▬	MURO DIVISORIO
— — —	PROYECCIÓN NIVEL SUPERIOR
🟩	SERVICIOS ADICIONALES - ÁREA NO PAGA
🟩	SERVICIOS ADICIONALES - ÁREA PAGA
🟥	ÁREA CULTURAL
🟦	ÁREA OPERATIVA
🟨	ÁREA PAGA
🟨	ÁREA NO PAGA
🟦	ÁREA PÚBLICA
🟩	SERVICIO PÚBLICO
🟦	ZONA DE REFUGIO
⬜	ÁREA TÉCNICA
🟦	SERVICIOS ADICIONALES - ÁREA DE OFICINAS

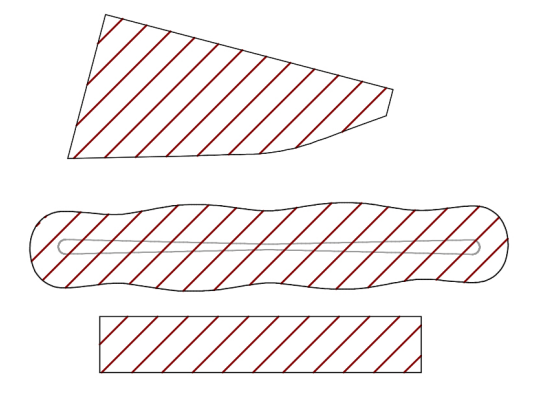

PLANO CLAVE ESTACIÓN 13

No.	PLANOS DE REFERENCIA	REV.

No.	MODELO BIM DE REFERENCIA	REV.
1	L1T1-1100-213-CON-ED-EST-MO-0001.rvt	V00
2	L1T1-1100-214-CON-ED-EST-MO-0001.rvt	V00
3	L1T1-1100-313-CON-ED-EST-MO-0001.rvt	V00
4	L1T1-1150-213-CON-ED-EST-MO-0001.rvt	V00
5	L1T1-1150-214-CON-ED-EST-MO-0001.rvt	V00
6	L1T1-1150-313-CON-ED-EST-MO-0001.rvt	V00
7	L1T1-1200-313-CON-ED-EST-MO-0001.rvt	V00
8	L1T1-1300-413-CON-ED-EST-MO-0001.rvt	V00
9	L1T1-1300-413-CON-ED-EST-MO-0002.rvt	V00
10	L1T1-1310-413-CON-ED-EST-MO-0001.rvt	V00
11	L1T1-1410-313-CON-ED-MEC-MO-0001.rvt	V00
12	L1T1-1420-313-CON-ED-MEC-MO-0001.rvt	V00
13	L1T1-5160-313-CON-ED-EST-MO-0001.rvt	V00
14	L1T1-5160-313-CON-ED-ARQ-MO-0001.rvt	V00
15	L1T1-5300-313-CON-ED-MEC-MO-0001.rvt	V00
16	L1T1-5600-313-CON-ED-INS-MO-0001.rvt	V00
17	L1T1-1330-413-CON-ED-ARQ-MO-0011.rvt	V00
18	L1T1-1330-413-CON-ED-ARQ-MO-0012.rvt	V00

No.	PAQUETE DE TRABAJO DE REFERENCIA	REV.
1	XREF-URBANISM-CONTEXT-ST13.rvt	
2	XREF-SECONDARY-STRUCTURE-ST13.rvt	

0 2 10m
1:200

VÁLIDO PARA CONSTRUCCIÓN
31-03-26

METRO BOGOTÁ · GCS Consorcio Consultores PMO Bogotá · CONSORCIO SUPERVISOR PLMB · CHEC

DISEÑÓ:
REN ZHENHUA
Licencia de Arq.nivel I (China): 1101735-614

APROBÓ:
DIEGO ERNESTO DUEÑAS
Mat.: 25202-53876 CND

REVISÓ:
CARLOS MAURICIO BARRETO BARBOSA
Mat.: A4012012-14139353

DIBUJÓ:
EQUIPO CHEC

REVISIÓN No.	FECHA	DESCRIPCIÓN	REVISÓ	APROBÓ	APROBACIÓN CLIENTE
V01	31/03/2026	EMITIDO PARA CONSTRUCCIÓN	C.M.B.B	D.E.D	
V00	13/05/2025	REVISION NO OBJETADA - EMITIDO PARA CONSTRUCCION	F.B.R	E.O.M	
VGG	09/09/2024	EMITIDO PARA REVISIÓN Y COMENTARIOS DEL CLIENTE E INTERVENTORÍA -INCLUYE COMENTARIOS /(AJUSTES V3)	F.B.R	E.O.M	
VFF	04/06/2024	EMITIDO PARA REVISIÓN Y COMENTARIOS DEL CLIENTE E INTERVENTORÍA -INCLUYE COMENTARIOS /(AJUSTES V2)	F.B.R	E.O.M	
VEE	06/01/2023	EMITIDO PARA REVISIÓN Y COMENTARIOS DEL CLIENTE E INTERVENTORÍA -INCLUYE COMENTARIOS /(90% ACCESOS)	J.E.M	M.B.M	
VDD	18/12/2022	EMITIDO PARA REVISIÓN Y COMENTARIOS DEL CLIENTE E INTERVENTORÍA - INCLUYE COMENTARIOS /(NAVE CENTRAL)	J.E.M	M.B.M	
VCC	22/08/2022	EMITIDO PARA REVISIÓN Y COMENTARIOS DEL CLIENTE E INTERVENTORÍA - INCLUYE COMENTARIOS /(ENTREGA 90%)	J.E.M	M.B.M	
VBB	06/12/2021	EMITIDO PARA REVISIÓN Y COMENTARIOS DEL CLIENTE E INTERVENTORÍA	J.E.M	M.B.M	
VA0	05/12/2021	EMITIDO PARA COMENTARIOS INTERNOS - EMISIÓN PRELIMINAR PARA COMENTARIOS	J.E.M	M.B.M	

METRO LÍNEA 1

METRO LÍNEA 1
CONTRATO DE CONCESIÓN No. 163 DE 2019

PROYECTO PRIMERA LÍNEA DEL METRO DE BOGOTÁ - TRAMO 1

DIRECTOR DE INTERVENTORÍA:
JAVIER DESCARGA N.
Mat.:25202-68697 CND

ESPECIALISTA INTERVENTORÍA:
CARLOS ALBERTO HOYOS SOTO
Mat.:A25072000-14251682

FECHA:
MARZO 2026

INFRAESTRUCTURA VIAL
ARQUITECTURA
ESTACIÓN METRO 13 (CALLE 26)
GENERAL
VISTA EN PLANTA Y 3D - NIVEL PLATAFORMA

PLANCHA No:	ESCALA:	REVISIÓN No.	PLANO No.
L1T1-0000-313-CON-ED-ARQ-PL-0001_07_V01	INDICADA	V01	07 DE 101

ARCHIVO:	FECHA:
L1T1-0000-313-CON-ED-ARQ-MO-0001_V00.rvt	DICIEMBRE 2021