L1T1-CON-CAL-FR-0120 - B1 : 1000x707mm

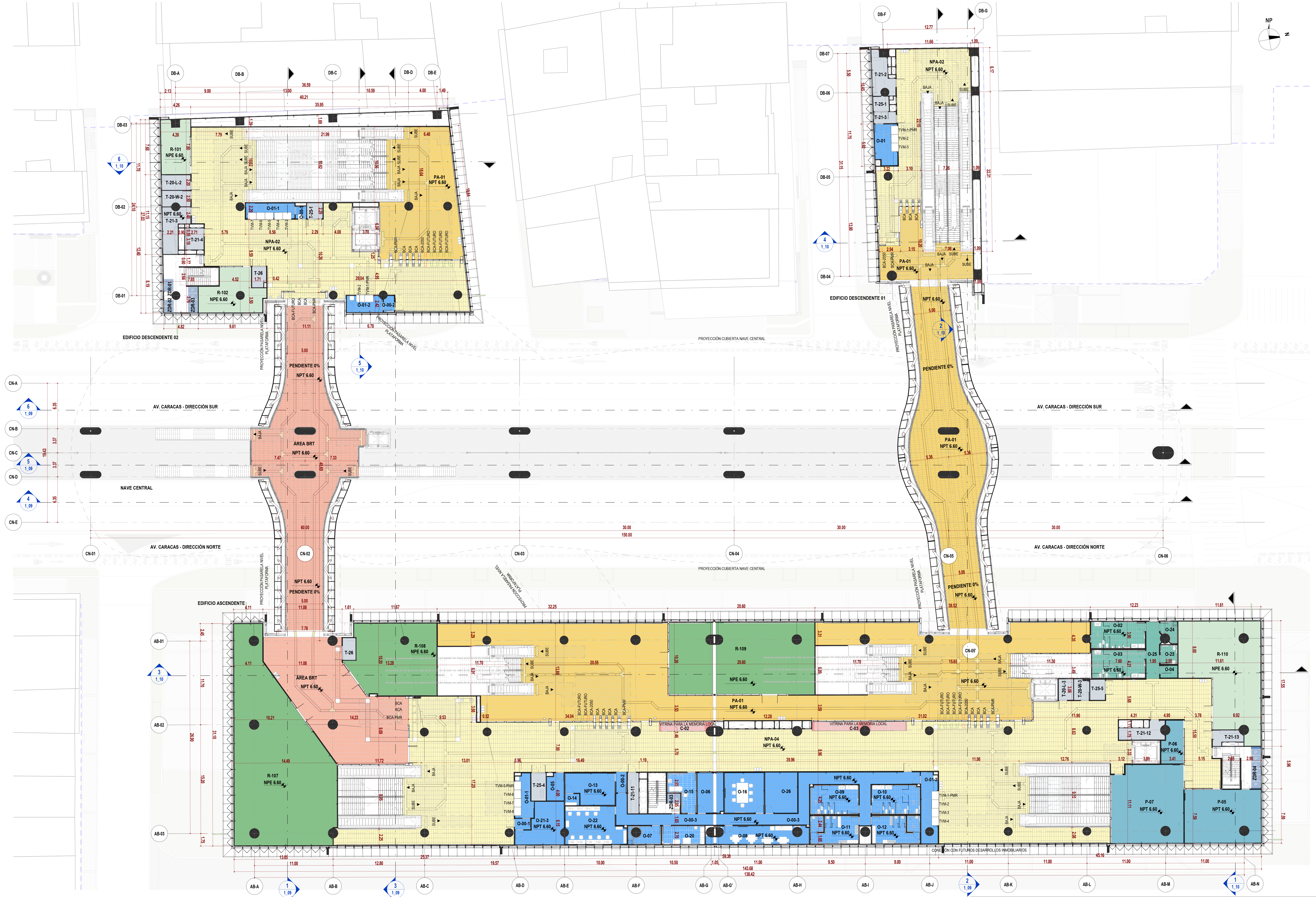

2 NIVEL INTERMEDIO_GENERAL

ESC: 1 : 200

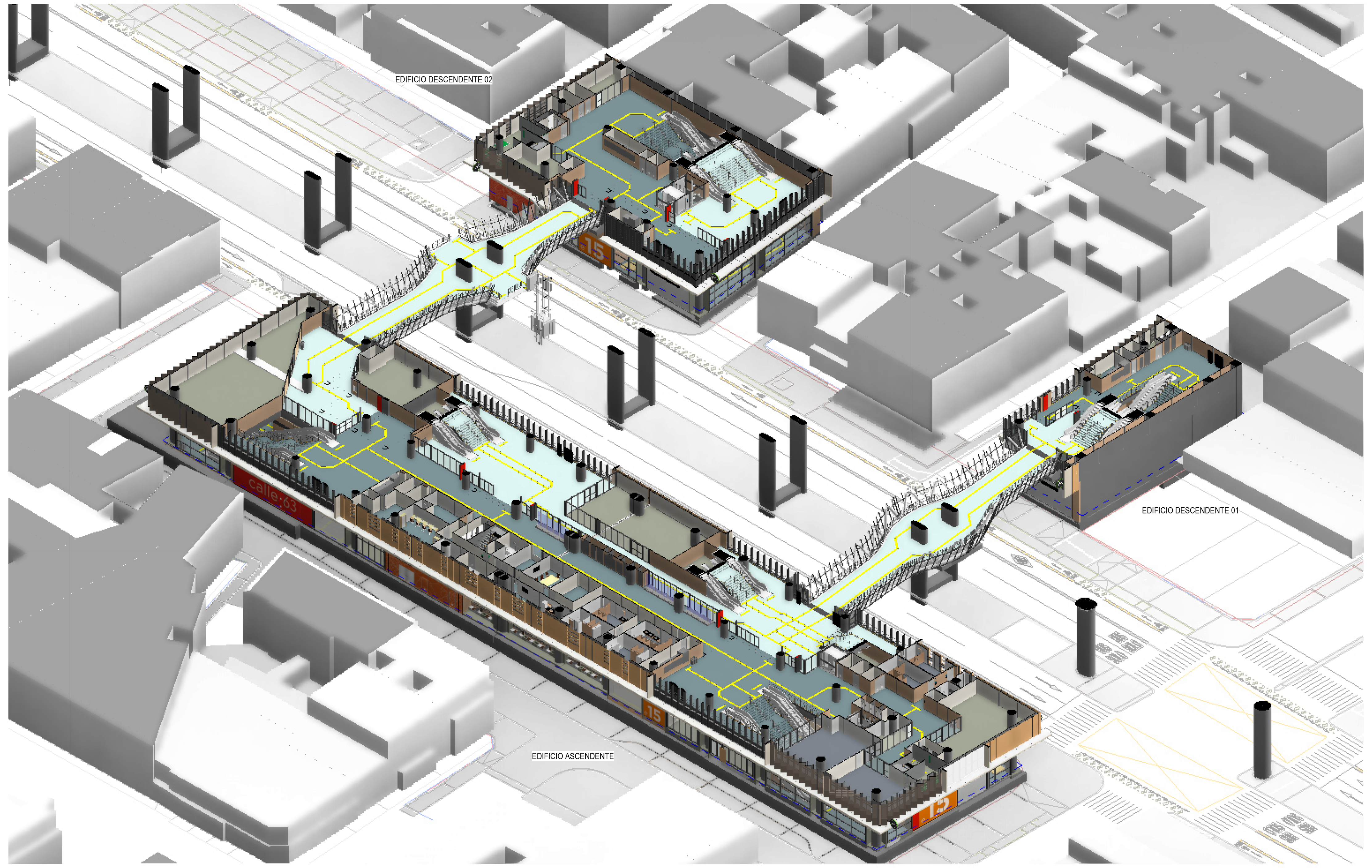

1 3D_NIVEL INTERMEDIO_GENERAL

ESC: N/A

LOCALIZACIÓN

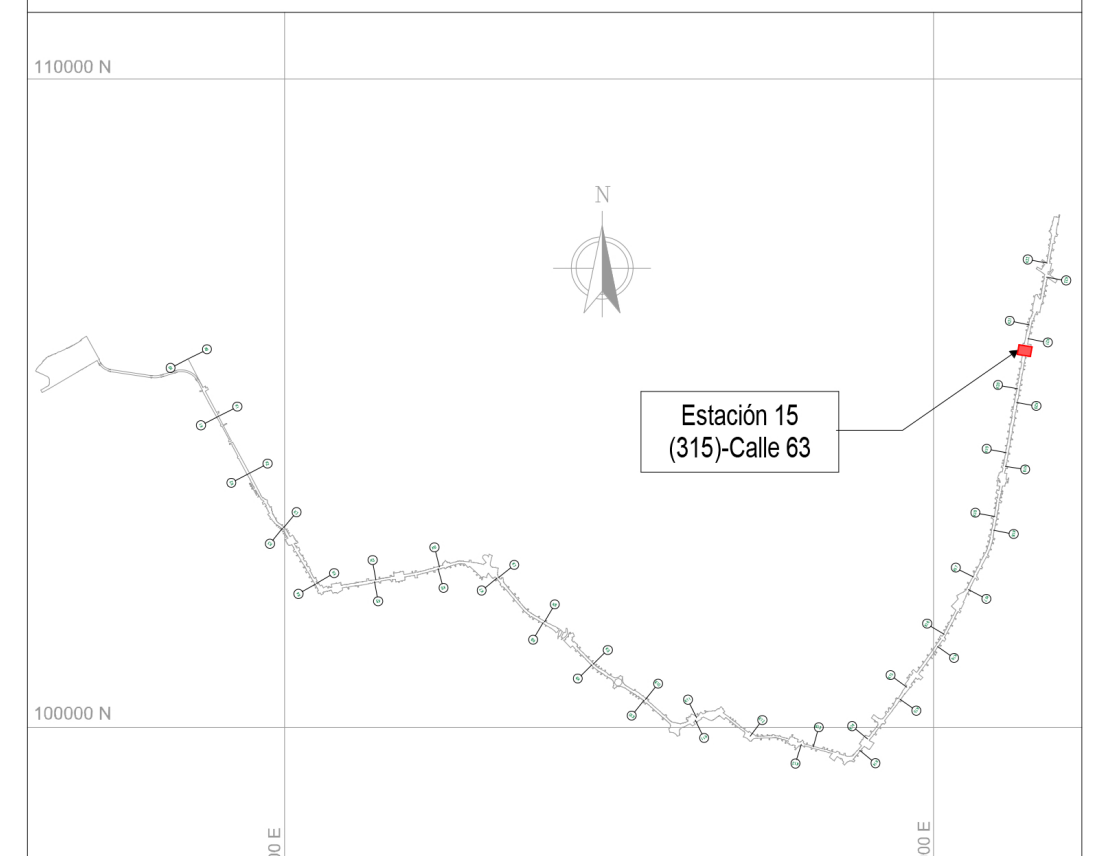

NOTAS

01 TODAS LAS DIMENSIONES ESTÁN CONFIGURADAS EN METROS A MENOS QUE SE INDIQUE UNA UNIDAD DE MEDIDA DIFERENTE.

02 TODAS LAS MEDIDAS, UBICACIÓN Y NIVELES DEBEN VERIFICARSE EN EL LUGAR DE CONSTRUCCIÓN.

03 EL NIVEL DE ACCESO AL EDIFICIO PL 01 CORRESPONDE AL +0,00 DE LA ESTACIÓN Y REFERENCIA AL NIVEL 2569.10 M.S.N.M.

04 LOS NOMBRES ESPECÍFICOS DE LAS ÁREAS PUEDEN SER CONSULTADAS EN EL PLANO NO. 3 Ó EN LAS VISTAS EN PLANTA.

05 LOS COLORES QUE SE MUESTRAN EN LOS PLANOS COMO PROYECCIÓN DE ELEMENTOS ARQUITECTÓNICOS COMO CUBIERTAS, FACHADAS, MUROS, ETC. NO REPRESENTAN LA MATERIALIDAD Y REALIDAD DE ACABADOS DEL PROYECTO, SOLO SON INDICATIVOS PARA REALIZAR UNA CORRECTA LECTURA DE LA PLANIMETRÍA.

06 LAS ESCALERAS ELÉCTRICAS INDICAN SU SENTIDO CON LA SIGUIENTE NOMENCLATURA: "SUBE" Y "BAJA".

07 SE DEBEN REVISAR LOS NIVELES ESTRUCTURALES PARA NIVEL DE ACCESO PL_01 Y SUBNIVELES, PL_02 (INTERMEDIO), PL_03 (PLATAFORMA) CON LA PLANIMETRÍA DE PLACAS ESTRUCTURALES EN LOS ENTREGABLES L1T1-1300-415-CON-ED-EST-PL-0040, 41, 126, 86 RESPECTIVAMENTE. EL NIVEL ESTRUCTURAL (NE) REFERENCIA LOS ESPACIOS DONDE SE DEBE ACONDICIONAR EL ACABADO DE PISO SEGÚN CORRESPONDA, CON LOS NIVELES DE PISO TERMINADO (NPT). LOS NIVELES PROYECTADOS DE EMPATE (NPE) EN LAS ÁREAS DE SERVICIOS ADICIONALES, REFERENCIAN LA ADECUACIÓN DE LOS DESNIVELES EN ESTAS ÁREAS; QUEDA COMO RESPONSABILIDAD DEL LOCATARIO DEFINIR Y ACONDICIONAR ESTE ACABADO DE PISO (NPE) EN LÍNEA CON EL NIVEL (NPT) DE ESPACIOS COLINDANTES. EL NIVEL ESTRUCTURAL (NE) SE ENCUENTRA A (- 0.10M) POR DEBAJO DE LOS NIVELES DE PISO TERMINADO (NPT) Y LOS NIVELES PROYECTADOS DE EMPATE (NPE) MARCADOS EN LA PLANIMETRÍA.

- ARQ_PL_-00.1 = SER 3	/ NPT -11.00m	- ARQ_PL_00.8 = ACCESO	/ NPT -0.45m
- ARQ_PL_00 = SÓTANO	/ NPT -7.15m	- ARQ_PL_00.9 = ACCESO	/ NPT -0.30m
- ARQ_PL_00.1 = ACCESO	/ NPT -2.60m	- ARQ_PL_01 = ACCESO	/ NPT 0.00m
- ARQ_PL_00.2 = ACCESO	/ NPT -1.85m	- ARQ_PL_01.1 = ACCESO	/ NPT 0.30m
- ARQ_PL_00.3 = ACCESO	/ NPT -1.50m	- ARQ_PL_02 = INTERMEDIO	/ NPT 6.60m
- ARQ_PL_00.4 = ACCESO	/ NPT -1.45m	- ARQ_PL_02.2 = TOPE DE RIEL (TOR)	/ NPT 14.20m
- ARQ_PL_00.5 = ACCESO	/ NPT -1.27m	- ARQ_PL_03 = PLATAFORMA	/ NPT 15.34m
- ARQ_PL_00.6 = ACCESO	/ NPT -1.00m	- ARQ_PL_03 = CUBIERTA EDIFICIOS ACCESO	/ NPT 21.94m
- ARQ_PL_00.7 = ACCESO	/ NPT -0.60m	- ARQ_PL_05 = CUBIERTA NAVE CENTRAL	/ NPT 24.60m

CONVENCIONES

LÍMITE DE INTERVENCIÓN

HUELLA APÉNDICE TÉCNICO

MURO DIVISORIO

PROYECCIÓN NIVEL SUPERIOR

🟩	SERVICIOS ADICIONALES - ÁREA NO PAGA	🟨	ÁREA NO PAGA
🟩	SERVICIOS ADICIONALES - ÁREA PAGA	🟦	ÁREA OPERATIVA
🟩	SERVICIO PÚBLICO	🟨	ÁREA PAGA
🟦	ZONA DE REFUGIO	🟦	ÁREA PÚBLICA
🟥	ÁREA CULTURAL	⬜	ÁREA TÉCNICA
		🟥	ÁREA BRT

TABLA DE ÁREAS ÚTILES (NIVEL INTERMEDIO)

CÓDIGO	NOMBRE	ÁREA (m²)	DEPARTAMENTO
EDIFICIO ASCENDENTE			
ARQ_PL_02_INTERMEDIO			
O-15	LOCAL PRIMEROS AUXILIOS	17.16	ÁREA OPERATIVA
O-16	SALA DE REUNIONES	30.78	ÁREA OPERATIVA
O-06	OFICINA DEL SUPERVISOR DE LA ESTACIÓN	23.27	ÁREA OPERATIVA
O-05	LOCAL DE INFORMACIÓN	8.90	ÁREA OPERATIVA
O-08	SALA DE DESCANSO PARA EMPLEADOS	31.38	ÁREA OPERATIVA
O-07	CUARTO DE LIMPIEZA	10.00	ÁREA OPERATIVA
O-01-2	VENTA AUTOMÁTICA DE BOLETOS	22.34	ÁREA OPERATIVA
O-01-1	VENTA AUTOMÁTICA DE BOLETOS	14.32	ÁREA OPERATIVA
P-05	BIBLIOMETRO	77.91	ÁREA PÚBLICA
O-00-3	CIRCULACIÓN ÁREAS OPERATIVAS	90.12	ÁREA OPERATIVA
O-12	VESTIDORES EMPLEADOS MUJERES	25.75	ÁREA OPERATIVA
O-11	VESTIDORES EMPLEADOS HOMBRES	25.75	ÁREA OPERATIVA
P-06	ESPACIO IPES (INSTITUTO PARA LA ECONOMÍA SOCIAL)	16.12	ÁREA PÚBLICA
NPA-04	ÁREA NO PAGA	1144.96	ÁREA NO PAGA
P-07	SALÓN MÚLTIPLE EMB	105.96	ÁREA PÚBLICA
O-20	SALA DE LACTANCIA	15.36	ÁREA OPERATIVA
T-21-11	ÁREA DE INSPECCIÓN	8.74	ÁREA TÉCNICA
O-22	OFICINA DE MANTENIMIENTO	40.57	ÁREA OPERATIVA
O-26	ALMACENAMIENTO DE BASURAS METRO	25.86	ÁREA OPERATIVA
T-21-12	ÁREA DE INSPECCIÓN	11.96	ÁREA TÉCNICA
ZDR-03	ZONA DE REFUGIO (PMR)	2.44	ZONA DE REFUGIO
O-09	BAÑOS EMPLEADOS HOMBRES	27.19	ÁREA OPERATIVA
O-10	BAÑOS EMPLEADOS MUJERES	27.19	ÁREA OPERATIVA
T-21-13	ÁREA DE INSPECCIÓN	7.30	ÁREA TÉCNICA
ZDR-04	ZONA DE REFUGIO (PMR)	7.87	ZONA DE REFUGIO
T-20-L-3	MEDIDORES (LUZ)	5.95	ÁREA TÉCNICA
T-20-W-3	MEDIDORES (AGUA)	6.00	ÁREA TÉCNICA
O-13	LOCAL DE POLICÍA	27.55	ÁREA OPERATIVA
R-108	SERVICIOS ADICIONALES - ÁREA DE SERVICIO	113.05	SERVICIOS ADICIONALES - ÁREA PAGA
R-110	SERVICIOS ADICIONALES - ÁREA DE SERVICIO	141.70	SERVICIOS ADICIONALES - ÁREA NO PAGA
O-21-3	ALMACENAMIENTO DE LA ESTACIÓN	31.88	ÁREA OPERATIVA
O-24	CUARTO DE LIMPIEZA DE BAÑOS PÚBLICOS	5.50	SERVICIO PÚBLICO
O-03	BAÑOS PÚBLICOS DE MUJERES	29.00	SERVICIO PÚBLICO
O-02	BAÑOS PÚBLICOS DE HOMBRES	27.92	SERVICIO PÚBLICO
C-02	ÁREAS DE USO CULTURAL	9.15	ÁREA CULTURAL
C-03	ÁREAS DE USO CULTURAL	16.35	ÁREA CULTURAL
O-23	BAÑO PÚBLICO - FAMILIAR	6.25	SERVICIO PÚBLICO
O-04	CONTROL DE ACCESO BAÑOS PÚBLICOS	4.15	SERVICIO PÚBLICO
R-109	SERVICIOS ADICIONALES - ÁREA DE SERVICIO	198.81	SERVICIOS ADICIONALES - ÁREA PAGA
T-25-4	NODO DE ACCESO DE TELECOMUNICACIONES	7.88	ÁREA TÉCNICA
T-25-5	NODO DE ACCESO DE TELECOMUNICACIONES	5.81	ÁREA TÉCNICA
T-26	NODO DE ACCESO DE TELECOMUNICACIONES TMSA	5.51	ÁREA TÉCNICA
O-25	BAÑO PÚBLICO - CORREDOR OPERACIONAL	15.09	SERVICIO PÚBLICO
O-00-2	CIRCULACIÓN ÁREAS OPERATIVAS	4.35	ÁREA OPERATIVA
R-107	SERVICIOS ADICIONALES - ÁREA DE SERVICIO	307.73	SERVICIOS ADICIONALES - ÁREA PAGA
ÁREA BRT	ÁREA BRT	214.01	ÁREA BRT
O-14	CALABOZO	3.19	ÁREA OPERATIVA
PA-01	ÁREA PAGA	722.99	ÁREA PAGA
O-00-1	CIRCULACIÓN ÁREAS OPERATIVAS	3.27	ÁREA OPERATIVA

TABLA DE ÁREAS ÚTILES (NIVEL INTERMEDIO)

CÓDIGO	NOMBRE	ÁREA (m²)	DEPARTAMENTO
EDIFICIO ASCENDENTE		3732.31	
EDIFICIO DESCENDENTE 01			
ARQ_PL_02_INTERMEDIO			
T-21-2	ÁREA DE INSPECCIÓN	14.32	ÁREA TÉCNICA
O-01	VENTA AUTOMÁTICA DE BOLETOS	17.63	ÁREA OPERATIVA
PA-01	ÁREA PAGA	78.28	ÁREA PAGA
T-21-3	ÁREA DE INSPECCIÓN	4.93	ÁREA TÉCNICA
NPA-02	ÁREA NO PAGA	152.22	ÁREA NO PAGA
T-25-1	NODO DE ACCESO DE TELECOMUNICACIONES	4.50	ÁREA TÉCNICA
EDIFICIO DESCENDENTE 01		271.88	
EDIFICIO DESCENDENTE 02			
ARQ_PL_02_INTERMEDIO			
O-01-1	VENTA AUTOMÁTICA DE BOLETOS	14.64	ÁREA OPERATIVA
NPA-02	ÁREA NO PAGA	410.10	ÁREA NO PAGA
PA-01	ÁREA PAGA	181.75	ÁREA PAGA
R-102	SERVICIOS ADICIONALES - ÁREA DE SERVICIO	43.46	SERVICIOS ADICIONALES - ÁREA NO PAGA
T-21-4	ÁREA DE INSPECCIÓN	7.84	ÁREA TÉCNICA
R-101	SERVICIOS ADICIONALES - ÁREA DE SERVICIO	29.69	SERVICIOS ADICIONALES - ÁREA NO PAGA
ZDR-03	ZONA DE REFUGIO (PMR)	4.87	ZONA DE REFUGIO
T-21-3	ÁREA DE INSPECCIÓN	17.51	ÁREA TÉCNICA
T-20-L-2	MEDIDORES (LUZ)	8.39	ÁREA TÉCNICA
T-20-W-2	MEDIDORES (AGUA)	9.35	ÁREA TÉCNICA
ZDR-02	ZONA DE REFUGIO (PMR)	2.45	ZONA DE REFUGIO
ZDR-01	ZONA DE REFUGIO (PMR)	2.46	ZONA DE REFUGIO
T-25-1	NODO DE ACCESO DE TELECOMUNICACIONES	4.63	ÁREA TÉCNICA
T-26	NODO DE ACCESO DE TELECOMUNICACIONES TMSA	5.44	ÁREA TÉCNICA
O-01-2	VENTA AUTOMÁTICA DE BOLETOS	11.35	ÁREA OPERATIVA
O-00-1	CIRCULACIÓN ÁREAS OPERATIVAS	2.55	ÁREA OPERATIVA
O-00-2	CIRCULACIÓN ÁREAS OPERATIVAS	3.21	ÁREA OPERATIVA
EDIFICIO DESCENDENTE 02		759.70	
NAVE CENTRAL			
ARQ_PL_02_INTERMEDIO			
ÁREA BRT	ÁREA BRT	326.51	ÁREA BRT
PA-01	ÁREA PAGA	304.71	ÁREA PAGA
NAVE CENTRAL		631.21	
TOTAL NIVEL INTERMEDIO		5395.10	

TABLA DE ÁREAS ÚTILES POR DEPARTAMENTO (NIVEL INTERMEDIO)

DEPARTAMENTO	ÁREA (m²)
EDIFICIO ASCENDENTE	
ARQ_PL_02_INTERMEDIO	
	18.05
SERVICIO PÚBLICO	87.91
SERVICIOS ADICIONALES - ÁREA NO PAGA	141.70
SERVICIOS ADICIONALES - ÁREA PAGA	619.60
ZONA DE REFUGIO	10.31
ÁREA BRT	214.01
ÁREA CULTURAL	25.50
ÁREA NO PAGA	1144.96
ÁREA OPERATIVA	506.18
ÁREA PAGA	722.99
ÁREA PÚBLICA	199.99
ÁREA TÉCNICA	59.14
EDIFICIO DESCENDENTE 01	
ARQ_PL_02_INTERMEDIO	
	0.00
ÁREA NO PAGA	152.22
ÁREA OPERATIVA	17.63
ÁREA PAGA	78.28
ÁREA TÉCNICA	23.75
EDIFICIO DESCENDENTE 02	
ARQ_PL_02_INTERMEDIO	
	0.00
SERVICIOS ADICIONALES - ÁREA NO PAGA	73.14
ZONA DE REFUGIO	9.79
ÁREA NO PAGA	410.10
ÁREA OPERATIVA	31.75
ÁREA PAGA	181.75
ÁREA TÉCNICA	53.17
NAVE CENTRAL	
ARQ_PL_02_INTERMEDIO	
	304.94
ÁREA BRT	326.51
ÁREA PAGA	304.71
TOTAL NIVEL INTERMEDIO	5718.10

PLANO CLAVE ESTACIÓN 15

VÁLIDO PARA CONSTRUCCIÓN

31-03-26

No.	PLANOS DE REFERENCIA	REV.

No.	MODELO BIM DE REFERENCIA	REV.
1	L1T1-1100-215-CON-ED-EST-MO-0001.rvt	V00
2	L1T1-1100-216-CON-ED-EST-MO-0001.rvt	V00
3	L1T1-1100-315-CON-ED-EST-MO-0001.rvt	V00
4	L1T1-1150-215-CON-ED-EST-MO-0001.rvt	V00
5	L1T1-1150-216-CON-ED-EST-MO-0001.rvt	V00
6	L1T1-1150-315-CON-ED-EST-MO-0001.rvt	V00
7	L1T1-1200-315-CON-ED-EST-MO-0001.rvt	V00
8	L1T1-1300-415-CON-ED-EST-MO-0001.rvt	V00
9	L1T1-1300-415-CON-ED-EST-MO-0002.rvt	V00
10	L1T1-1300-415-CON-ED-EST-MO-0003.rvt	V00
11	L1T1-1310-415-CON-ED-EST-MO-0001.rvt	V00
12	L1T1-1410-315-CON-ED-MEC-MO-0001.rvt	V00
13	L1T1-1420-315-CON-ED-MEC-MO-0001.rvt	V00
14	L1T1-2320-590-CON-ED-EST-MO-0001.rvt	V00
15	L1T1-2320-590-CON-ED-EST-MO-0002.rvt	V00
16	L1T1-2330-590-CON-ED-ARQ-MO-0001.rvt	V00
17	L1T1-5110-315-CON-ED-EST-MO-0001.rvt	V00
18	L1T1-5160-315-CON-ED-EST-MO-0001.rvt	V00
19	L1T1-5160-315-CON-ED-ARQ-MO-0001.rvt	V00
20	L1T1-5300-315-CON-ED-MEC-MO-0001.rvt	V00
21	L1T1-5600-315-CON-ED-INS-MO-0001.rvt	V00
22	L1T1-1330-415-CON-ED-ARQ-MO-0011.rvt	V00
23	L1T1-1330-415-CON-ED-ARQ-MO-0012.rvt	V00
24	L1T1-1330-415-CON-ED-ARQ-MO-0013.rvt	V00

No.	PAQUETE DE TRABAJO DE REFERENCIA	REV.
1	XREF-URBANISM_CONTEXT_ST15.rvt	
2	XREF-SECONDARY-STRUCTURE-ST15.rvt	

0 2 10m

1:200

DISEÑO:

REN ZHENHUA
Licencia de Arq.nivel I (China): 1101735-614

APROBÓ:

DIEGO ERNESTO DUEÑAS
Mat.: 25202-53876 CND

REVISÓ:

CARLOS MAURICIO BARRETO BARBOSA
Mat.: A4012012-14139353

DIBUJÓ:

EQUIPO CHEC

REVISIÓN No.	FECHA	DESCRIPCIÓN	REVISÓ	APROBÓ	APROBACIÓN CLIENTE
V01	31/03/2026	EMITIDO PARA CONSTRUCCIÓN	C.M.B.B	D.E.D	
V00	13/12/2024	REVISIÓN NO OBJETADA - EMITIDO PARA CONSTRUCCIÓN	F.B.R	E.O.M	
VFF	21/08/2024	EMITIDO PARA REVISIÓN Y COMENTARIOS DEL CLIENTE E INTERVENTORÍA - INCLUYE COMENTARIOS /(AJUSTES V3)	F.B.R	E.O.M	
VEE	02/05/2024	EMITIDO PARA REVISIÓN Y COMENTARIOS DEL CLIENTE E INTERVENTORÍA - INCLUYE COMENTARIOS /(AJUSTES V2)	F.B.R	E.O.M	
VDD	18/12/2022	EMITIDO PARA REVISIÓN Y COMENTARIOS DEL CLIENTE E INTERVENTORÍA - INCLUYE COMENTARIOS /(AJUSTES)	J.E.M	M.B.M	
VCC	02/06/2022	EMITIDO PARA REVISIÓN Y COMENTARIOS DEL CLIENTE E INTERVENTORÍA - INCLUYE COMENTARIOS /(ENTREGA 90%)	J.E.M	M.B.M	
VBB	06/12/2021	EMITIDO PARA REVISIÓN Y COMENTARIOS DEL CLIENTE E INTERVENTORÍA	J.E.M	M.B.M	
VA0	30/06/2021	EMITIDO PARA COMENTARIOS INTERNOS - EMISIÓN PRELIMINAR PARA COMENTARIOS	J.E.M	M.B.M	

METRO LÍNEA 1

DIRECTOR DE INTERVENTORÍA:
JAVIER DESCARGA N.
Mat.:25202-68697 CND

METRO LÍNEA 1
CONTRATO DE CONCESIÓN No. 163 DE 2019

PROYECTO PRIMERA LÍNEA DEL METRO DE BOGOTÁ - TRAMO 1

ESPECIALISTA INTERVENTORÍA:
CARLOS ALBERTO HOYOS SOTO
Mat.:A25072000-14251682

FECHA:
MARZO 2026

INFRAESTRUCTURA VIAL

ARQUITECTURA

ESTACIÓN METRO 15 - (CALLE 63)
GENERAL
VISTA EN PLANTA Y 3D - NIVEL INTERMEDIO

PLANCHA No:	L1T1-0000-315-CON-ED-ARQ-PL-0001_06_V01	ESCALA: INDICADA	REVISIÓN No.	PLANO No.
ARCHIVO:	L1T1-0000-315-CON-ED-ARQ-MO-0001_V00.rvt	FECHA: JUNIO 2021	V01	06 DE 94