L1T1-CON-CAL-FR-0120 - B1 : 1000x707mm

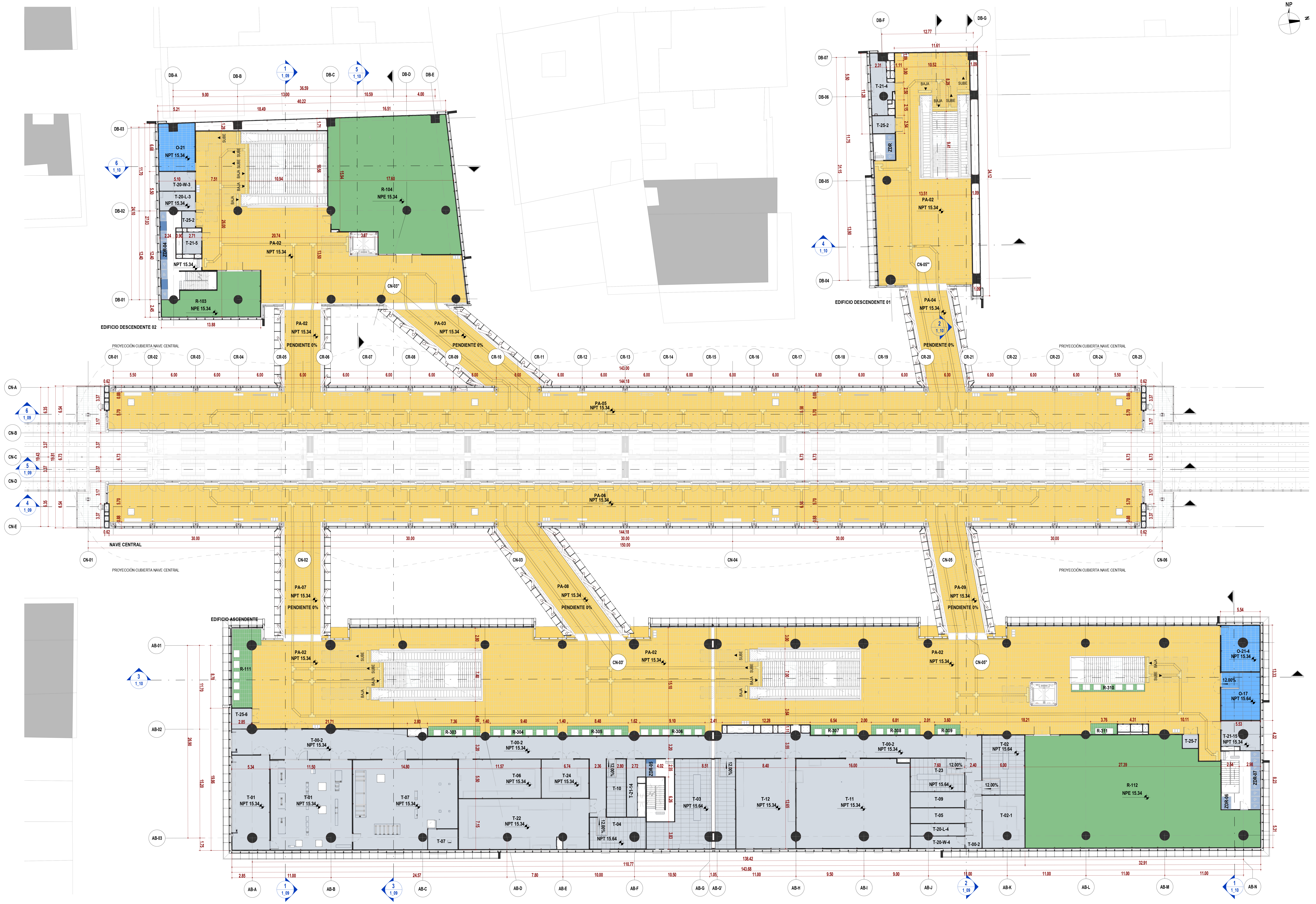

2 NIVEL PLATAFORMA_GENERAL
ESC: 1 : 200

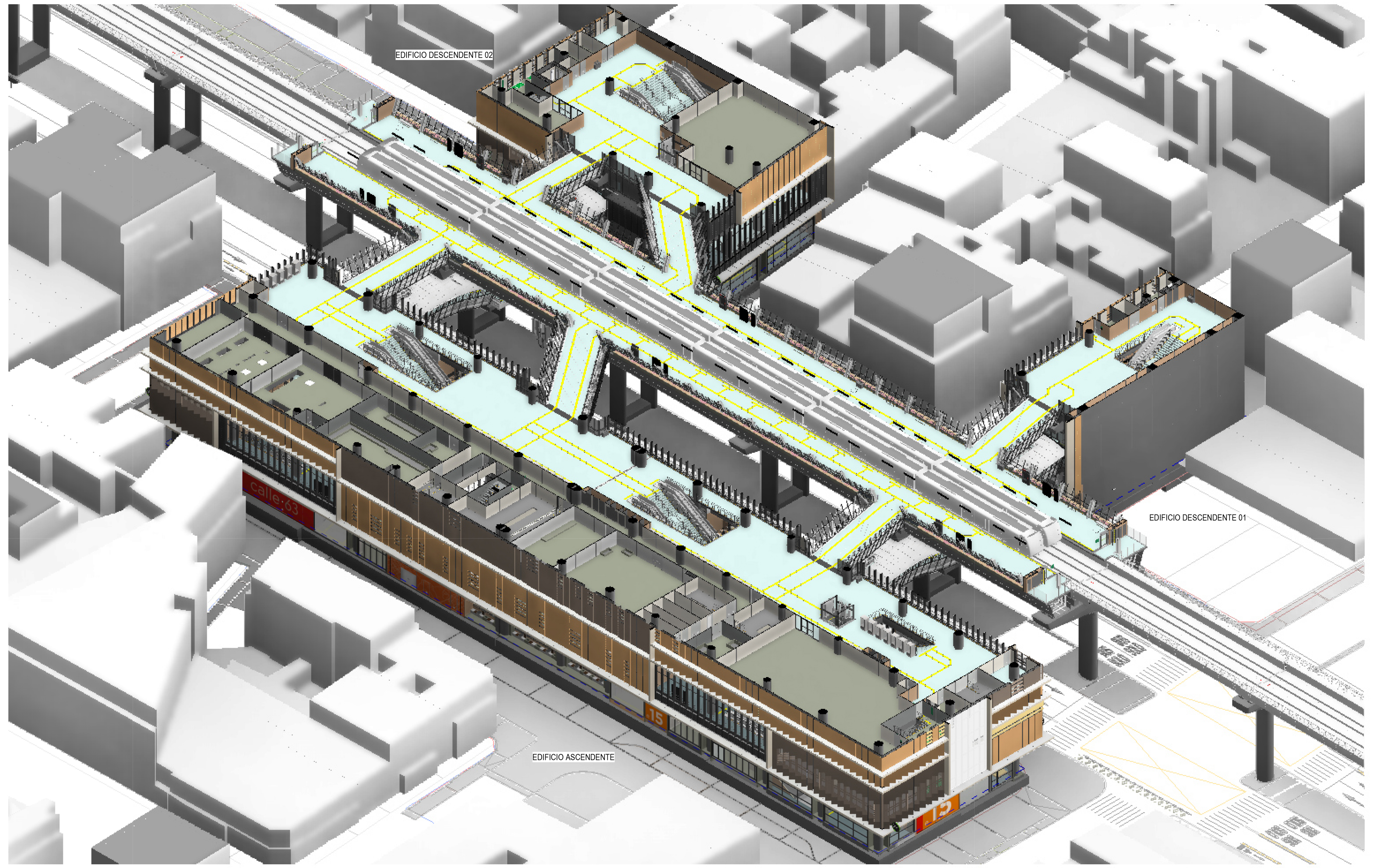

1 3D_NIVEL PLATAFORMA_GENERAL
ESC: N/A

LOCALIZACIÓN

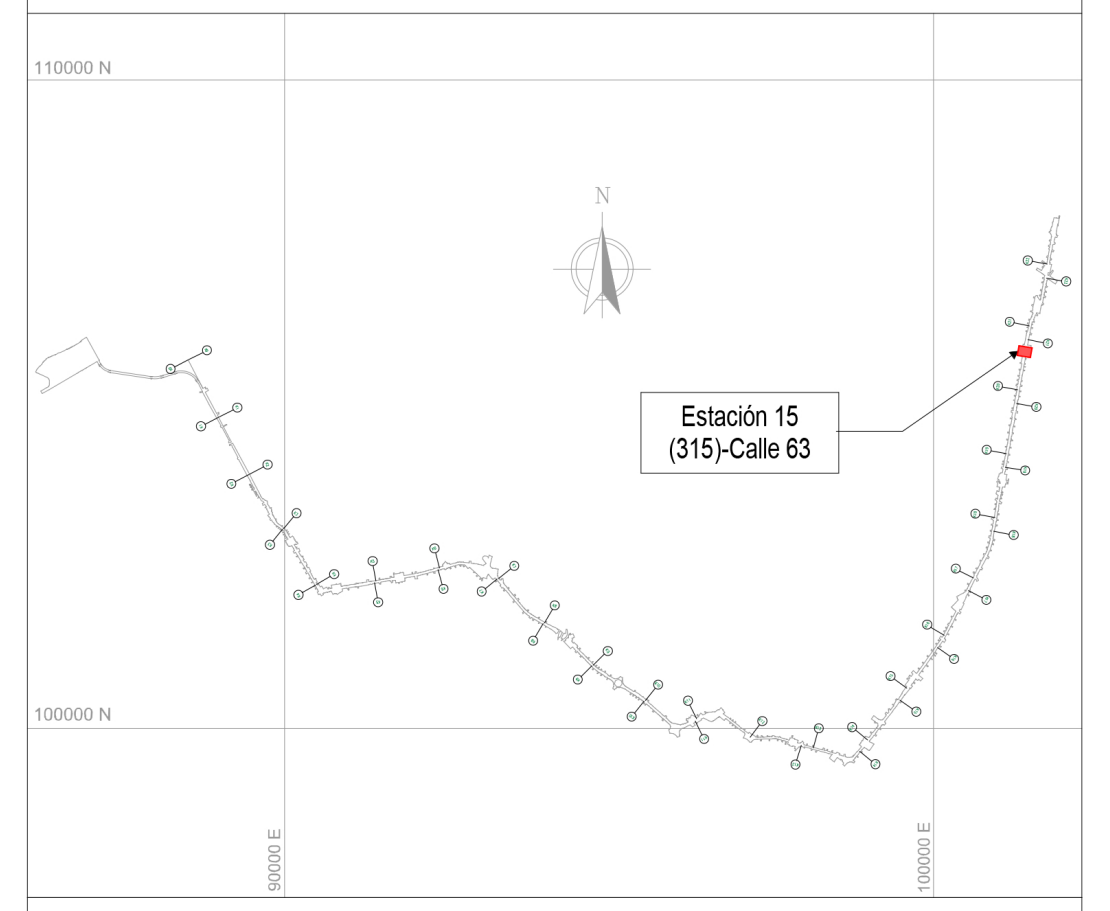

NOTAS

01 TODAS LAS DIMENSIONES ESTÁN CONFIGURADAS EN METROS A MENOS QUE SE INDIQUE UNA UNIDAD DE MEDIDA DIFERENTE.

02 TODAS LAS MEDIDAS, UBICACIÓN Y NIVELES DEBEN VERIFICARSE EN EL LUGAR DE CONSTRUCCIÓN.

03 EL NIVEL DE ACCESO AL EDIFICIO PL 01 CORRESPONDE AL +0,00 DE LA ESTACIÓN Y REFERENCIA AL NIVEL 2569.10 M.S.N.M.

04 LOS NOMBRES ESPECÍFICOS DE LAS ÁREAS PUEDEN SER CONSULTADAS EN EL PLANO NO. 3 Ó EN LAS VISTAS EN PLANTA.

05 LOS COLORES QUE SE MUESTRAN EN LOS PLANOS COMO PROYECCIÓN DE ELEMENTOS ARQUITECTÓNICOS COMO CUBIERTAS, FACHADAS, MUROS, ETC. NO REPRESENTAN LA MATERIALIDAD Y REALIDAD DE ACABADOS DEL PROYECTO, SOLO SON INDICATIVOS PARA REALIZAR UNA CORRECTA LECTURA DE LA PLANIMETRÍA.

06 LAS ESCALERAS ELÉCTRICAS INDICAN SU SENTIDO CON LA SIGUIENTE NOMENCLATURA: "SUBE" Y "BAJA".

07 SE DEBEN REVISAR LOS NIVELES ESTRUCTURALES PARA NIVEL DE ACCESO PL_01 Y SUBNIVELES, PL_02 (INTERMEDIO), PL_03 (PLATAFORMA) CON LA PLANIMETRÍA DE PLACAS ESTRUCTURALES EN LOS ENTREGABLES L1T1-1300-415-CON-ED-EST-PL-0040, 41, 126, 86 RESPECTIVAMENTE. EL NIVEL ESTRUCTURAL (NE) REFERENCIA LOS ESPACIOS DONDE SE DEBE ACONDICIONAR EL ACABADO DE PISO SEGÚN CORRESPONDA, CON LOS NIVELES DE PISO TERMINADO (NPT). LOS NIVELES PROYECTADOS DE EMPATE (NPE) EN LAS ÁREAS DE SERVICIOS ADICIONALES, REFERENCIAN LA ADECUACIÓN DE LOS DESNIVELES EN ESTAS ÁREAS; QUEDA COMO RESPONSABILIDAD DEL LOCATARIO DEFINIR Y ACONDICIONAR ESTE ACABADO DE PISO (NPE) EN LÍNEA CON EL NIVEL (NPT) DE ESPACIOS COLINDANTES. EL NIVEL ESTRUCTURAL (NE) SE ENCUENTRA A (- 0.10M) POR DEBAJO DE LOS NIVELES DE PISO TERMINADO (NPT) Y LOS NIVELES PROYECTADOS DE EMPATE (NPE) MARCADOS EN LA PLANIMETRÍA.

- ARQ_PL_-00.1 = SER 3 / NPT -11.00m
- ARQ_PL_00 = SÓTANO / NPT -7.15m
- ARQ_PL_00.1 = ACCESO / NPT -2.60m
- ARQ_PL_00.2 = ACCESO / NPT -1.85m
- ARQ_PL_00.3 = ACCESO / NPT -1.50m
- ARQ_PL_00.4 = ACCESO / NPT -1.45m
- ARQ_PL_00.5 = ACCESO / NPT -1.27m
- ARQ_PL_00.6 = ACCESO / NPT -1.00m
- ARQ_PL_00.7 = ACCESO / NPT -0.60m
- ARQ_PL_00.8 = ACCESO / NPT -0.45m
- ARQ_PL_00.9 = ACCESO / NPT -0.30m
- ARQ_PL_01 = ACCESO / NPT 0.00m
- ARQ_PL_01.1 = ACCESO / NPT 0.30m
- ARQ_PL_02 = INTERMEDIO / NPT 6.60m
- ARQ_PL_02.2 = TOPE DE RIEL (TOR) / NPT 14.20m
- ARQ_PL_03 = PLATAFORMA / NPT 15.34m
- ARQ_PL_03 = CUBIERTA EDIFICIOS ACCESO / NPT 21.94m
- ARQ_PL_05 = CUBIERTA NAVE CENTRAL / NPT 24.60m

CONVENCIONES

- ‒ ‒ ‒ LÍMITE DE INTERVENCIÓN
- ‒ ‒ ‒ HUELLA APÉNDICE TÉCNICO
- ▬ MURO DIVISORIO
- — — — PROYECCIÓN NIVEL SUPERIOR

- 🟩 SERVICIOS ADICIONALES - ÁREA NO PAGA
- 🟩 SERVICIOS ADICIONALES - ÁREA PAGA
- 🟩 SERVICIO PÚBLICO
- 🟦 ZONA DE REFUGIO
- 🟥 ÁREA CULTURAL
- 🟨 ÁREA NO PAGA
- 🟦 ÁREA OPERATIVA
- 🟨 ÁREA PAGA
- 🟦 ÁREA PÚBLICA
- ⬜ ÁREA TÉCNICA
- 🟧 ÁREA BRT

TABLA DE ÁREAS ÚTILES (NIVEL PLATAFORMA)

CÓDIGO	NOMBRE	ÁREA (m²)	DEPARTAMENTO
EDIFICIO ASCENDENTE			
ARQ_PL_03_PLATAFORMA			
O-17	OPERADORES TELECOMUNICACIONES EXTERIORES	35.33	ÁREA OPERATIVA
O-21-4	ALMACENAMIENTO DE LA ESTACIÓN	33.26	ÁREA OPERATIVA
PA-02	ÁREA PAGA	1601.00	ÁREA PAGA
R-111	SERVICIOS ADICIONALES - ÁREA DE SERVICIO	35.13	SERVICIOS ADICIONALES - ÁREA PAGA
R-112	SERVICIOS ADICIONALES - ÁREA DE SERVICIO	435.62	SERVICIOS ADICIONALES - ÁREA PAGA
R-303	SERVICIOS ADICIONALES - MÁQUINAS EXPENDEDORAS/CAJEROS AUTOMÁTICOS	9.75	SERVICIOS ADICIONALES - ÁREA PAGA
R-304	SERVICIOS ADICIONALES - MÁQUINAS EXPENDEDORAS/CAJEROS AUTOMÁTICOS	12.69	SERVICIOS ADICIONALES - ÁREA PAGA
R-305	SERVICIOS ADICIONALES - MÁQUINAS EXPENDEDORAS/CAJEROS AUTOMÁTICOS	11.44	SERVICIOS ADICIONALES - ÁREA PAGA
R-306	SERVICIOS ADICIONALES - MÁQUINAS EXPENDEDORAS/CAJEROS AUTOMÁTICOS	12.27	SERVICIOS ADICIONALES - ÁREA PAGA
R-307	SERVICIOS ADICIONALES - MÁQUINAS EXPENDEDORAS/CAJEROS AUTOMÁTICOS	9.08	SERVICIOS ADICIONALES - ÁREA PAGA
R-308	SERVICIOS ADICIONALES - MÁQUINAS EXPENDEDORAS/CAJEROS AUTOMÁTICOS	9.54	SERVICIOS ADICIONALES - ÁREA PAGA
R-309	SERVICIOS ADICIONALES - MÁQUINAS EXPENDEDORAS/CAJEROS AUTOMÁTICOS	5.04	SERVICIOS ADICIONALES - ÁREA PAGA
R-310	SERVICIOS ADICIONALES - MÁQUINAS EXPENDEDORAS/CAJEROS AUTOMÁTICOS	13.36	SERVICIOS ADICIONALES - ÁREA PAGA
R-311	SERVICIOS ADICIONALES - MÁQUINAS EXPENDEDORAS/CAJEROS AUTOMÁTICOS	5.58	SERVICIOS ADICIONALES - ÁREA PAGA
T-00-2	CIRCULACIÓN TÉCNICA	389.69	ÁREA TÉCNICA
T-01	SUBESTACIÓN DE TRACCIÓN (SET)	209.33	ÁREA TÉCNICA
T-02	LOCAL DE CONDUCCIÓN AUTOMÁTICA (CBTC)	48.36	ÁREA TÉCNICA
T-02-1	UPS DEDICADA (CBTC)	41.81	ÁREA TÉCNICA
T-03	TELECOMUNICACIONES ESTACIÓN - CORRIENTE DÉBIL	117.23	ÁREA TÉCNICA
T-04	EQUIPO BOLETERÍA	32.27	ÁREA TÉCNICA
T-05	ALMACÉN PARA MANTENIMIENTO	15.65	ÁREA TÉCNICA
T-06	SALA DE TABLEROS	61.46	ÁREA TÉCNICA
T-07	CENTRO DE TRANSFORMACIÓN (CT)	181.40	ÁREA TÉCNICA
T-09	ALMACÉN EQUIPO ELÉCTRICO	16.03	ÁREA TÉCNICA
T-10	CUARTO DE EQUIPO ELECTROMECÁNICO	21.57	ÁREA TÉCNICA
T-11	CUARTO DE VENTILACIÓN	193.57	ÁREA TÉCNICA
T-12	PLANTA DE REFRIGERACIÓN PARA LA CLIMATIZACIÓN	102.09	ÁREA TÉCNICA
T-20-L-4	MEDIDORES (LUZ)	11.78	ÁREA TÉCNICA
T-20-W-4	MEDIDORES (AGUA)	11.75	ÁREA TÉCNICA
T-21-14	ÁREA DE INSPECCIÓN	14.42	ÁREA TÉCNICA
T-21-15	ÁREA DE INSPECCIÓN	19.08	ÁREA TÉCNICA
T-22	CUARTO DE UPS	123.68	ÁREA TÉCNICA
T-23	CUARTO PDAP	34.44	ÁREA TÉCNICA
T-24	TETRA UPS	35.28	ÁREA TÉCNICA
T-25-6	NODO DE ACCESO DE TELECOMUNICACIONES	7.28	ÁREA TÉCNICA
T-25-7	NODO DE ACCESO DE TELECOMUNICACIONES	3.88	ÁREA TÉCNICA
ZDR-05	ZONA DE REFUGIO (PMR)	3.27	ZONA DE REFUGIO
ZDR-06	ZONA DE REFUGIO (PMR)	2.43	ZONA DE REFUGIO
ZDR-07	ZONA DE REFUGIO (PMR)	10.94	ZONA DE REFUGIO
EDIFICIO ASCENDENTE		3937.80	

TABLA DE ÁREAS ÚTILES (NIVEL PLATAFORMA)

CÓDIGO	NOMBRE	ÁREA (m²)	DEPARTAMENTO
EDIFICIO DESCENDENTE 01			
ARQ_PL_03_PLATAFORMA			
PA-02	ÁREA PAGA	313.78	ÁREA PAGA
T-21-4	ÁREA DE INSPECCIÓN	18.63	ÁREA TÉCNICA
T-25-2	NODO DE ACCESO DE TELECOMUNICACIONES	7.51	ÁREA TÉCNICA
ZDR	ZONA DE REFUGIO (PMR)	4.86	ZONA DE REFUGIO
EDIFICIO DESCENDENTE 01		344.79	
EDIFICIO DESCENDENTE 02			
ARQ_PL_03_PLATAFORMA			
O-21	ALMACENAMIENTO DE LA ESTACIÓN	32.31	ÁREA OPERATIVA
PA-02	ÁREA PAGA	411.92	ÁREA PAGA
R-103	SERVICIOS ADICIONALES - ÁREA DE SERVICIO	60.99	SERVICIOS ADICIONALES - ÁREA PAGA
R-104	SERVICIOS ADICIONALES - ÁREA DE SERVICIO	306.74	SERVICIOS ADICIONALES - ÁREA PAGA
T-20-L-3	MEDIDORES (LUZ)	12.52	ÁREA TÉCNICA
T-20-W-3	MEDIDORES (AGUA)	13.15	ÁREA TÉCNICA
T-21-5	ÁREA DE INSPECCIÓN	7.71	ÁREA TÉCNICA
T-25-2	NODO DE ACCESO DE TELECOMUNICACIONES	4.17	ÁREA TÉCNICA
ZDR-04	ZONA DE REFUGIO (PMR)	11.04	ZONA DE REFUGIO
EDIFICIO DESCENDENTE 02		860.57	
NAVE CENTRAL			
ARQ_PL_03_PLATAFORMA			
PA-02	ÁREA PAGA	59.27	ÁREA PAGA
PA-03	ÁREA PAGA	92.32	ÁREA PAGA
PA-04	ÁREA PAGA	74.08	ÁREA PAGA
PA-05	ÁREA PAGA	766.87	ÁREA PAGA
PA-06	ÁREA PAGA	766.86	ÁREA PAGA
PA-07	ÁREA PAGA	79.88	ÁREA PAGA
PA-08	ÁREA PAGA	97.68	ÁREA PAGA
PA-09	ÁREA PAGA	80.67	ÁREA PAGA
NAVE CENTRAL		2017.63	
TOTAL NIVEL PLATAFORMA		7160.79	

TABLA DE ÁREAS ÚTILES POR DEPARTAMENTO (NIVEL PLATAFORMA)

DEPARTAMENTO	ÁREA (m²)
EDIFICIO ASCENDENTE	
ARQ_PL_03_PLATAFORMA	
	34.94
SERVICIOS ADICIONALES - ÁREA PAGA	559.50
ZONA DE REFUGIO	16.64
ÁREA OPERATIVA	68.59
ÁREA PAGA	1601.00
ÁREA TÉCNICA	1692.07
EDIFICIO DESCENDENTE 01	
ARQ_PL_03_PLATAFORMA	
	0.00
ZONA DE REFUGIO	4.86
ÁREA PAGA	313.78
ÁREA TÉCNICA	26.14
EDIFICIO DESCENDENTE 02	
ARQ_PL_03_PLATAFORMA	
	0.00
SERVICIOS ADICIONALES - ÁREA PAGA	367.74
ZONA DE REFUGIO	11.04
ÁREA OPERATIVA	32.31
ÁREA PAGA	411.92
ÁREA TÉCNICA	37.55
NAVE CENTRAL	
ARQ_PL_03_PLATAFORMA	
	484.72
ÁREA PAGA	2017.63
TOTAL NIVEL PLATAFORMA	7680.44

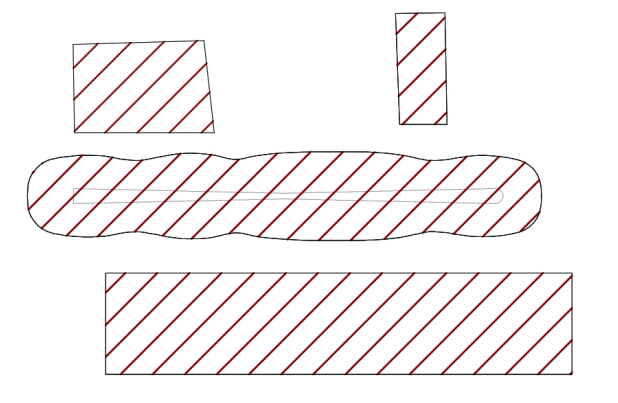

PLANO CLAVE ESTACIÓN 15

VÁLIDO PARA CONSTRUCCIÓN
31-03-26

No.	PLANOS DE REFERENCIA	REV.

No.	MODELO BIM DE REFERENCIA	REV.
1	L1T1-1100-215-CON-ED-EST-MO-0001.rvt	V00
2	L1T1-1100-216-CON-ED-EST-MO-0001.rvt	V00
3	L1T1-1100-315-CON-ED-EST-MO-0001.rvt	V00
4	L1T1-1150-215-CON-ED-EST-MO-0001.rvt	V00
5	L1T1-1150-216-CON-ED-EST-MO-0001.rvt	V00
6	L1T1-1150-315-CON-ED-EST-MO-0001.rvt	V00
7	L1T1-1200-315-CON-ED-EST-MO-0001.rvt	V00
8	L1T1-1300-415-CON-ED-EST-MO-0001.rvt	V00
9	L1T1-1300-415-CON-ED-EST-MO-0002.rvt	V00
10	L1T1-1300-415-CON-ED-EST-MO-0003.rvt	V00
11	L1T1-1310-415-CON-ED-EST-MO-0001.rvt	V00
12	L1T1-1410-315-CON-ED-MEC-MO-0001.rvt	V00
13	L1T1-1420-315-CON-ED-MEC-MO-0001.rvt	V00
14	L1T1-2320-590-CON-ED-EST-MO-0001.rvt	V00
15	L1T1-2320-590-CON-ED-EST-MO-0002.rvt	V00
16	L1T1-2330-590-CON-ED-ARQ-MO-0001.rvt	V00
17	L1T1-5110-315-CON-ED-EST-MO-0001.rvt	V00
18	L1T1-5160-315-CON-ED-EST-MO-0001.rvt	V00
19	L1T1-5160-315-CON-ED-ARQ-MO-0001.rvt	V00
20	L1T1-5300-315-CON-ED-MEC-MO-0001.rvt	V00
21	L1T1-5600-315-CON-ED-INS-MO-0001.rvt	V00
22	L1T1-1330-415-CON-ED-ARQ-MO-0011.rvt	V00
23	L1T1-1330-415-CON-ED-ARQ-MO-0012.rvt	V00
24	L1T1-1330-415-CON-ED-ARQ-MO-0013.rvt	V00

No.	PAQUETE DE TRABAJO DE REFERENCIA	REV.
1	XREF-URBANISM_CONTEXT_ST15.rvt	
2	XREF-SECONDARY-STRUCTURE-ST15.rvt	

0 2 10m
1:200

METRO BOGOTÁ
GCS Consorcio Consultores PMO Bogotá
CONSORCIO SUPERVISOR PLMB
CHEC

DISEÑÓ:
REN ZHENHUA
Licencia de Arq.nivel I (China): 1101735-614

APROBÓ:
DIEGO ERNESTO DUEÑAS
Mat.: 25202-53876 CND

REVISÓ:
CARLOS MAURICIO BARRETO BARBOSA
Mat.: A4012012-14139353

DIBUJÓ:
EQUIPO CHEC

REVISIÓN No.	FECHA	DESCRIPCIÓN	REVISÓ	APROBÓ	APROBACIÓN CLIENTE
V01	31/03/2026	EMITIDO PARA CONSTRUCCIÓN	C.M.B.B	D.E.D	
V00	13/12/2024	REVISIÓN NO OBJETADA - EMITIDO PARA CONSTRUCCIÓN	F.B.R	E.O.M	
VFF	21/08/2024	EMITIDO PARA REVISIÓN Y COMENTARIOS DEL CLIENTE E INTERVENTORÍA - INCLUYE COMENTARIOS /(AJUSTES V3)	F.B.R	E.O.M	
VEE	02/05/2024	EMITIDO PARA REVISIÓN Y COMENTARIOS DEL CLIENTE E INTERVENTORÍA - INCLUYE COMENTARIOS /(AJUSTES V2)	F.B.R	E.O.M	
VDD	18/12/2022	EMITIDO PARA REVISIÓN Y COMENTARIOS DEL CLIENTE E INTERVENTORÍA - INCLUYE COMENTARIOS /(AJUSTES)	J.E.M	M.B.M	
VCC	02/06/2022	EMITIDO PARA REVISIÓN Y COMENTARIOS DEL CLIENTE E INTERVENTORÍA - INCLUYE COMENTARIOS /(ENTREGA 90%)	J.E.M	M.B.M	
VBB	06/12/2021	EMITIDO PARA REVISIÓN Y COMENTARIOS DEL CLIENTE E INTERVENTORÍA	J.E.M	M.B.M	
VA0	30/06/2021	EMITIDO PARA COMENTARIOS INTERNOS - EMISIÓN PRELIMINAR PARA COMENTARIOS	J.E.M	M.B.M	

METRO LÍNEA 1

METRO LÍNEA 1
CONTRATO DE CONCESIÓN No. 163 DE 2019

PROYECTO PRIMERA LÍNEA DEL METRO DE BOGOTÁ - TRAMO 1

DIRECTOR DE INTERVENTORÍA:
JAVIER DESCARGA N.
Mat.:25202-68697 CND

ESPECIALISTA INTERVENTORÍA:
CARLOS ALBERTO HOYOS SOTO
Mat.:A25072000-14251682

FECHA:
MARZO 2026

INFRAESTRUCTURA VIAL

ARQUITECTURA

ESTACIÓN METRO 15 - (CALLE 63)
GENERAL
VISTA EN PLANTA Y 3D - NIVEL PLATAFORMA

PLANCHA No: L1T1-0000-315-CON-ED-ARQ-PL-0001_07_V01
ARCHIVO: L1T1-0000-315-CON-ED-ARQ-MO-0001_V00.rvt
ESCALA: INDICADA
FECHA: JUNIO 2021
REVISIÓN No. V01
PLANO No. 07 DE 94